GOBIERNO DE ESPAÑA
VICEPRESIDENCIA TERCERA DEL GOBIERNO
MINISTERIO PARA LA TRANSICIÓN ECOLÓGICA Y EL RETO DEMOGRÁFICO

Boletín de información nivológica y de peligro de aludes

Pirineo Catalán

aemet Agencia Estatal de Meteorología

jueves, 2 de abril de 2026

Pronóstico hasta las 24 horas del viernes, día 3 de abril

(Válido fuera de pistas de esquí balizadas y abiertas)

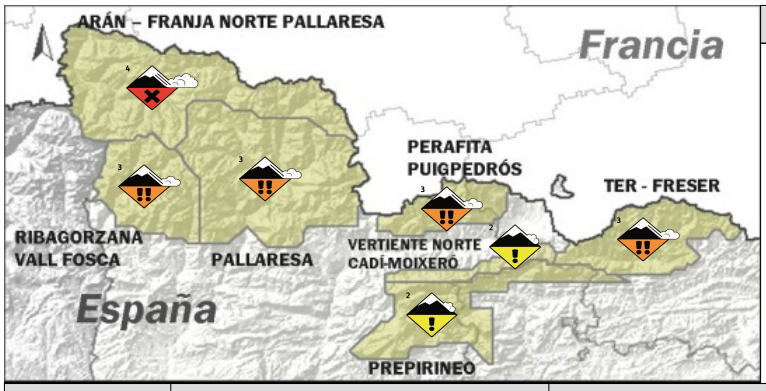

Problemas de aludes

Placas de viento

Nieve reciente

Macizo	Peligro	Problemas de aludes, cota, orientación, tamaño	Innivación observada (m)
Arán - Franja norte Pallaresa	4 / 4 3 1800 Fuerte	Placas de viento: 1800, N O E S, 3 Nieve reciente: N O E S, 3	2026-04-02 N S 1400
Ribagorzana - Vall Fosca	3 / 3 2 1800 Notable	Placas de viento: 1800, N O E S, 3 Nieve reciente: N O E S, 2	2026-04-02 N S 1400
Pallaresa	3 / 3 2 1800 Notable	Placas de viento: 1800, N O E S, 3 Nieve reciente: N O E S, 2	2026-04-02 N S 1400

Boletín de información nivológica y de peligro de aludes

Pirineo Catalán

Perafita - Puigpedrós	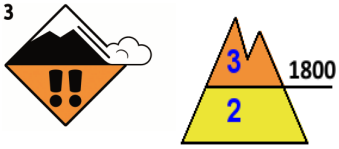 **Notable**	**Placas de viento** 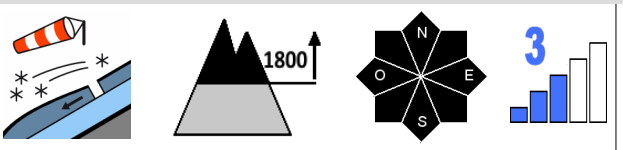 **Nieve reciente** 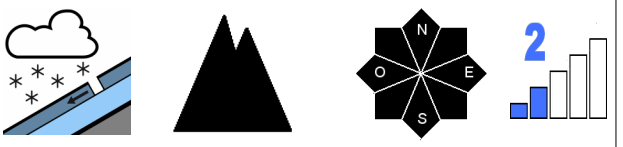	2026-04-02 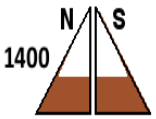
Ter - Freser	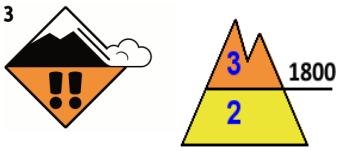 **Notable**	**Placas de viento** 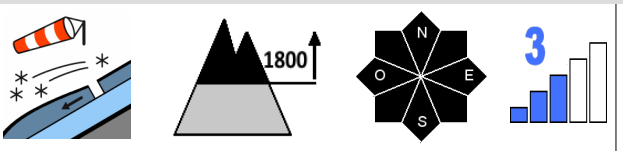 **Nieve reciente** 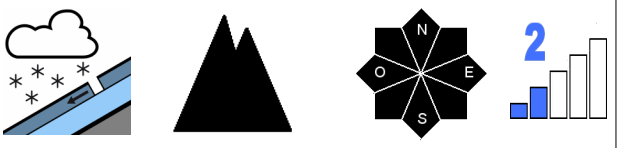	2026-04-02 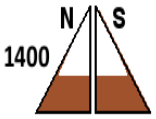
Vertiente norte Cadí - Moixeró	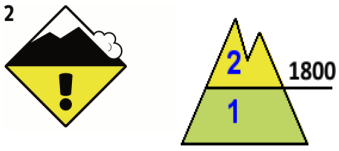 **Limitado**	**Placas de viento** 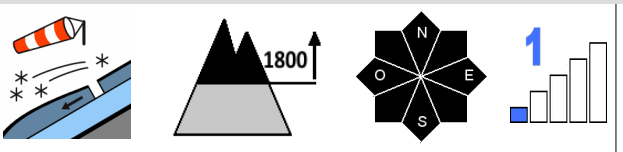 **Nieve reciente** 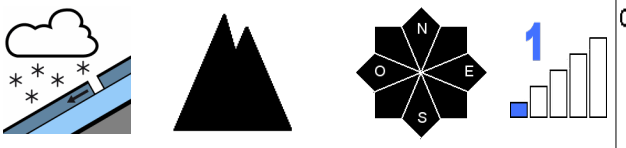	2026-04-02 Cota más baja caras N
Prepirineo	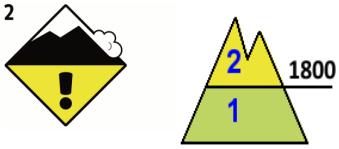 **Limitado**	**Placas de viento** 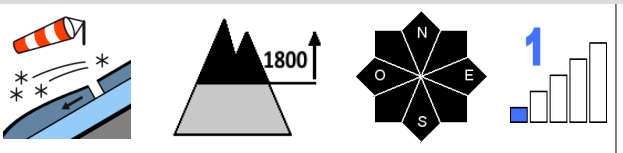 **Nieve reciente** 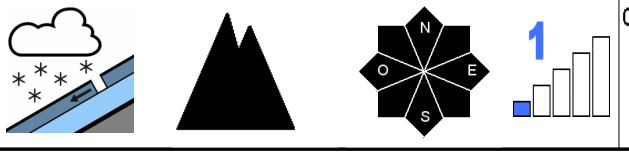	2026-04-02 Cota más baja caras N

Estado del manto y observaciones recientes

Continúan produciéndose precipitaciones en la cordillera, con la cota de nieve en torno a 1300-1500 metros, en muchos casos acompañadas de ventiscas. En las 24 horas anteriores a las 08 UTC de hoy, han caído del orden de 15-40 l/m2 en el Arán y norte de la Pallaresa, zonas próximas a estos y resto de la divisoria, incluso localmente se han alcanzado los 50-70 l/m2 en algunos enclaves, siendo más débiles y ocasionales hacia el sur. Así, se han registrado incrementos importantes en los espesores, que rondan los 15-40 cm por encima de unos 2000-2200 metros.

AEMET. Se autoriza la reproducción de su contenido citando la fuente.

Con los últimos aportes, encontramos nieve a partir de unos 1300-1500 metros, pero con espesores muy discretos. En cambio, a unos 2200-2400 metros se alcanzan los 150-250 cm, valores muy por encima de lo habitual para estas fechas, que se pueden superar ampliamente en ventisqueros y otras zonas propensas a la acumulación.

Durante las nevadas de los últimos días han soplado vientos fuertes o muy fuertes del norte, que han formado numerosas placas en muchas orientaciones, aunque con mayor frecuencia en vertientes sur y suroeste, en ocasiones alejadas de crestas y collados. Antes de este episodio, el manto se encontraba duro y encostrado, con alguna placa de viento antigua en las altas umbrías, y algunas capas débiles persistentes en la base, que se podían mostrar reactivas ante sobrecargas fuertes.

Evolución del manto y peligro de aludes para el viernes, día 3

Problema de nieve reciente, en transición a problema de nieve húmeda en cotas medias y bajas. Problema de placas de viento.

Durante la jornada de hoy, jueves, y primeras horas de mañana van a continuar las nevadas, que serán más copiosas en el valle de Arán y norte de la Pallaresa, donde se podrán depositar otros 20-30 cm nuevos, localmente más, siendo las cantidades menores en el resto. Seguirán soplando fuertes vientos de componente norte, que levantarán ventiscas y redistribuirán la nieve reciente.

Con estas condiciones se formarán nuevas placas de viento, a la vez que van aumentando de tamaño las ya existentes. Serán más frecuentes en vertientes sur, pero las podremos encontrar en todas las orientaciones de cotas medias y altas, incluso alejadas de crestas y collados. Estas estructuras se mantendrán inestables, y podrán colapsar ante una sobrecarga débil (paso de un solo esquiador), provocando aludes de tamaño mediano (capaz de enterrar a una persona) o localmente grande (capaz de dañar un vehículo), sin descartar alguno muy grande en el Arán y norte de la Pallaresa, en mayor medida si los esfuerzos alcanzar niveles internos inestables.

Los nuevos depósitos de nieve nueva se sumarán a las ya caídos en los últimos días, pudiendo producirse purgas de nieve reciente en las laderas suficientemente inclinadas. En general, serán de tamaño pequeño (riesgo de caída) o mediano, si bien localmente podrán ser mayores en las áreas de más acumulación. Con el paso de las horas, el ascenso de las temperaturas y la mayor insolación, sobre todo hacia el sur de los macizos, humificará el manto, por lo que serán esperables aludes de nieve húmeda, principalmente por debajo de unos 2000 metros, siendo más probables en solanas y durante la segunda mitad del día, por lo general de dimensión 1 o 2.

Predicción meteorológica para el viernes, día 3

Predominio de cielos nubosos o muy nubosos en el Arán y norte de la Pallaresa, con nubes bajas que localmente podrán reducir la visibilidad, aunque transitoriamente se abrirán algunos claros. Intervalos nubosos en el resto. Se esperan precipitaciones débiles o localmente moderadas en el Arán y norte de la Pallaresa, principalmente de madrugada y a primeras horas, sin descartar algunas más dispersas y ocasionales en las demás zonas. Cota de nieve en torno a 1300 metros, subiendo por la tarde, hasta alcanzar unos 1900-2000 metros al final

AEMET. Se autoriza la reproducción de su contenido citando la fuente.

del día. Temperaturas en ascenso, ligero en las mínimas y puntualmente notable en las máximas. Heladas débiles, moderadas en cotas altas, donde localmente podrían ser fuertes. Viento de componente norte, fuerte con rachas muy fuertes en cotas altas y zonas expuestas, y moderado con intervalos fuertes en el resto.

Datos en la atmósfera libre:

Altitud de la isoterma de 0 ºC: 2200 m
Altitud de la isoterma de -10 ºC: 4100 m

Viento a 1500 m: NW de 30 km/h a 40 km/h
Viento a 3000 m: N 60 km/h

Evolución para el sábado día 4

Con la abundante insolación y el acusado ascenso de las temperaturas tenderán a disminuir los problemas de nieve reciente y placas de viento, pero aumentará el peligro asociado a la nieve húmeda.

Escala europea de peligro de aludes

Débil | Limitado | Notable | Fuerte | Muy Fuerte

Problemas de aludes

Nieve reciente | Placas de viento | Capas débiles persistentes | Nieve húmeda | Deslizamientos basales | Sin problema evidente

Nota1: Se recuerda que, siempre que haya nieve, la ausencia total de peligro no existe. Hay que tener presente que en circunstancias desfavorables, con aludes de tamaño 1 (alud pequeño o colada) y tamaño 2 (alud mediano), se pueden sufrir severos daños personales.

Nota2: Los BPA se elaboran en base a información meteorológica así como al estado del manto nivoso a través de sondeos puntuales. Se advierte a los usuarios de la variabilidad de esta información al extrapolarla a zonas extensas de montaña. Por ello, AEMET no se hace responsable de su uso para la toma de decisiones que conciernen a la seguridad personal, ni de los riesgos físicos o materiales de ellas derivadas.

AEMET. Se autoriza la reproducción de su contenido citando la fuente.