ICGC Institut Cartogràfic i Geològic de Catalunya

Servei Meteorològic de Catalunya meteo.cat

Boletín de peligro de aludes para el Pirineo de Catalunya
Del 02/04/2026 al 03/04/2026

(Válido fuera pistas de esquí y zonas no controladas)

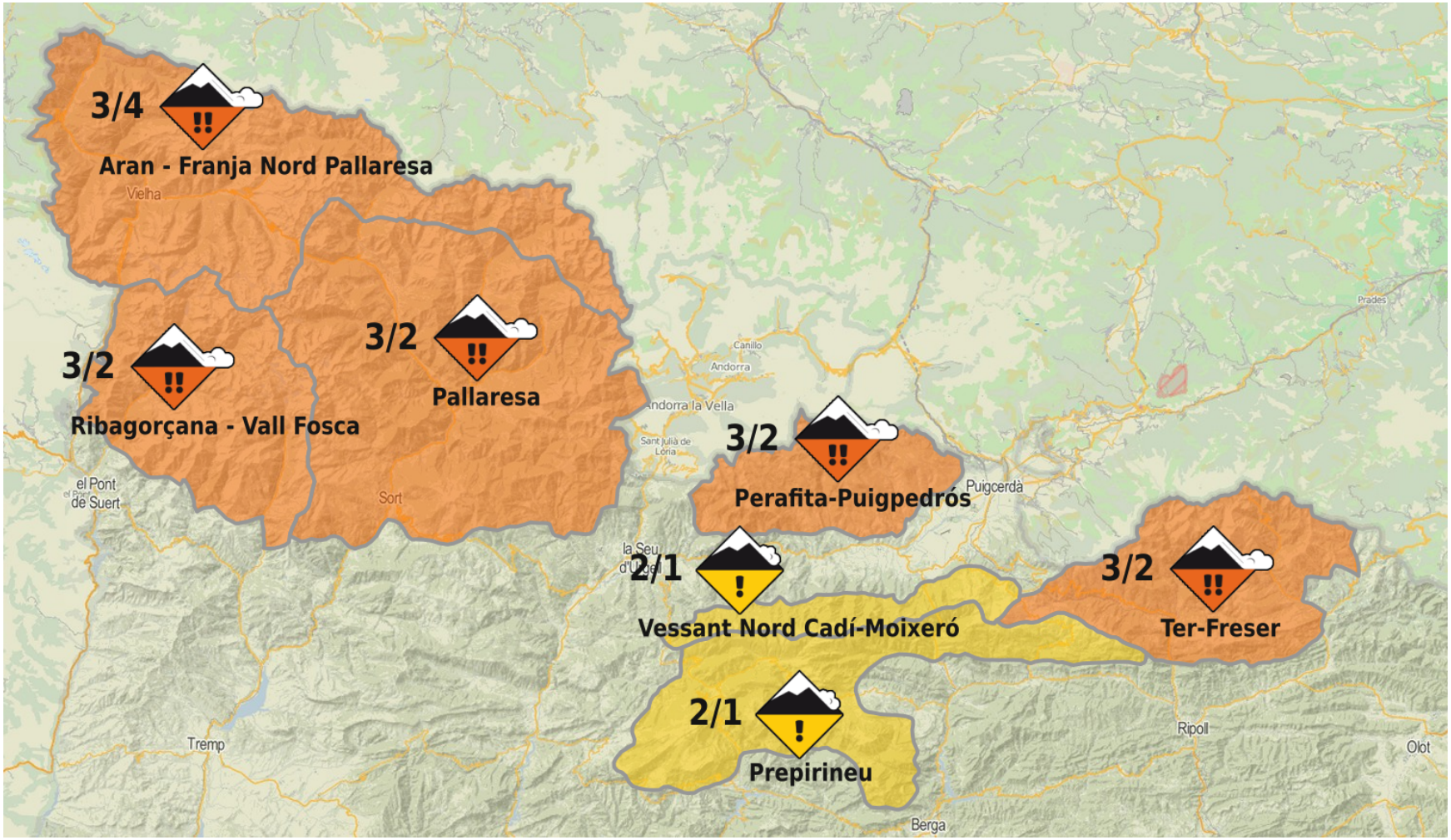

5 MUY FUERTE	4 FUERTE	3 NOTABLE	2 LIMITADO	1 DÉBIL

ICGC Institut Cartogràfic i Geològic de Catalunya

Servei Meteorològic de Catalunya meteo.cat

Boletín de peligro de aludes Aran - Franja Nord Pallaresa Del 02/04/2026 al 03/04/2026

(Válido fuera pistas de esquí y zonas no controladas)

NOTABLE (3) a partir del jueves por la tarde. FUERTE (4) hasta entonces.

Situación primaria

Nieve venteada

Distribución

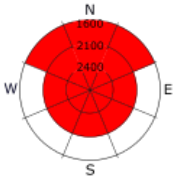

Tamaño

Origen

Tendencia

Situación secundaria

Nieve húmeda

Distribución

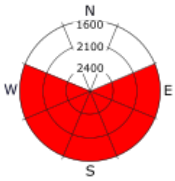

Tamaño

Origen

Tendencia

Estado del manto nivoso

La tarde del jueves todavía serán probables aludes naturales de tamaño 3 (suficiente para enterrar a un grupo de personas) en forma de placas de viento, o incluso mayores en la Franja Norte de la Pallaresa. A partir de entonces y durante toda la jornada del viernes, los aludes naturales de placa de viento serán menos probables pero todavía será muy probable desencadenarlos al paso de una persona. Se sitúan en los sotaventos de cualquier orientación, si bien las más grandes se encuentran en terreno soleado. Durante la jornada del viernes las más sensibles serán las que se encuentran en terreno umbrío. El viernes, además, serán muy frecuentes los aludes de nieve húmeda, debido a la insolación y al incremento de temperaturas previsto. Afectarán a las vertientes más soleadas y alcanzarán fácilmente tamaño 2 (suficiente para enterrar a una persona) o incluso mayores. Se recomienda una selección muy cuidadosa del itinerario para realizar actividad en nieve el viernes.

Distribución del manto nivoso

El actual episodio de nevadas ha encalado el suelo por encima de unos 1.400 m. Los espesores a unos 2.200 m son ligeramente superiores a los normales en la Franja Norte de la Pallaresa y en la mitad sur de Arán, donde rondan los 200-240 cm. En la mitad norte de Arán son los normales por estas fechas con unos 150-170 cm de espesor total.

Tendencia para las próximas 48-72h

Continuarán imponiéndose las condiciones de primavera, con rehielo matinal y humidificación del manto a lo largo de la jornada. La actividad de aludes se prevé menor a días anteriores. Peligro EN DESCENSO.

El próximo boletín será emitido el día 2026-04-03

5 MUY FUERTE	4 FUERTE	3 NOTABLE	2 LIMITADO	1 DÉBIL

EAWS EUROPEAN AVALANCHE WARNING SERVICES

ICGC Institut Cartogràfic i Geològic de Catalunya

Servei Meteorològic de Catalunya

Boletín de peligro de aludes Ribagorçana - Vall Fosca Del 02/04/2026 al 03/04/2026

(Válido fuera pistas de esquí y zonas no controladas)

NOTABLE (3) en la mitad norte por encima del nivel del bosque. LIMITADO (2) en el resto.

Situación primaria

Nieve venteada

Distribución

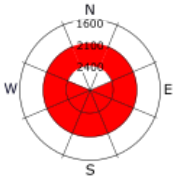

Tamaño

Origen

Tendencia

Situación secundaria

Nieve húmeda

Distribución

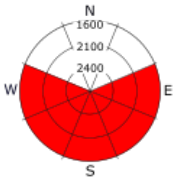

Tamaño

Origen

Tendencia

Estado del manto nivoso

Actualmente existen placas de viento en lugares protegidos de todas las orientaciones. Se trata de acumulaciones locales, más abundantes y de mayor tamaño en la mitad norte del sector, y que pueden desprenderse al paso de una persona. El viernes, con el paso de las horas, las placas situadas en terreno soleado serán menos sensibles, pero serán aún sensibles a desprenderse a nuestro paso a terreno umbrío todo el día. En caso de caer, los aludes podrán alcanzar tamaño 2 o, de forma local, tamaño 3 (suficiente para enterrar a un grupo de personas) en sotaventos muy claros del norte del sector. El viernes, con la insolación y el incremento de temperatura serán frecuentes los aludes de nieve húmeda, por lo general de tamaño 1, suficiente para generar caídas y lesiones, pero que podrían alcanzar tamaño 2 en el norte del sector.

Distribución del manto nivoso

Aunque hay nieve desde unos 1.400 m por el último episodio de nevadas, la nieve presenta cierta continuidad a partir de 1.700 m en terreno umbrío y de 1.900 m solanas. Los grosores alcanzan los 100-120 cm a unos 2.200 m, con frecuentes deflaciones y acumulaciones por encima del nivel del bosque. Estos valores se acercan a los normales para la época.

Tendencia para las próximas 48-72h

Se espera un patrón de fusión diurna y rehielo nocturno, con algunos aludes superficiales de nieve húmeda durante el día. Peligro EN DESCENSO.

El próximo boletín será emitido el día 2026-04-03

5 MUY FUERTE	4 FUERTE	3 NOTABLE	2 LIMITADO	1 DÉBIL

EAWS EUROPEAN AVALANCHE WARNING SERVICES

ICGC Institut Cartogràfic i Geològic de Catalunya

meteo.cat Servei Meteorològic de Catalunya

Boletín de peligro de aludes Pallaresa
Del 02/04/2026 al 03/04/2026

(Válido fuera pistas de esquí y zonas no controladas)

NOTABLE (3) en la mitad norte por encima del nivel del bosque. LIMITADO (2) en el resto.

Situación primaria

Nieve venteada

Distribución

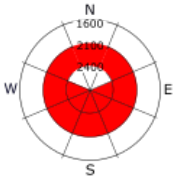

Tamaño

Origen

Tendencia

Situación secundaria

Nieve húmeda

Distribución

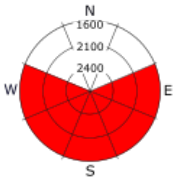

Tamaño

Origen

Tendencia

Estado del manto nivoso

Actualmente existen placas de viento en lugares protegidos de todas las orientaciones. Se trata de acumulaciones locales, más abundantes y de mayor tamaño en la mitad norte del sector, y que pueden desprenderse al paso de una persona. El viernes, con el paso de las horas, las placas situadas en terreno soleado serán menos sensibles, pero serán aún sensibles a desprenderse a nuestro paso a terreno umbrío todo el día. En caso de caer, los aludes podrán alcanzar tamaño 2 o, de forma local, tamaño 3 (suficiente para enterrar a un grupo de personas) en sotaventos muy claros del norte del sector. El viernes, con la insolación y el incremento de temperatura serán frecuentes los aludes de nieve húmeda, por lo general de tamaño 1, suficiente para generar caídas y lesiones, pero que podrían alcanzar tamaño 2 en el norte del sector.

Distribución del manto nivoso

Aunque hay nieve desde unos 1.300 m por último episodio de nevadas, la nieve presenta cierta continuidad por encima de 1.700 ma terreno umbrío y de 1.900 ma solanas. Los espesores alcanzan los 110-150 cm en cotas medias, con frecuentes acumulaciones y deflaciones por encima del nivel del bosque.

Tendencia para las próximas 48-72h

Condiciones de primavera, con rehielo matinal y fusión superficial con la insolación y las elevadas temperaturas. Se espera menos aludes de nieve húmeda que días atrás. Peligro EN DESCENSO.

El próximo boletín será emitido el día 2026-04-03

5 MUY FUERTE	4 FUERTE	3 NOTABLE	2 LIMITADO	1 DÉBIL

EAWS EUROPEAN AVALANCHE WARNING SERVICES

ICGC Institut Cartogràfic i Geològic de Catalunya

Servei Meteorològic de Catalunya

Boletín de peligro de aludes Perafita-Puigpedrós Del 02/04/2026 al 03/04/2026

(Válido fuera pistas de esquí y zonas no controladas)

NOTABLE (3) por encima del nivel del bosque. LIMITADO (2) por debajo.

Situación primaria

Nieve venteada

Distribución

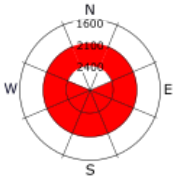

Tamaño

Origen

Tendencia

Situación secundaria

Nieve húmeda

Distribución

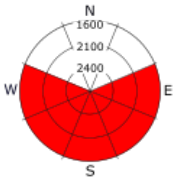

Tamaño

Origen

Tendencia

Estado del manto nivoso

Actualmente hay placas de viento en el sector, ubicadas a sotaventos de las diferentes orientaciones. Se trata de placas duras, por lo general, pero sensibles al desencadenamiento al paso de una persona, las más gruesas a orientaciones sur. A lo largo de la jornada del viernes, con la insolación y el incremento de la temperatura, las placas se convertirán en más estables y su desencadenamiento accidental será menos probable en terreno soleado, pero habrá que prestar atención todavía a umbrías. En caso de caer se tratará de aludes de tamaño 2, suficiente para enterrar a una persona, aunque no se descartan mayores a sotaventos muy claros. La nieve humedecerá el viernes por el sol y el incremento de temperatura, dando lugar a purgas de nieve húmeda en muchas vertientes, que afectarán sobre todo a la nieve de los últimos episodios, es decir, la que queda por encima de la corteza marrón. No se descarta algún alud de nieve húmeda de tamaño 2.

Distribución del manto nivoso

Hay nieve por encima de 1.400 m por las últimas nevadas, con cierta continuidad por encima de unos 1.900 m, y de 2.200 m en solanas. Es esquiable a partir de unos 2.000 m en N. Los espesores, aunque irregulares, rondan los 80-120 cm en umbrías, a 2.300 m; existen frecuentes deflaciones y acumulaciones por encima del nivel del bosque. Son grosores por encima de los habituales en esta época.

Tendencia para las próximas 48-72h

Manto endurecido por rehielo por la mañana y transformando por fusión a lo largo de la jornada. Se espera una menor actividad de aludes de nieve húmeda que días atrás. Peligro EN DESCENSO.

El próximo boletín será emitido el día 2026-04-03

5 MUY FUERTE	4 FUERTE	3 NOTABLE	2 LIMITADO	1 DÉBIL

EAWS EUROPEAN AVALANCHE WARNING SERVICES

ICGC Institut Cartogràfic i Geològic de Catalunya

Servei Meteorològic de Catalunya meteo.cat

Boletín de peligro de aludes Vessant Nord Cadí-Moixeró Del 02/04/2026 al 03/04/2026

(Válido fuera pistas de esquí y zonas no controladas)

LIMITADO (2) en el Moixeró por encima del nivel del bosque.
DÉBIL (1) en el resto.

Situación primaria

Nieve venteada

Distribución

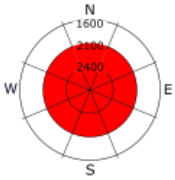

Tamaño

Origen

Tendencia

Situación secundaria

Nieve húmeda

Distribución

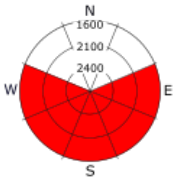

Tamaño

Origen

Tendencia

Estado del manto nivoso

Actualmente hay placas de viento, principalmente en el Moixeró, ya que en el Cadí las nevadas han sido muy escasas. Se trata de placas duras pero lo suficientemente delgadas para ser desencadenadas al paso de una sola persona. Se encuentran principalmente en sotaventos orientados a sur y este, pero también a zonas muy resguardadas del viento del resto de orientaciones. En caso de desprenderse se tratará de aludes de hasta tamaño 2, suficiente para enterrar a una persona. Con el paso de las horas del viernes, las placas tenderán a presentarse menos inestables en terreno soleado. Se espera que el viernes el manto humedezca sustancialmente a causa de la insolación y el incremento de temperaturas. Podría haber aludes que afectarán sobre todo a la nieve más reciente, blanda y superficial, proveniente del episodio entre el martes y el miércoles. Los posibles aludes tendrán lugar en el terreno más soleado y serán por lo general de tamaño 1, suficiente para producir caídas y lesiones.

Distribución del manto nivoso

Podemos encontrar una delgada capa de nieve a 1.700 m por el último episodio de nevadas, pero en solanas el manto no es continuo hasta unos 1.900 m. Los grosores están alrededor de 160-180 cm a 2.200 m, con algunas acumulaciones y deflaciones por encima del nivel del bosque. Estos valores son muy excedentarios para la época del año.

Tendencia para las próximas 48-72h

Manto endurecido por rehielo por la mañana y transformando por fusión a lo largo de la jornada. Se espera una menor actividad de aludes de nieve húmeda que días atrás. Peligro EN DESCENSO.

El próximo boletín será emitido el día 2026-04-03

5 MUY FUERTE	4 FUERTE	3 NOTABLE	2 LIMITADO	1 DÉBIL

EAWS EUROPEAN AVALANCHE WARNING SERVICES

ICGC Institut Cartogràfic i Geològic de Catalunya

Servei Meteorològic de Catalunya

Boletín de peligro de aludes Prepirineu
Del 02/04/2026 al 03/04/2026

(Válido fuera pistas de esquí y zonas no controladas)

LIMITADO (2) en el Moixeró por encima del nivel del bosque.
DÉBIL (1) en el resto.

Situación primaria

Nieve venteada

Distribución

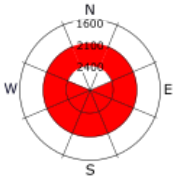

Tamaño

Origen

Tendencia

Situación secundaria

Nieve húmeda

Distribución

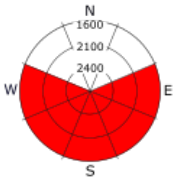

Tamaño

Origen

Tendencia

Estado del manto nivoso

Actualmente hay placas de viento, principalmente en el Moixeró, ya que en el Cadí las nevadas han sido muy escasas. Se trata de placas duras pero lo suficientemente delgadas para ser desencadenadas al paso de una sola persona. Se encuentran principalmente en sotaventos orientados a sur y este, pero también a zonas muy resguardadas del viento del resto de orientaciones. En caso de desprenderse se tratará de aludes de hasta tamaño 2, suficiente para enterrar a una persona. Con el paso de las horas del viernes, las placas tenderán a presentarse menos inestables en terreno soleado. Se espera que el viernes el manto humedezca sustancialmente a causa de la insolación y el incremento de temperaturas. Podría haber aludes que afectarán sobre todo a la nieve más reciente, blanda y superficial, proveniente del episodio entre el martes y el miércoles. Los posibles aludes tendrán lugar en el terreno más soleado y serán por lo general de tamaño 1, suficiente para producir caídas y lesiones.

Distribución del manto nivoso

Aunque podemos encontrar nieve en cotas más bajas por último episodio de nevadas, el manto es continuo por encima de unos 1.700 ma terreno umbrío y de unos 1.900 ma solanas. Los espesores, aunque irregulares, rondan los 90-120 cm a 2.300 m.

Tendencia para las próximas 48-72h

Condiciones típicamente primaverales, con manto endurecido a primera hora y humedecimiento, y algunos aludes de fusión, a lo largo de las horas de sol. Peligro EN DESCENSO.

El próximo boletín será emitido el día 2026-04-03

5 MUY FUERTE	4 FUERTE	3 NOTABLE	2 LIMITADO	1 DÉBIL

EAWS EUROPEAN AVALANCHE WARNING SERVICES

ICGC Institut Cartogràfic i Geològic de Catalunya

meteo.cat Servei Meteorològic de Catalunya

Boletín de peligro de aludes Ter-Freser
Del 02/04/2026 al 03/04/2026

(Válido fuera pistas de esquí y zonas no controladas)

NOTABLE (3) por encima del nivel del bosque. LIMITADO (2) por debajo.

Situación primaria

Nieve venteada

Distribución

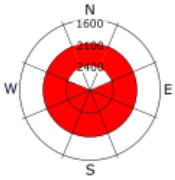

Tamaño

Origen

Tendencia

Situación secundaria

Nieve húmeda

Distribución

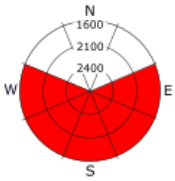

Tamaño

Origen

Tendencia

Estado del manto nivoso

Actualmente hay placas de viento en el sector, ubicadas a sotaventos de las diferentes orientaciones. Se trata de placas duras, por lo general, pero sensibles al desencadenamiento al paso de una persona, las más gruesas a orientaciones sur. A lo largo de la jornada del viernes, con la insolación y el incremento de la temperatura, las placas se convertirán en más estables y su desencadenamiento accidental será menos probable en terreno soleado, pero habrá que prestar atención todavía a umbrías. En caso de caer se tratará de aludes de tamaño 2, suficiente para enterrar a una persona, aunque no se descartan mayores a sotaventos muy claros. La nieve humedecerá el viernes por el sol y el incremento de temperatura, dando lugar a purgas de nieve húmeda en muchas vertientes, que afectarán sobre todo a la nieve de los últimos episodios, es decir, la que queda por encima de la corteza marrón. No se descarta algún alud de nieve húmeda de tamaño 2.

Distribución del manto nivoso

Hay algo de nieve en el suelo por encima de unos 1.400 m por el último episodio de nevadas. El manto es esquiable a umbrías a partir de unos 1.800 m en umbrías. Los grosores son muy excedentarios para la época del año y en lugares no afectados por el viento oscilan entre 70-100 cm a unos 2.000 m, y más de 150 cm por encima de 2.400 m, muy variable por los efectos del viento.

Tendencia para las próximas 48-72h

Condiciones típicamente primaverales, con manto endurecido a primera hora y humedecimiento, y algunos aludes de fusión, a lo largo de las horas de sol. Peligro EN DESCENSO.

El próximo boletín será emitido el día 2026-04-03

5 MUY FUERTE	4 FUERTE	3 NOTABLE	2 LIMITADO	1 DÉBIL

EAWS EUROPEAN AVALANCHE WARNING SERVICES