BUTLLETÍ DEL PERILL D'ALLAUS DEL PRINCIPAT D'ANDORRA

Servei meteorològic nacional
Principat d'Andorra

Elaborat el 02/04/2026 16:00
Propera actualització 03/04/2026 a les 16h

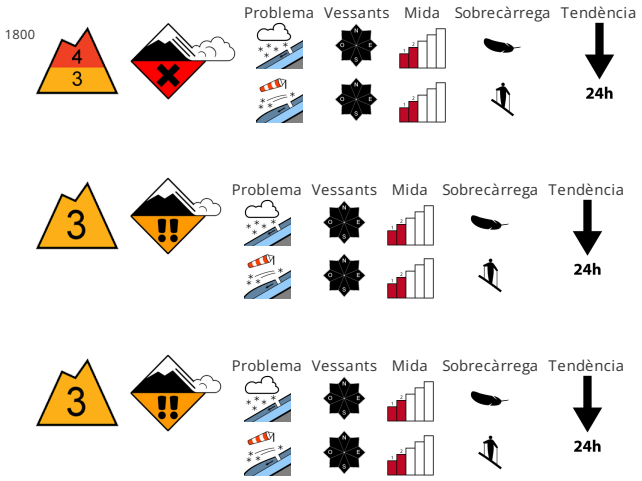

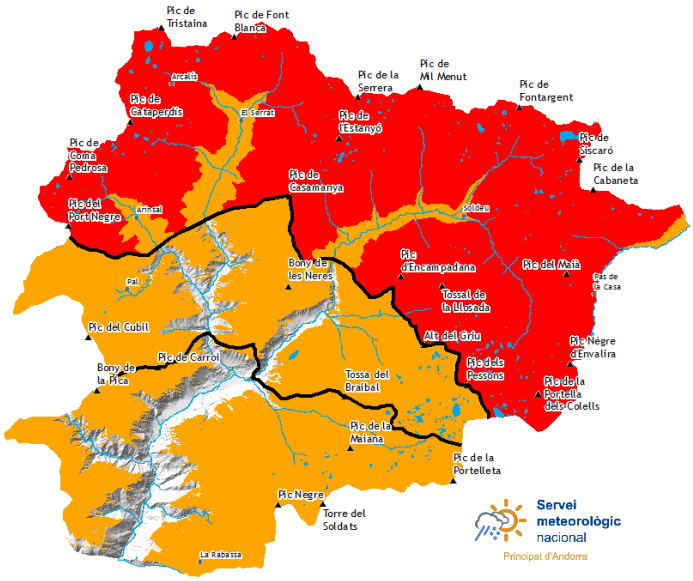

ESTABILITAT DEL MANTELL NIVAL

Amb la fi de les precipitacions, afebliment progressiu del perill d'allaus de neu seca. El vent amb ratxes fortes ha transportat intensament la neu recent i la neu vella. Les zones de sortida han estat novament carregades. La neu recent abundant i les plaques de vent poden fàcilment desencadenar-se de manera natural o accidental. Les allaus són com a mínim de mida mitjana. Els indrets perillosos són força freqüents i difícils de reconèixer. Les condicions per les excursions són desfavorables. Per ara, les activitats d'esports d'hivern fora de les pistes controlades són desaconsellables. Després d'un període de mal temps, en aquest primer dia de sol es recomana prudència.

QUALITAT DE LA NEU

Des del dimarts ha caigut molta neu sobretot als al nord. Les noves acumulacions de neu ventada descansen a sobre de capes toves. El mantell de neu roman extremadament variable en pocs metres de manera generalitzada. Prop de les carenes els gruixos de neu varien molt per la influència del vent. Amb la pujada de temperatures la radiació solar, durant els propers dies el mantell de neu s'assentarà.

GRUIXOS DEL MANTELL NIVAL FORA DE PISTA

Zona nord		Gruix neu		
Mantell Nival		1500m	2000m	2500m
N	1300 m	20 cm	180 cm	250 cm
S	1300 m	10 cm	150 cm	200 cm

Zona centre		Gruix neu		
Mantell Nival		1500m	2000m	2500m
N	1300 m	10 cm	150 cm	200 cm
S	1500 m	5 cm	100 cm	150 cm

Zona sud		Gruix neu		
Mantell Nival		1500m	2000m	2500m
N	1300 m	10 cm	120 cm	160 cm
S	1500 m	5 cm	60 cm	120 cm

Govern d'Andorra

EAWS
EUROPEAN AVALANCHE WARNING SERVICES

Aquest butlletí ha estat elaborat seguint les normes i recomanacions de l'**European Avalanche Warning Services**, del qual el **Servei meteorològic Nacional** n'és membre

BUTLLETÍ DEL PERILL D'ALLAUS DEL PRINCIPAT D'ANDORRA

Servei meteorològic nacional
Principat d'Andorra

Informació detallada per espais naturals protegits

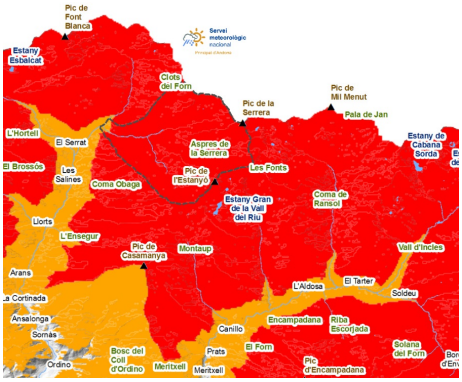

SORTENY

El vent ha modelat la neu recent i ho continuarà fent durant les properes hores.A causa de les nevades successives que sobretot han afectat el nord d´Andorra trobem condicions hivernals. A l´interior del bosc la possibilitat de desencadenament d´allaus és baixa, però a les parets verticals dels circs podem desencadenar allaus de placa.

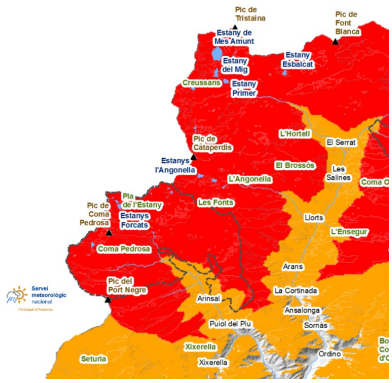

COMAPEDROSA

Es preveu que el vent encara sigui intens en altura durant les properes hores i es continuïn formant plaques de vent, ocultes sota la neu recent de dimecres i dijous i difícilment identificables. La situació és desfavorable per a les excursions.

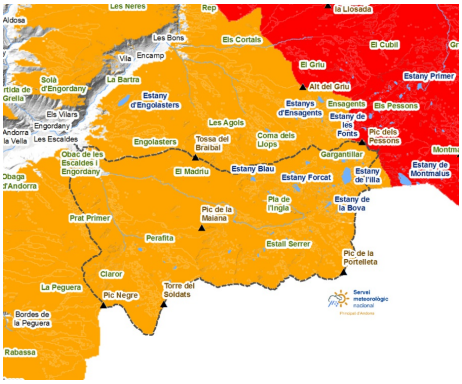

MADRIU-PERAFITA-CLAROR

La neu recent recula ràpid de les cotes baixes de la vall, però a cotes altes l´ambient encara és hivernal. Haurem de circular amb molta precaució, mantenint la distància de seguretat.

Govern d'Andorra

EAWS
EUROPEAN AVALANCHE WARNING SERVICES

Aquest butlletí ha estat elaborat seguint les normes i recomanacions de l'**European Avalanche Warning Services**, del qual el **Servei meteorològic Nacional** n'és membre

BUTLLETÍ DEL PERILL D'ALLAUS DEL PRINCIPAT D'ANDORRA

Servei meteorològic nacional
Principat d'Andorra

Gruixos de neu nova dels darrers dies (de les últimes 24h mesurat a les 06:00h UTC)

	29/03/2026	30/03/2026	31/03/2026	01/04/2026
FEDA (Central)	0 cm	0 cm	0 cm	0 cm
Engolasters - FEDA	0 cm	0 cm	0 cm	7 cm
Bony de les Neres	0 cm	0 cm	3 cm	22 cm
Les Fonts d'Arinsal	0 cm	7 cm	1 cm	22 cm
Perafita	0 cm	0 cm	6 cm	17 cm
Tossa Espiolets	0 cm	4 cm	0 cm	12 cm
Grau Roig - FEDA	0 cm	1 cm	7 cm	34 cm
Fontverd	0 cm	0 cm	0 cm	27 cm
Coll Ordino	0 cm	0 cm	4 cm	18 cm
Ransol - FEDA	0 cm	3 cm	6 cm	20 cm
Setúria	0 cm	2 cm	0 cm	12 cm
Caborreu	0 cm	5 cm	1 cm	21 cm
La Solana	9 cm	6 cm	11 cm	44 cm
Coll Pa	0 cm	3 cm	7 cm	8 cm
Vall del Riu FEDA	0 cm	1 cm	5 cm	48 cm