BUTLLETÍ DEL PERILL D'ALLAUS DEL PRINCIPAT D'ANDORRA

Servei meteorològic nacional
Principat d'Andorra

Elaborado el 02/04/2026 16:00
Proxima actualización 03/04/2026 a las 16h

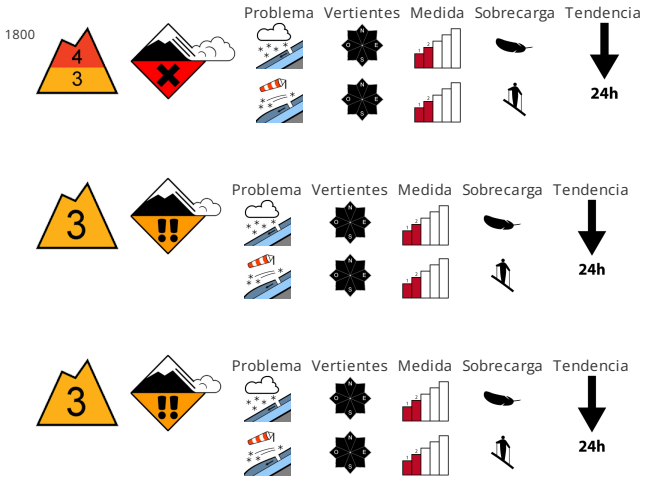

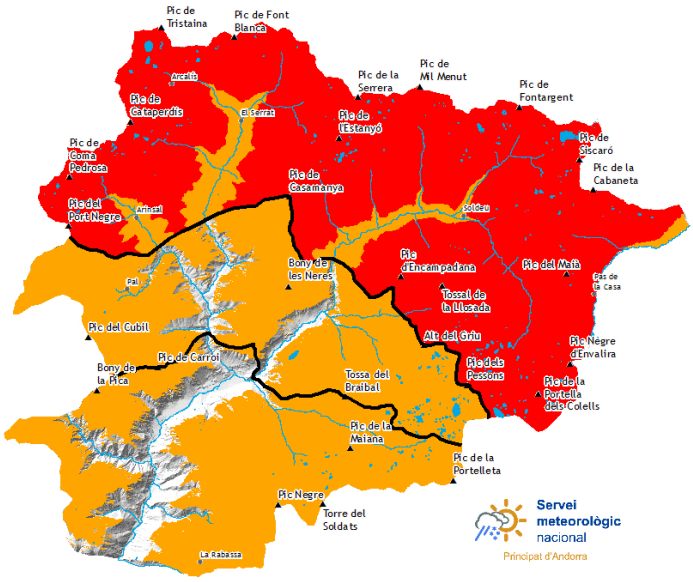

CALIDAD DE LA NIEVE

Con el fin de las precipitaciones, progresivo descenso del peligro de aludes de nieve seca. El viento con rachas fuertes ha transportado intensamente la nieve reciente y la nieve antigua. Las zonas de salida se han visto nuevamente cargadas. La nieve reciente abundante y las placas de viento pueden fácilmente desencadenarse de manera natural o accidental. Los aludes son como mínimo de tamaño mediano. Los lugares peligrosos son bastante frecuentes y resultan difíciles de reconocer. Las condiciones para las excursiones son desfavorables. Por ahora, las actividades de deportes de invierno fuera de las pistas controladas están desaconsejadas. Tras el período de mal tiempo, en este primer día de sol se recomienda prudencia.

ESTABILIDAD DEL MANTO NIVOSO

Desde el martes ha caído mucha nieve sobre todo en los norte. Las nuevas acumulaciones de nieve venteada descansan encima de capas blandas. El manto de nieve permanece extremadamente variable en pocos metros en general. Cerca de los cordales los espesores de nieve varían mucho por la influencia del viento. Con la subida de temperaturas la radiación solar, durante los próximos días el manto de nieve se asentará.

ESPESORES DEL MANTO NIVOSO FUERA DE PISTA

Zona norte		Espesor nieve		
Manto Nival		1500m	2000m	2500m
N	1300 m	20 cm	180 cm	250 cm
S	1300 m	10 cm	150 cm	200 cm

zona centro		Espesor nieve		
Manto Nival		1500m	2000m	2500m
N	1300 m	10 cm	150 cm	200 cm
S	1500 m	5 cm	100 cm	150 cm

Zona sur		Espesor nieve		
Manto Nival		1500m	2000m	2500m
N	1300 m	10 cm	120 cm	160 cm
S	1500 m	5 cm	60 cm	120 cm

Govern d'Andorra

EAWS
EUROPEAN AVALANCHE WARNING SERVICES

Aquest butlletí ha estat elaborat seguint les normes i recomanacions de l'**European Avalanche Warning Services**, del qual el **Servei meteorològic Nacional** n'és membre

BUTLLETÍ DEL PERILL D'ALLAUS DEL PRINCIPAT D'ANDORRA

Servei meteorològic nacional
Principat d'Andorra

Información detallada por espacios naturales protegidos

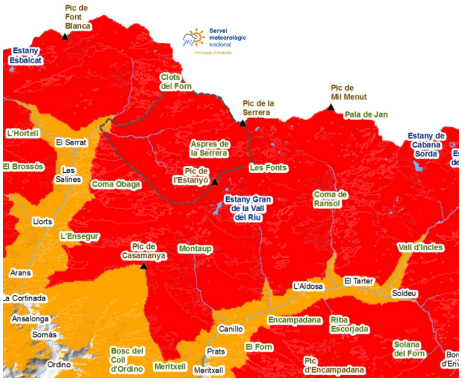

SORTENY

El viento ha moldeado la nieve reciente y lo seguirá haciendo durante las próximas horas. Debido a las sucesivas nevadas que sobre todo han afectado al norte de Andorra encontramos condiciones invernales. En el interior del bosque la posibilidad de desencadenamiento de aludes es baja, pero en las paredes verticales de los circos podemos desencadenar aludes de placa.

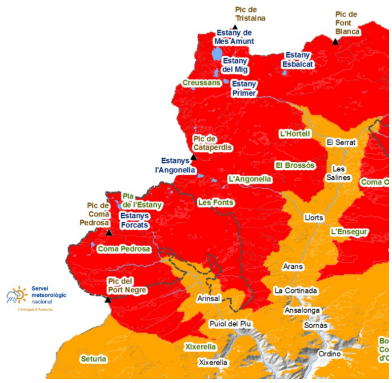

COMAPEDROSA

Se prevé que el viento sea aún intenso en altura durante las próximas horas y se sigan formando placas de viento, ocultas bajo la nieve reciente del miércoles y jueves y difícilmente identificables. La situación resulta desfavorable para las excursiones.

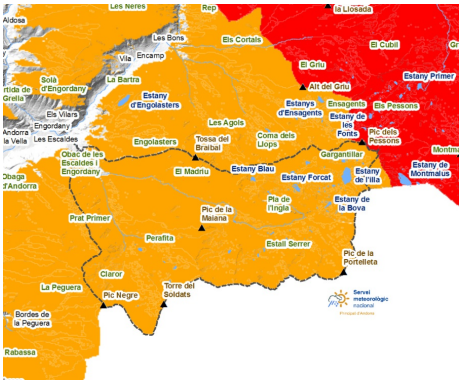

MADRIU-PERAFITA-CLAROR

La nieve reciente retrocede rápidamente de las cotas bajas del valle, pero en cotas altas el ambiente es aún invernal. Deberemos circular con mucha precaución, manteniendo la distancia de seguridad.

Govern d'Andorra

EAWS
EUROPEAN AVALANCHE WARNING SERVICES

Aquest butlletí ha estat elaborat seguint les normes i recomanacions de l'**European Avalanche Warning Services**, del qual el **Servei meteorològic Nacional** n'és membre

BUTLLETÍ DEL PERILL D'ALLAUS DEL PRINCIPAT D'ANDORRA

Servei meteorològic nacional
Principat d'Andorra

Espesores de nieve nueva de los últimos días (de las ultimas 24h mesurado a las 06:00h UTC)

	29/03/2026	30/03/2026	31/03/2026	01/04/2026
FEDA (Central)	0 cm	0 cm	0 cm	0 cm
Engolasters - FEDA	0 cm	0 cm	0 cm	7 cm
Bony de les Neres	0 cm	0 cm	3 cm	22 cm
Les Fonts d'Arinsal	0 cm	7 cm	1 cm	22 cm
Perafita	0 cm	0 cm	6 cm	17 cm
Tossa Espiolets	0 cm	4 cm	0 cm	12 cm
Grau Roig - FEDA	0 cm	1 cm	7 cm	34 cm
Fontverd	0 cm	0 cm	0 cm	27 cm
Coll Ordino	0 cm	0 cm	4 cm	18 cm
Ransol - FEDA	0 cm	3 cm	6 cm	20 cm
Setúria	0 cm	2 cm	0 cm	12 cm
Caborreu	0 cm	5 cm	1 cm	21 cm
La Solana	9 cm	6 cm	11 cm	44 cm
Coll Pa	0 cm	3 cm	7 cm	8 cm
Vall del Riu FEDA	0 cm	1 cm	5 cm	48 cm