BUTLLETÍ DEL PERILL D'ALLAUS DEL PRINCIPAT D'ANDORRA

Préparé le 02/04/2026 16:00
Prochaine mise à jour le 03/04/2026 à 16h

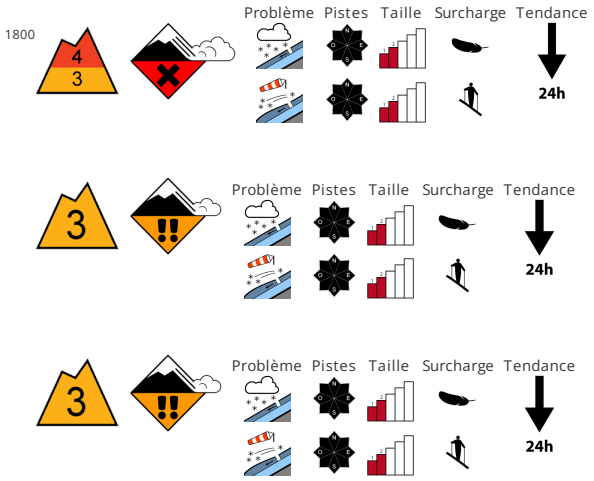

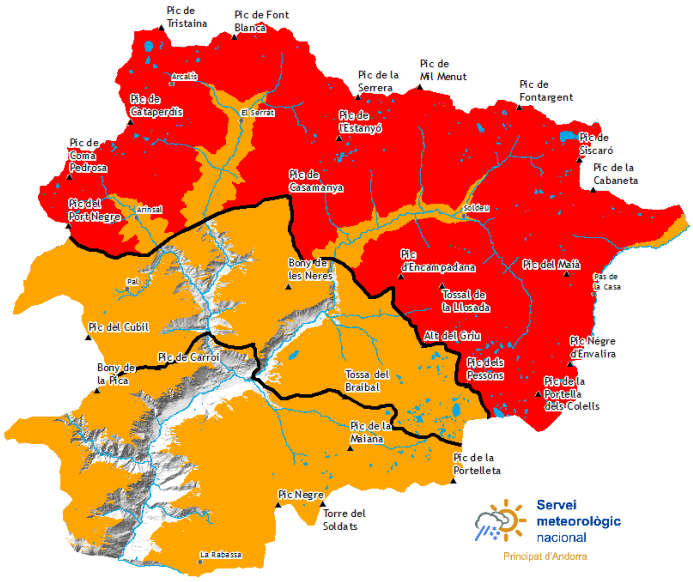

STABILITÉ DU MANTEAU NEIGEUX

Diminution progressive du danger d'avalanches sèches avec la fin des précipitations. Le vent parfois fort a transporté intensivement la neige fraîche et la neige ancienne.. Les zones de départ ont été à nouveau rechargées. La neige fraîche très abondante et les accumulations de neige soufflée peuvent être déclenchées facilement ou glisser spontanément. Les avalanches sont généralement de taille moyenne. Les endroits dangereux sont assez fréquents et difficilement identifiables.. Les conditions de randonnées sont défavorables. Il est déconseillé d'effectuer des sports d'hiver en dehors des pistes sécurisées. Après une longue période de mauvais temps, la retenue est de mise pour cette première journée ensoleillée..

QUALITÈ DE LA NEIGE

Depuis mardi il est tombé beaucoup de neige surtout au nord. Les accumulations récentes de neige soufflée reposent sur des couches meubles. De manière généralisée le manteau neigeux reste très variable à petite échelle.. À proximité des crêtes on trouve suivant l'influence du vent des hauteurs de neiges très différentes. Avec le réchauffement le rayonnement solaire le manteau neigeux se tasse dans les prochains jours.

EPAISSEUR DE NEIGE HORS PISTE

Zone nord		Epaisseur de neige		
Nival manteau		1500m	2000m	2500m
N	1300 m	20 cm	180 cm	250 cm
S	1300 m	10 cm	150 cm	200 cm

Zone centre		Epaisseur de neige		
Nival manteau		1500m	2000m	2500m
N	1300 m	10 cm	150 cm	200 cm
S	1500 m	5 cm	100 cm	150 cm

Zone sud		Epaisseur de neige		
Nival manteau		1500m	2000m	2500m
N	1300 m	10 cm	120 cm	160 cm
S	1500 m	5 cm	60 cm	120 cm

BUTLLETÍ DEL PERILL D'ALLAUS DEL PRINCIPAT D'ANDORRA

Servei meteorològic nacional
Principat d'Andorra

Des informations détaillées par espace naturel protégé

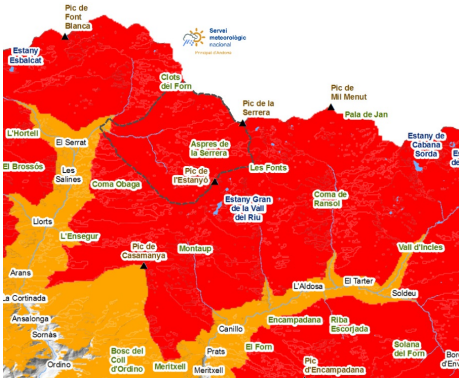

SORTENY

Le vent a façonné la neige récente et continuera de le faire au cours des prochaines heures. En raison des chutes de neige successives qui ont principalement touché le nord d'Andorre, nous connaissons des conditions hivernales. A l'intérieur de la forêt, la possibilité de déclenchement d'avalanches est faible, mais sur les parois verticales des cirques, des avalanches de plaques peuvent se déclencher. , , , ,

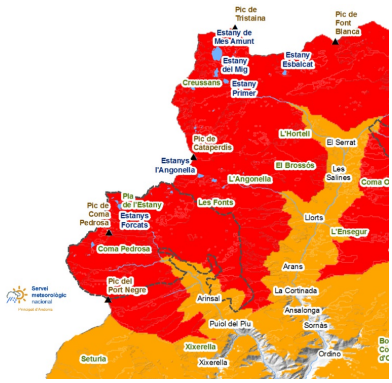

COMAPEDROSA

Les vents devraient rester forts en altitude au cours des prochaines heures et des plaques de vent continueront de se former, cachées sous la neige récente de mercredi et jeudi et difficiles à identifier. La situation est défavorable aux excursions. , , , ,

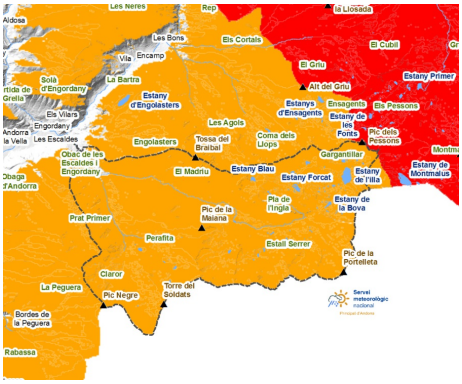

MADRIU-PERAFITA-CLAROR

La neige récente recule rapidement dans les basses altitudes de la vallée, mais à des altitudes plus élevées, l'atmosphère est encore hivernale. Nous devrons conduire très prudemment, en gardant une distance de sécurité. , , ,

Govern d'Andorra

EAWS
EUROPEAN AVALANCHE WARNING SERVICES

Aquest butlletí ha estat elaborat seguint les normes i recomanacions de l'**European Avalanche Warning Services**, del qual el **Servei meteorològic Nacional** n'és membre

BUTLLETÍ DEL PERILL D'ALLAUS DEL PRINCIPAT D'ANDORRA

Servei meteorològic nacional
Principat d'Andorra

Couche de neige fraiche des derniers jours (De 24 h mesurée à 06:00 h UTC)

	29/03/2026	30/03/2026	31/03/2026	01/04/2026
FEDA (Central)	0 cm	0 cm	0 cm	0 cm
Engolasters - FEDA	0 cm	0 cm	0 cm	7 cm
Bony de les Neres	0 cm	0 cm	3 cm	22 cm
Les Fonts d'Arinsal	0 cm	7 cm	1 cm	22 cm
Perafita	0 cm	0 cm	6 cm	17 cm
Tossa Espiolets	0 cm	4 cm	0 cm	12 cm
Grau Roig - FEDA	0 cm	1 cm	7 cm	34 cm
Fontverd	0 cm	0 cm	0 cm	27 cm
Coll Ordino	0 cm	0 cm	4 cm	18 cm
Ransol - FEDA	0 cm	3 cm	6 cm	20 cm
Setúria	0 cm	2 cm	0 cm	12 cm
Caborreu	0 cm	5 cm	1 cm	21 cm
La Solana	9 cm	6 cm	11 cm	44 cm
Coll Pa	0 cm	3 cm	7 cm	8 cm
Vall del Riu FEDA	0 cm	1 cm	5 cm	48 cm