MINISTERO DELLA DIFESA

meteomont
Servizio Nazionale di previsione neve e valanghe

EAWS EUROPEAN AVALANCHE WARNING SERVICES

CARABINIERI

GRAN SASSO EST - LAGA EST

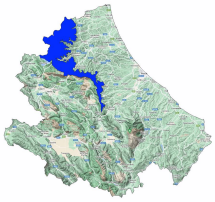

Bollettino Valanghe N. 381/2026 del 02/04/2026 ore 14.00
Validità 48 ore prossima emissione 03/04/2026

A cura del Servizio METEOMONT dell'ARMA dei CARABINIERI
In collaborazione con Servizio Meteorologico dell'Aeronautica militare

SITUAZIONE alle 14:00 del 02/04/2026

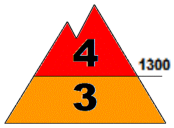

SITUAZIONE TIPO: neve a debole coesione e vento.



SITUAZIONE TIPO: pioggia su neve.

Quota neve (mslm)	Nord	Sud
	800 - 900	900 - 1000

Altezza Neve (cm)	Neve al suolo	Neve Fresca	Quota (mslm)
	048	010	975
	030	002	960

VALANGHE OSSERVATE: Alcune valanghe di grandi dimensioni, Valanghe non accertabili.

PREVISIONI 03/04/2026

GRADO DI PERICOLO: FORTE 4

SITUAZIONE TIPO: neve a debole coesione e vento.

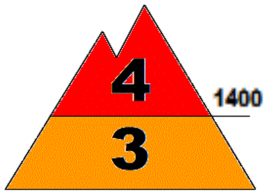

SITUAZIONE TIPO: pioggia su neve.

MANTO NEVOSO: La stabilità del manto nevoso è scarsa su molti punti (aree) per tutte le esposizioni al di sopra di 1400 mslm, possibili valanghe di dimensioni grandi.
La stabilità del manto nevoso è scarsa su alcuni punti (aree) per tutte le esposizioni al di sotto di 1400 mslm, possibili valanghe di dimensioni grandi.

AVVERTENZE

Sono assolutamente da evitare le attività escursionistiche al di fuori dalle piste battute e segnalate.

SCALA EUROPEA DEL GRADO DI PERICOLO VALANGHE

LEGENDA PROBLEMA

Bollettino realizzato su scala sinottica-regionale (standard EAWS). La sua valutazione non può escludere in alcun modo la necessità di una seria e capace valutazione locale del pericolo (singolo pendio) che può essere anche sensibilmente diverso. Le previsioni meteorologiche sono relative all'orario UTC (per l'Italia +1 in inverno e +2 in estate).

MINISTERO DELLA DIFESA

meteomont
Servizio Nazionale di previsione neve e valanghe

EAWS EUROPEAN AVALANCHE WARNING SERVICES

CARABINIERI

GRAN SASSO EST - LAGA EST

PREVISIONE METEO

Quota		03/04/2026 h6:00	03/04/2026 h12:00	03/04/2026 h18:00
1000	Venti	05 Nodi da N-Est	05 Nodi da N-Est	05 Nodi da N-Est
	Temperature	-01 °C	+01 °C	+01 °C
	Temp.percepita	-4 °C	-2 °C	-2 °C
2000	Venti	15 Nodi da N-Est	12 Nodi da Est	12 Nodi da N-Est
	Temperature	-03 °C	-03 °C	-01 °C
	Temp.percepita	-10 °C	-9 °C	-7 °C
3000	Venti	18 Nodi da N-Est	05 Nodi da Nord	11 Nodi da N-Est
	Temperature	-08 °C	-04 °C	-06 °C
	Temp.percepita	-17 °C	-8 °C	-13 °C
Zero termico		1300-1500 m.	1500-1700 m.	1600-1800 m.
Fenomeno			—	—
Stato del cielo				

LEGENDA FENOMENI

— Assenza Fenomeni · Nebbia · Foschia · Pioggia debole · Pioggia moderata · Pioggia forte · Temporali

Nevicata debole · Nevicata moderata · Nevicata forte

STATO DEL CIELO

Sereno · Poco nuvoloso · Nuvoloso · Molto nuvoloso · Coperto

Parametri meteonivometrici registrati presso i campi di rilevamento il 02/04/2026.

Località	Comune	Quota (m.s.l.m.)	Altezza neve (cm)	Neve caduta nelle 24 ore (cm)	Temp. Min (°C)	Temp. Max (°C)	Condizioni del tempo
FAVACCHIOLE	Crognaleto (TE)	1016	75	N.P.	N.P.	N.P.	Pioggia moderata
CASTAGNOLA *	Fano Adriano (TE)	975	48	10	N.P.	N.P.	Pioggia moderata
PIANO SAN PIETRO	Isola del Gran Sasso d'Italia (TE)	950	66	18	N.P.	N.P.	Pioggia mista a neve
PRATI DI TIVO	Pietracamela (TE)	1380	175	70	-1	+1	Nevicata moderata
SAN PAOLO	Acquasanta Terme (AP)	960	30	2	-1	+2	Pioggia moderata
COLLE SAN GIACOMO	Civitella del Tronto (TE)	1075	48	0	0	+2	Nebbia con cielo non visibile

(*) Rilievi fuori campo

L'INFORMAZIONE E' PREVENZIONE - LEGGI L'ATTUALE GRADO DI PERICOLO VALANGHE!

IL CAPO DEL CENTRO NAZIONALE METEOMONT
(Ten. Col. RFI Emanuela Gini)
FIRMA AUTOGRAFA OMESSA AI SENSI
DELL'ART.3 DEL D.LGS N.39/1993

Bollettino realizzato su scala sinottica-regionale (standard EAWS). La sua valutazione non può escludere in alcun modo la necessità di una seria e capace valutazione locale del pericolo (singolo pendio) che può essere anche sensibilmente diverso. Le previsioni meteorologiche sono relative all'orario UTC (per l'Italia +1 in inverno e +2 in estate).