Bulletin d'estimation du risque d'avalanche

(valable en dehors des pistes balisées et ouvertes)

MASSIF : Orlu St-Barthelemy

Rédigé le jeudi 2 avril 2026 à 17h

Estimation des risques pour le : VENDREDI 03 AVRIL

INSTABILITÉS DANS LA NEIGE RÉCENTE AVEC DE NOMBREUSES PLAQUES PARFOIS ÉPAISSES EN ALTITUDE.

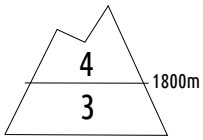

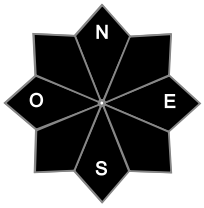

Au-dessus de 1800m indice de risque fort, plus bas indice marqué.

Départs spontanés : Départs poncutels ou linéaires dans la neige récente, dans les couloirs chargés par le vent puis en journée dans les versants prenant le soleil

Déclenchements provoqués : Dans les pentes raides, avalanches de plaques avec des accumulations parfois importantes en altitude

Indices de risque : 5 très fort - 4 fort - 3 marqué - 2 limité - 1 faible -- En noir : les pentes les plus dangereuses

Stabilité du manteau neigeux

Situation avalancheuse typique : neige fraîche couche fragile persistante

Déclenchements provoqués :

Avalanches de plaques de taille moyenne ou grande facilement déclenchables dans la neige récente. Au-dessus de 1800m, de nombreuses structures de plaques sont déjà présentes et de nouvelles accumulations se forment en journée de vendredi sous l'action du vent. Les accumulations les plus épaisses sont situées préférentiellement dans un large versant Sud à Est, mais pas uniquement. Les plaques en place sont majoritairement d'aspect poudreux et difficilement détectables, mais toutefois plus dures et compactes notamment proche des crêtes et sommets.

Sous 1800m, on retrouve les mêmes problématiques qu'en altitude mais moins fréquemment : les cumuls de neige sont a priori moins importants et les instabilités temporaires dans la neige récente moins généralisées.

Observables : Avalanches récentes, quantité de neige fraiche (40 à 60 cm dès 2000m) et accumulations locales, aspect ventée de la surface, fissures devant les skis.

Départs spontanés :

Des départs ponctuels ou linéaires d'avalanches emportant la neige récente sont attendus dans les pentes raides des versants Sud à Est. Avalanches moyennes à grandes, voire rare très grandes au cœur des massifs au-delà de 2000 m en cas de cumuls dépassant les 50/60 cm.

Les départs peuvent être dus à la surcharge de neige par le vent mais aussi par les éclaircies et l'humidification de la neige récente en journée avec les pentes raides des versants Sud à Est souvent plus chargés et propices à ces départs.

Autre : Corniches volumineuses sous les crêtes.

Qualité de la neige

Enneigement :

L'enneigement est très bon pour la saison. En altitude, les cumuls sont conséquents, mais les crêtes et sommets exposés au vent d'ouest à nord-ouest sont parfois plus dégarnis. Même si la neige est visible dès 1300 m, il est envisageable de chausser les skis plutôt à partir de 1400/1500 m sur une sous-couche.

Qualité de la neige :

Vendredi matin, on trouvera des cumuls importants de neige récente : 10/20 cm dès 1500/1600 m, 20/40 cm au-delà de 2000 m, et localement 50/70 cm sur Orlu. En altitude et sur le haut du massif, l'enneigement et la qualité de la neige sont assez hétérogènes sous l'action du vent soufflant depuis plusieurs jours, avec des zones où la neige récente est encore localement légère (combes abritées) et des zones proches des crêtes Ouest à Nord-Ouest pelées ou en neige dure, voire glacée.

Aperçu météo pour le vendredi 03 avril

Fin des chutes de neige le matin puis amélioration progressive l'après-midi. Vent également en baisse au fil de la journée.

	nuit	matin	après-midi	soir
Pluie-Neige	1 400 m	1 500 m		
Iso 0 °C	1 700 m	1 900 m	2 200 m	2 300 m
Vent 2000 m	↘ 55 km/h	↘ 40 km/h	↘ 35 km/h	↘ 25 km/h
Vent 3000 m	↓ 65 km/h	↓ 60 km/h	↓ 50 km/h	↓ 50 km/h

Épaisseur de neige hors-piste

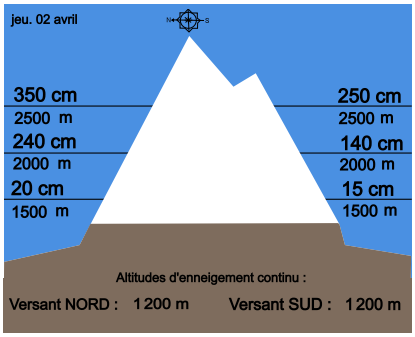

Précipitations à 1800 m

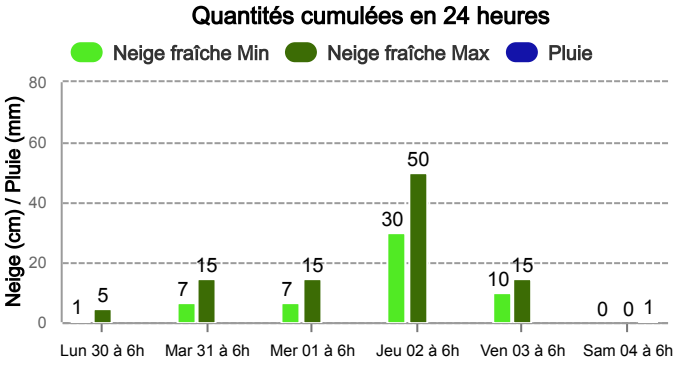

Tendance du samedi 04 avril

Indice de risque marqué

Stabilisation progressive des chutes de neige récente mais des départs spontanés à attendre avec l'humidification.

Pour consulter la vigilance en cours, veuillez vous rendre sur le site https://vigilance.meteofrance.fr/fr

Météo-France - 73 avenue de Paris, 94165 Saint-Mandé cedex - Contact : contact@meteo.fr

Rédigé par Météo-France avec la contribution des observateurs du réseau nivo-météorologiques. Partenariat : ANMSM (Maires de Stations de Montagne), DSF (Domaines Skiables de France), ADSP (Directeurs de Pistes et de la Sécurité des Stations de Sports d'Hiver) et autres acteurs de la montagne.

Bulletin neige & avalanches par téléphone au
0 892 68 10 20 Service 0,35 € / min + prix appel

RÉPUBLIQUE FRANÇAISE
Liberté Égalité Fraternité

METEO FRANCE
À VOS CÔTÉS, DANS UN CLIMAT QUI CHANGE

Bulletin d'estimation du risque d'avalanche

(valable en dehors des pistes balisées et ouvertes)

MASSIF : Orlu St-Barthelemy

Rédigé le jeudi 2 avril 2026 à 17h

Conditions nivo-météo des 7 derniers jours

	ven. 27/03				sam. 28/03				dim. 29/03				lun. 30/03				mar. 31/03				mer. 01/04				jeu. 02/04			
	03h	09h	15h	21h	03h	09h	15h	21h	03h	09h	15h	21h	03h	09h	15h	21h	03h	09h	15h	21h	03h	09h	15h	21h	03h	09h	15h	21h
Météo																												
Vent (km/h)	80	80	65	45	40	45	65	85	100	90	65	60	60	65	70	75	80	80	80	75	85	85	80	85	80	80	75	75
à 3000m	↓	↓	↓	↓	↓	↓	↓	↓	↓	↓	↓	↓	↓	↓	↘	↘	↓	↻	↓	↓	↓	↓	↓	↓	↘	↘	↓	↘
Vent (km/h)	50	50	40	20	20	20	40	55	75	65	45	35	45	40	55	50	65	60	60	60	60	60	70	70	65	60	65	65
à 2000m	↓	↓	↓	↓	↓	↓	↓	↓	↘	↘	↘	↘	↘	↘	↘	↘	↘	↘	↘	↘	↘	↘	↘	↘	↘	↘	↘	↘

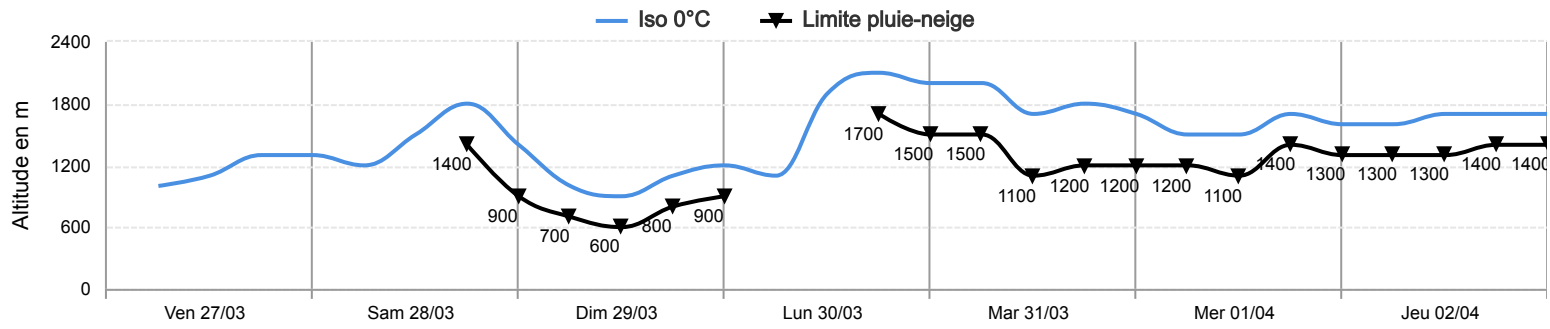

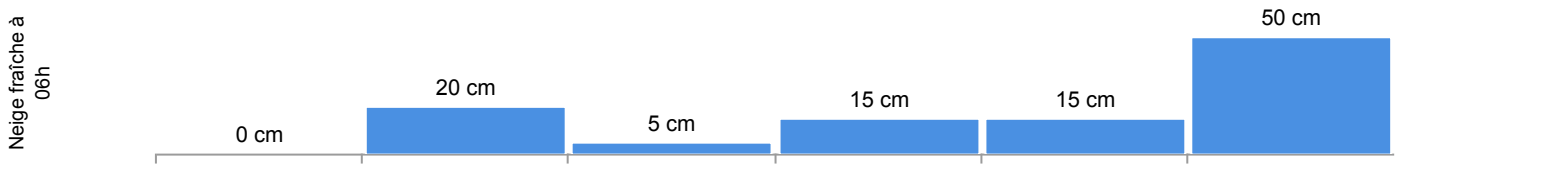

Risque d'avalanche	ven. 27/03	sam. 28/03	dim. 29/03	lun. 30/03	mar. 31/03	mer. 01/04	jeu. 02/04
	2	2	3	3	3	4	4

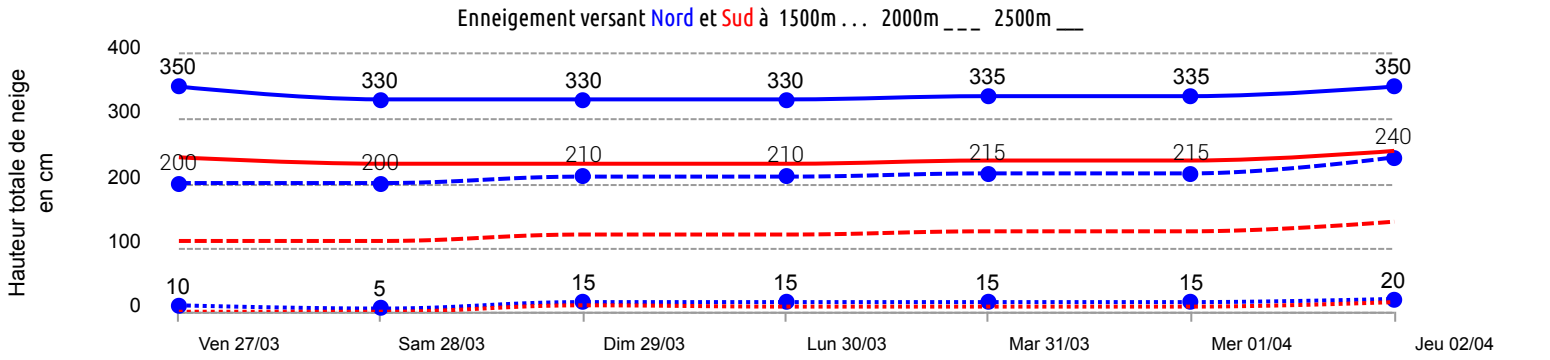

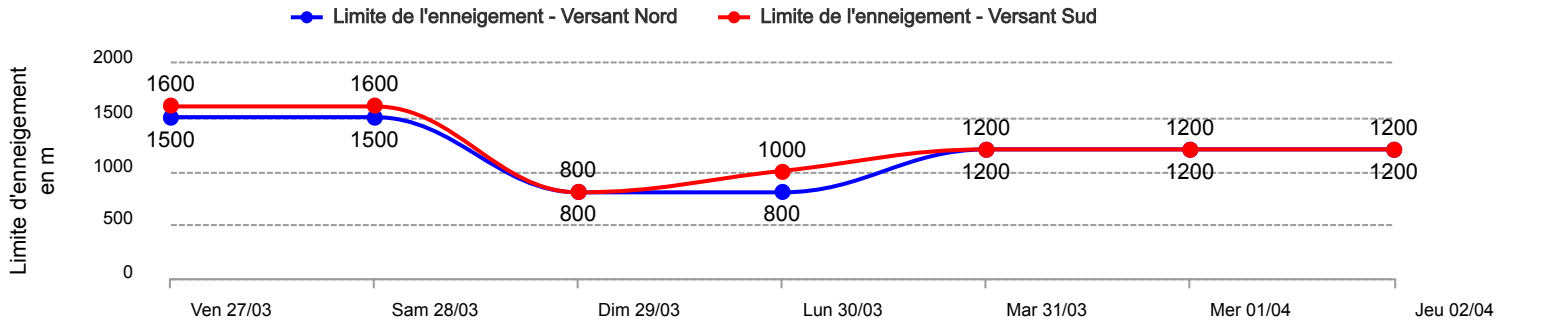

Pour consulter la vigilance en cours, veuillez vous rendre sur le site https://vigilance.meteofrance.fr/fr

Météo-France - 73 avenue de Paris, 94165 Saint-Mandé cedex - Contact : contact@meteo.fr

Rédigé par Météo-France avec la contribution des observateurs du réseau nivo-météorologiques. Partenariat : ANMSM (Maires de Stations de Montagne), DSF (Domaines Skiables de France), ADSP (Directeurs de Pistes et de la Sécurité des Stations de Sports d'Hiver) et autres acteurs de la montagne.

Bulletin neige & avalanches par téléphone au

0 892 68 10 20 Service 0,35 € / min + prix appel