GOBIERNO DE ESPAÑA
VICEPRESIDENCIA TERCERA DEL GOBIERNO
MINISTERIO PARA LA TRANSICIÓN ECOLÓGICA Y EL RETO DEMOGRÁFICO

Boletín de información nivológica y de peligro de aludes

Pirineo Navarro y Aragonés

aemet Agencia Estatal de Meteorología

viernes, 3 de abril de 2026

Pronóstico hasta las 24 horas del sábado, día 4 de abril

(Válido fuera de pistas de esquí balizadas y abiertas)

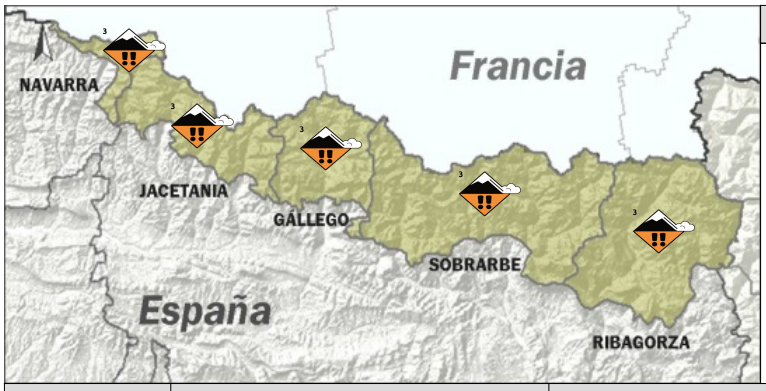

Problemas de aludes

Placas de viento

Nieve húmeda

Macizo	Peligro	Problemas de aludes, cota, orientación, tamaño	Innivación observada (m)
Navarra	3 / 3 2000 / 2 Notable	Placas de viento: 2000, N O E S, 3 Nieve húmeda: N O E S, 2	2026-04-03 N S 1400
Jacetania	3 / 3 2000 / 2 Notable	Placas de viento: 2000, N O E S, 2 Nieve húmeda: N O E S, 2	2026-04-03 N S 1600
Gállego	3 / 3 2000 / 2 Notable	Placas de viento: 2000, N O E S, 2 Nieve húmeda: N O E S, 2	2026-04-03 N S 1600

AEMET. Se autoriza la reproducción de su contenido citando la fuente.

Boletín de información nivológica y de peligro de aludes

Pirineo Navarro y Aragonés

Sobrarbe	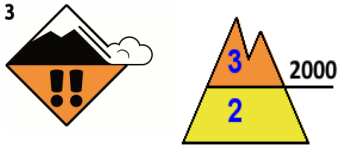 **Notable**	**Placas de viento** 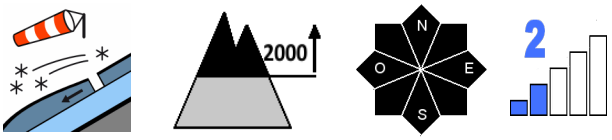 **Nieve húmeda** 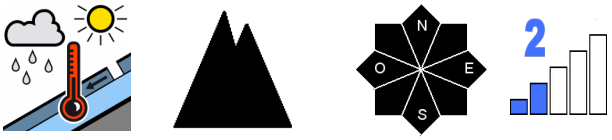	2026-04-03 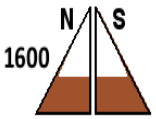
Ribagorza	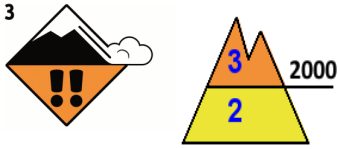 **Notable**	**Placas de viento** 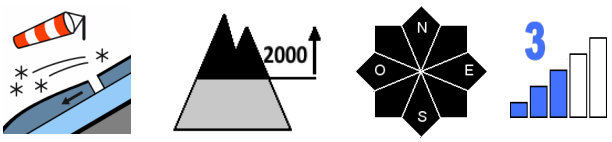 **Nieve húmeda** 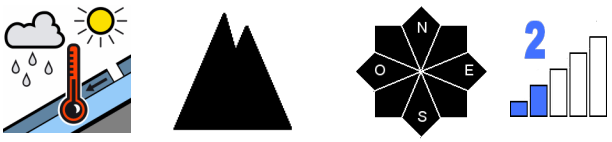	2026-04-03 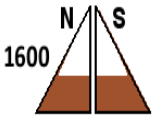

Estado del manto y observaciones recientes

El episodio de nevadas ha cesado esta madrugada, aunque durante la jornada de hoy aún seguirán soplando vientos fuertes de componente norte que continuarán movilizando la nieve y formando nuevas placas. Se han podido acumular en torno a 20-45 cm de nieve nueva desde el martes en puntos de Navarra, Jacetania y la Ribagorza, de los cuales entre 10-15 cm han caído en las 24 horas anteriores a las 08 UTC de hoy, localmente más ventisqueros y otras zonas de acumulación. En el resto de macizos han sido sustancialmente menores, con unos 10-15 cm en total, siendo las precipitaciones registradas ayer generalmente escasas y débiles.

Con los últimos aportes, encontramos nieve a partir de unos 1400-1600 metros, pero con espesores de solo unos pocos centímetros. En cambio, a unos 2000-2200 metros se alcanzan los 100-200 cm, valores por encima de lo habitual para estas fechas, que se pueden superar ampliamente en ventisqueros y otras zonas propensas a la acumulación.

Durante las nevadas de los últimos días han soplado vientos fuertes o muy fuertes del norte, que han formado numerosas placas en muchas orientaciones, aunque con mayor frecuencia en vertientes sur y suroeste, generalmente por encima de unos 1800-2000 metros. Antes de este episodio, el manto se encontraba duro y encostrado, con algunas capas débiles persistentes en la base, de las cuales alguna se mostraba reactiva ante sobrecargas fuertes. Tras el episodio la distribución de la nieve reciente es muy irregular, con zonas discontinuas y erosionadas a barlovento y con grandes acumulaciones en zonas protegidas del viento, especialmente en canales, cubetas y cordales.

AEMET. Se autoriza la reproducción de su contenido citando la fuente.

Evolución del manto y peligro de aludes para el sábado, día 4

Mañana se producirá un ascenso brusco de las temperaturas, con alta insolación y cese de los vientos intensos. Todo ello propiciará una acusada humidificación del manto y la estabilización progresiva de las placas de viento, especialmente en solanas.

Con estas condiciones se esperan numerosos aludes naturales de nieve húmeda en toda la montaña, más probables en solanas y durante la segunda mitad del día, que serán de tamaño pequeño (riesgo de caída) o mediano (capaz de enterrar a una persona), sin descartar alguno puntualmente grande (capaz de enterrar un vehículo) en zonas de mayor acumulación. Asimismo podrán darse también deslizamientos basales en terrenos herbosos o de roca lisa generalmente de tamaño mediano.

Las placas de viento se mantendrán frágiles en umbrías y podrán ceder ante una sobrecarga débil (un esquiador). En solanas de cotas altas, donde serán más duras y gruesas, también podrán desencadenarse ante una sobrecarga débil o fuerte (grupo esquiadores), provocando aludes de tamaño mediano o localmente grande, especialmente en el sector navarro y de la Ribagorza, o incluso de mayores dimensiones si afectaran a capas débiles persistentes en profundidad.

Predicción meteorológica para el sábado, día 4

Nuboso al inicio de la madrugada, tendiendo pronto a poco nuboso o despejado con velos de nubes altas. No se esperan precipitaciones. Temperaturas en ascenso, notable en las máximas. Heladas débiles en cotas altas, localmente moderadas. Moderado o fuerte de componente norte de madrugada, disminuyendo a flojo y girando a componentes sur y oeste durante el día.

Datos en la atmósfera libre:

Altitud de la isoterma de 0 ºC: 3200 m
Altitud de la isoterma de -10 ºC: 4700 m

Viento a 1500 m: SW 10 km/h
Viento a 3000 m: NE 20 km/h

Evolución para el domingo día 5

Nivel de peligro en ligero descenso. Aumento del problema de nieve húmeda y descenso del problema de placas de viento.

(Información elaborada a partir de los datos recibidos de los refugios de Linza, Lizara, Panticosa, Bachimaña, Góriz, Pineta, Estós, Angel Orús y La Renclusa, de las estaciones de esquí de Candanchú, Astún, Formigal y Panticosa (lagos), de la estación de esquí de fondo de Llanos del Hospital y de Ordesa Pradera)

Escala europea de peligro de aludes

Débil | Limitado | Notable | Fuerte | Muy Fuerte

Problemas de aludes

Nieve reciente | Placas de viento | Capas débiles persistentes | Nieve húmeda | Deslizamientos basales | Sin problema evidente

AEMET. Se autoriza la reproducción de su contenido citando la fuente.

Nota1: Se recuerda que, siempre que haya nieve, la ausencia total de peligro no existe. Hay que tener presente que en circunstancias desfavorables, con aludes de tamaño 1 (alud pequeño o colada) y tamaño 2 (alud mediano), se pueden sufrir severos daños personales.

Nota2: Los BPA se elaboran en base a información meteorológica así como al estado del manto nivoso a través de sondeos puntuales. Se advierte a los usuarios de la variabilidad de esta información al extrapolarla a zonas extensas de montaña. Por ello, AEMET no se hace responsable de su uso para la toma de decisiones que conciernen a la seguridad personal, ni de los riesgos físicos o materiales de ellas derivadas.

AEMET. Se autoriza la reproducción de su contenido citando la fuente.