Samstag 04.04.2026

Aktualisiert am 03.04.2026 um 17:16

Vormittag

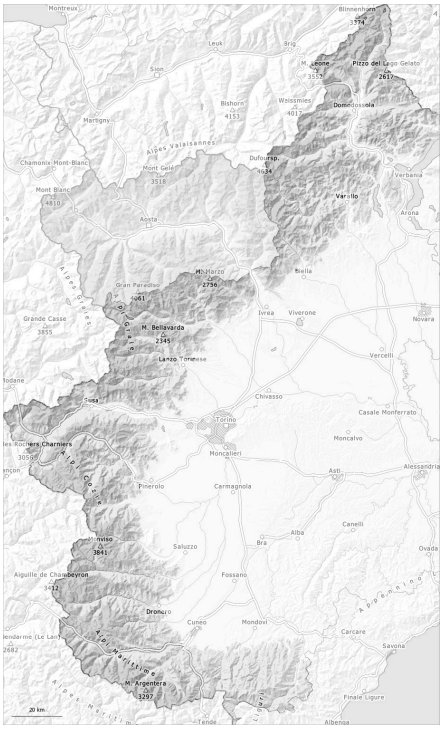

Nachmittag

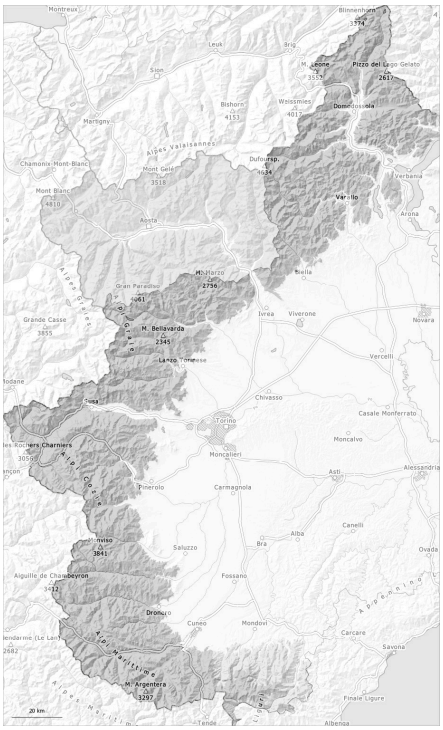

1	2	3	4	5
gering	mäßig	erheblich	groß	sehr groß

Gefahrenstufe 2 - Mäßig

AM:

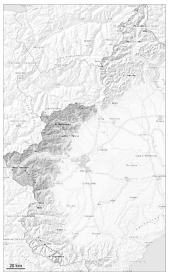

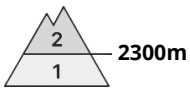

Tendenz: Lawinengefahr bleibt gleich
am Sonntag, den 05.04.2026

Triebschnee

PM:

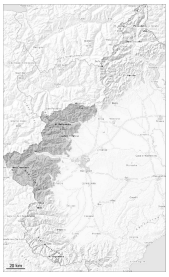

Tendenz: Lawinengefahr bleibt gleich
am Sonntag, den 05.04.2026

Triebschnee

Nassschnee

Triebschnee und schwacher Altschnee sind die Hauptgefahr.

Seit Montag blies der Wind stark. Die gut sichtbaren Triebschneeansammlungen der letzten Tage können in mittleren und hohen Lagen teilweise ausgelöst werden, besonders in ihren Randbereichen.

Ungünstig sind Stellen, wo im Altschnee persistente Schwachschichten vorhanden sind, die teilweise aus eingeschneitem Oberflächenreif bestehen. Die Lawinen können besonders an steilen West-, Nord- und Osthängen im schwachen Altschnee ausgelöst werden und mittlere Größe erreichen. Dies vor allem mit großer Belastung.

Die Gefahr von feuchten und nassen Lawinen steigt ab dem Mittag an.

Schneedecke

Gefahrenmuster gm.6: lockerer schnee und wind

Am Montag fiel gebietsweise etwas Schnee. Mit starkem Nordwestwind entstanden seit Montag vor allem kammfern harte Triebschneeansammlungen.
Im mittleren Teil der Schneedecke sind in mittleren und hohen Lagen einzelne Schwachschichten vorhanden.

Die nächtliche Abstrahlung ist gut. Die Schneeoberfläche ist tragfähig gefroren und weicht im Tagesverlauf auf.

In höheren Lagen nimmt die Schneedecke ab und wird ungleichmäßig; in mittleren Höhenlagen, die weniger vom Wind betroffen sind, ist sie besser.

Tendenz

Mit der tageszeitlichen Erwärmung und der Sonneneinstrahlung steigt die Auslösebereitschaft von trockenen und nassen Lawinen an sehr steilen Hängen in der Höhe etwas an.

Gefahrenstufe 2 - Mäßig

AM:

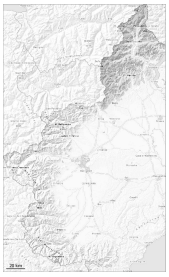

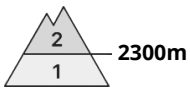

Tendenz: Lawinengefahr bleibt gleich
am Sonntag, den 05.04.2026

Triebschnee

PM:

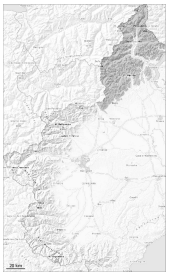

Tendenz: Lawinengefahr bleibt gleich
am Sonntag, den 05.04.2026

Nassschnee

Triebschnee

Triebschnee ist die Hauptgefahr.

Die gut sichtbaren Triebschneeansammlungen der letzten Tage können vor allem an den Expositionen West über Nord bis Ost in hohen Lagen und im Hochgebirge vor allem mit großer Zusatzbelastung ausgelöst werden. Die Lawinen können an Triebschneehängen in den verschiedenen Triebschneeschichten ausgelöst werden und mittlere Größe erreichen. Ungünstig sind v.a. Stellen, wo Schwachstellen im Altschnee vorhanden sind. Vorsicht vor allem in Rinnen, Mulden und hinter Geländekanten in mittleren und hohen Lagen. Mit der tageszeitlichen Erwärmung und der Sonneneinstrahlung nimmt die Anzahl der Gefahrenstellen ab dem Mittag zu.

Vor allem sehr steile Sonnenhänge, mittlere und hohe Lagen: Auf der harten Schneeoberfläche besteht im Steilgelände Absturzgefahr.

Die Gefahr von feuchten und nassen Lawinen steigt ab dem Mittag an.

Schneedecke

Gefahrenmuster gm.6: lockerer schnee und wind

Mit starkem Nordostwind entstanden seit Montag an allen Expositionen gut sichtbare Triebschneeansammlungen.

Vor allem tiefe und mittlere Lagen Sonnenhänge: Die Schneeoberfläche ist tragfähig gefroren.

In Kammlagen im Hochgebirge liegen je nach Windeinfluss sehr unterschiedliche Schneehöhen. In höheren Lagen nimmt die Schneedecke ab und wird ungleichmäßig; in mittleren Höhenlagen, die weniger vom Wind betroffen sind, ist sie besser.
Die Schneedecke an der Oberfläche verändert sich je nach Lage und Hangneigung rasch: Es wechseln sich Krusten unterschiedlicher Art und Dicke ab.

Auf der harten Kruste besteht im Steilgelände Absturzgefahr, besonders in Kamm- und Passlagen.
Sonne und Wärme führen zu einer zunehmenden Verfestigung der Schneedecke.

Tendenz

Mit der tageszeitlichen Erwärmung und der Sonneneinstrahlung steigt die Auslösebereitschaft von trockenen und nassen Lawinen an sehr steilen Sonnenhängen etwas an.

Gefahrenstufe 2 - Mäßig

AM:

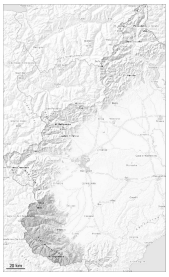

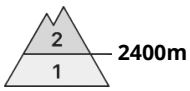

Tendenz: Lawinengefahr bleibt gleich
am Sonntag, den 05.04.2026

Triebschnee

PM:

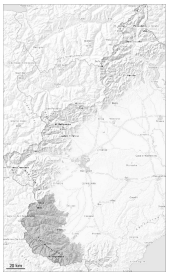

Tendenz: Lawinengefahr bleibt gleich
am Sonntag, den 05.04.2026

Triebschnee

Nassschnee

Die Triebschneeansammlungen sind gut erkennbar und vor allem mit großer Belastung auslösbar.

Die Schneedecke ist in tiefen und mittleren Lagen gut verfestigt.

Mittlere und hohe Lagen: Mit Neuschnee und mäßigem bis starkem Wind aus nordöstlichen Richtungen entstanden in den letzten Tagen besonders in Kamm- und Passlagen sowie in der Höhe gut sichtbare Triebschneeansammlungen. Diese können vor allem mit großer Belastung ausgelöst werden und mittlere Größe erreichen.

Auf der eisigen Kruste besteht im Steilgelände Absturzgefahr.

Die Gefahr von feuchten und nassen Lawinen steigt ab dem Mittag an.

Schneedecke

Gefahrenmuster gm.6: lockerer schnee und wind

Seit Montag blies der Wind verbreitet stark. In Gipfellagen liegen je nach Windeinfluss sehr unterschiedliche Schneehöhen.

Vor allem Sonnenhänge tiefe und mittlere Lagen: Die Schneeoberfläche ist tragfähig gefroren und weicht im Tagesverlauf auf.

Besonders in schattigen, windgeschützten Lagen hohe Lagen und Hochgebirge: Der obere Bereich der Schneedecke ist trocken, mit einer nicht tragfähigen Kruste an der Oberfläche. Im oberen Teil der Schneedecke sind vor allem an extrem steilen Schattenhängen sehr vereinzelt Schwachschichten vorhanden.

Tendenz

Mit der tageszeitlichen Erwärmung und der Sonneneinstrahlung steigt die Auslösebereitschaft von trockenen und nassen Lawinen an sehr steilen Hängen in der Höhe etwas an.

Gefahrenstufe 2 - Mäßig

AM:

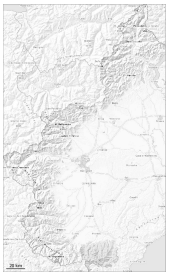

Tendenz: Lawinengefahr bleibt gleich
am Sonntag, den 05.04.2026

PM:

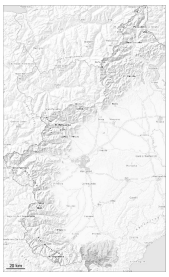

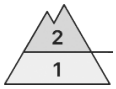

2200m

Tendenz: Lawinengefahr bleibt gleich
am Sonntag, den 05.04.2026

Nassschnee

2200m

Die Schneedecke ist verbreitet stabil.

Die Schneedecke ist in tiefen und mittleren Lagen gut verfestigt.

Mittlere und hohe Lagen: Mit mäßigem bis starkem Wind aus nordöstlichen Richtungen entstanden in den letzten Tagen in Rinnen, Mulden und hinter Geländekanten kleine Triebschneeansammlungen. Diese können teilweise vereinzelt mit meist großer Belastung ausgelöst werden.

Auf der eisigen Kruste besteht im Steilgelände Absturzgefahr.

Die Gefahr von feuchten und nassen Lawinen steigt ab dem Mittag an.

Schneedecke

Gefahrenmuster gm.6: lockerer schnee und wind

Seit Montag blies der Wind verbreitet stark. Die Schneedecke an der Oberfläche verändert sich je nach Lage und Hangneigung rasch: Es wechseln sich Krusten unterschiedlicher Art und Dicke ab.

Vor allem Sonnenhänge tiefe und mittlere Lagen: Die Schneeoberfläche ist tragfähig gefroren und weicht im Tagesverlauf auf.

In schattigen, windgeschützten Lagen hohe Lagen und Hochgebirge: Der obere Bereich der Schneedecke ist trocken, mit einer nicht tragfähigen Kruste an der Oberfläche.

Auf der harten Kruste besteht im Steilgelände Absturzgefahr, besonders in Kamm- und Passlagen. Sonne und Wärme führen zu einer zunehmenden Verfestigung der Schneedecke.

Tendenz

Mit der tageszeitlichen Erwärmung und der Sonneneinstrahlung steigt die Auslösebereitschaft von trockenen und nassen Lawinen an sehr steilen Hängen in der Höhe etwas an.