Sabato 04.04.2026

Aggiornato03.04.2026 alle ore 17:16

Mattina

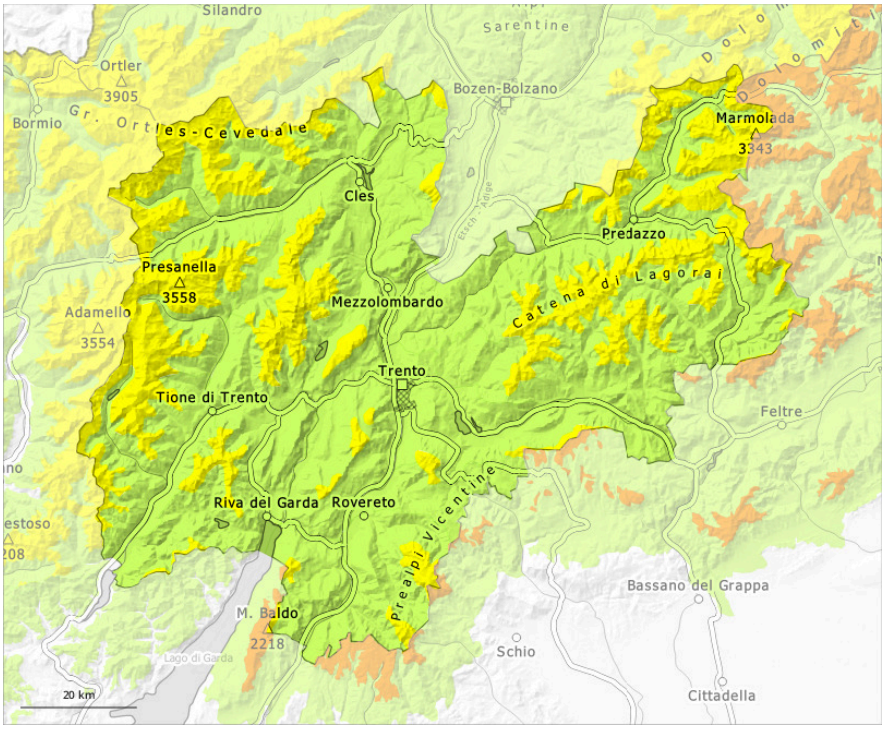

pomeriggio

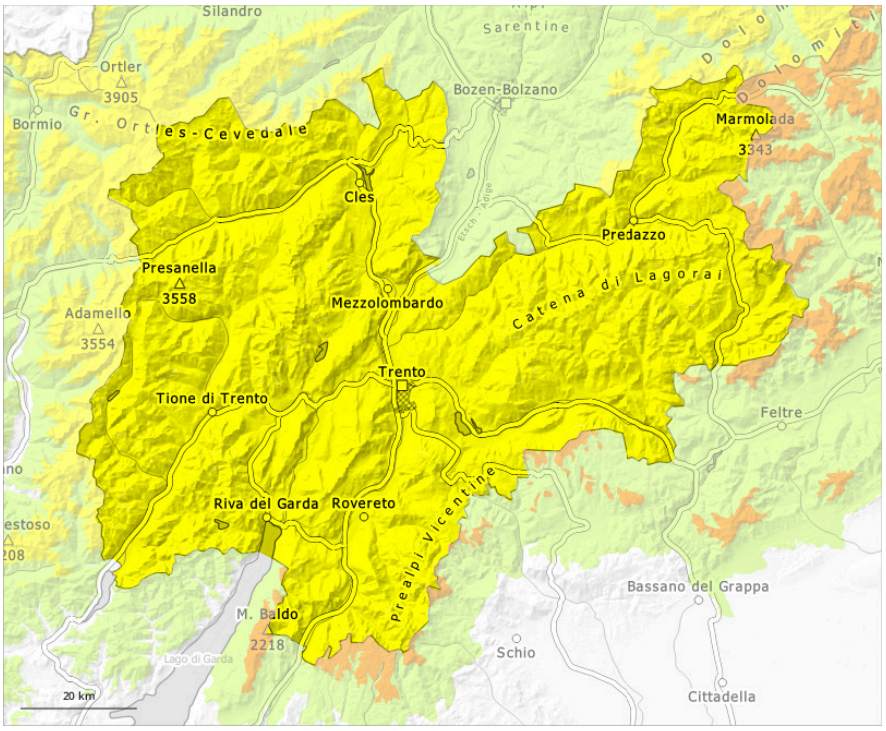

1	2	3	4	5
debole	moderato	marcato	forte	molto forte

Grado di pericolo 2 - Moderato

AM:

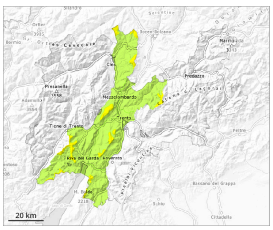

Limite del bosco

Tendenza: pericolo valanghe stabile
per Domenica il 05.04.2026

Lastrone da vento

Limite del bosco

PM:

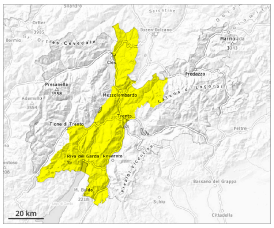

Tendenza: pericolo valanghe stabile
per Domenica il 05.04.2026

Lastrone da vento

Limite del bosco

Neve bagnata

2500m

La neve ventata è la principale fonte di pericolo.

Gli ultimi accumuli di neve ventata rappresentano la principale fonte di pericolo. Le valanghe possono coinvolgere gli strati più profondi del manto nevoso e raggiungere dimensioni medie. Con il rialzo termico e l'irradiazione solare diurni, aumento del pericolo di scaricamenti di neve umida e bagnata.

Manto nevoso

Situazione tipo st.6: neve a debole coesione e vento | st.1: strato debole persistente basale

Con vento da forte a tempestoso proveniente dai quadranti settentrionali negli ultimi giorni specialmente nelle conche, nei canaloni e dietro ai cambi di pendenza si sono formati accumuli di neve ventata in parte di grandi dimensioni. I nuovi accumuli di neve ventata poggiano su una sfavorevole superficie del manto di neve vecchia a tutte le esposizioni e per lo più al di sopra del limite del bosco.
Il sole e il calore causeranno nel corso della giornata al di sotto dei 2500 m circa un inumidimento del manto nevoso.

Tendenza

Sabato: Il pericolo di valanghe rimarrà invariato.

Grado di pericolo 2 - Moderato

AM:

Limite del bosco

Tendenza: pericolo valanghe stabile
per Domenica il 05.04.2026

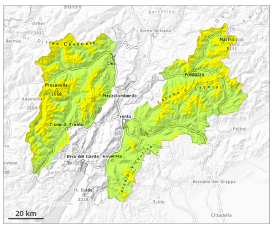

Lastrone da vento

Limite del bosco

Strati deboli persistenti

Limite del bosco

PM:

Tendenza: pericolo valanghe stabile
per Domenica il 05.04.2026

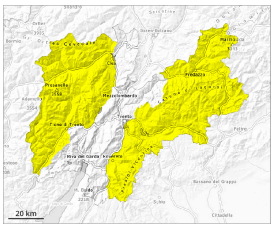

Lastrone da vento

Limite del bosco

Strati deboli persistenti

Limite del bosco

Neve bagnata

2500m

Attenzione alla neve ventata e alla neve vecchia con strati deboli persistenti.

Le valanghe possono distaccarsi soprattutto in seguito a un forte sovraccarico. Ciò soprattutto al di sopra del limite del bosco, come pure nelle zone di passaggio da poca a molta neve come p.es. all'ingresso di conche e canaloni.
Sui pendii ombreggiati molto ripidi, all'interno del manto di neve vecchia si trovano insidiosi strati fragili. Questi punti pericolosi si trovano soprattutto alle esposizioni da est a nord sino a ovest. Principalmente nelle zone in prossimità delle creste, nelle conche e nei canaloni sono possibili valanghe di medie e, a livello isolato, di grandi dimensioni.
Con il rialzo termico e l'irradiazione solare diurni, aumento del pericolo di scaricamenti di neve umida e bagnata.

Manto nevoso

Situazione tipo st.6: neve a debole coesione e vento st.1: strato debole persistente basale

Il vento a tratti tempestoso ha causato il trasporto della neve. Con vento da forte a tempestoso proveniente dai quadranti settentrionali negli ultimi giorni specialmente nelle conche, nei canaloni e dietro ai cambi di pendenza si sono formati accumuli di neve ventata in parte di grandi dimensioni. I nuovi accumuli di neve ventata poggiano su una sfavorevole superficie del manto di neve vecchia soprattutto sui pendii esposti da est a nord sino a ovest e per lo più al di sopra del limite del bosco.
Nel corso della giornata l'irradiazione solare causerà al di sotto dei 2500 m circa un inumidimento del manto nevoso.

Tendenza

Sabato: Il pericolo di valanghe rimarrà invariato.