ICGC Institut Cartogràfic i Geològic de Catalunya

Servei Meteorològic de Catalunya meteo.cat

Boletín de peligro de aludes para el Pirineo de Catalunya
Del 03/04/2026 al 04/04/2026

(Válido fuera pistas de esquí y zonas no controladas)

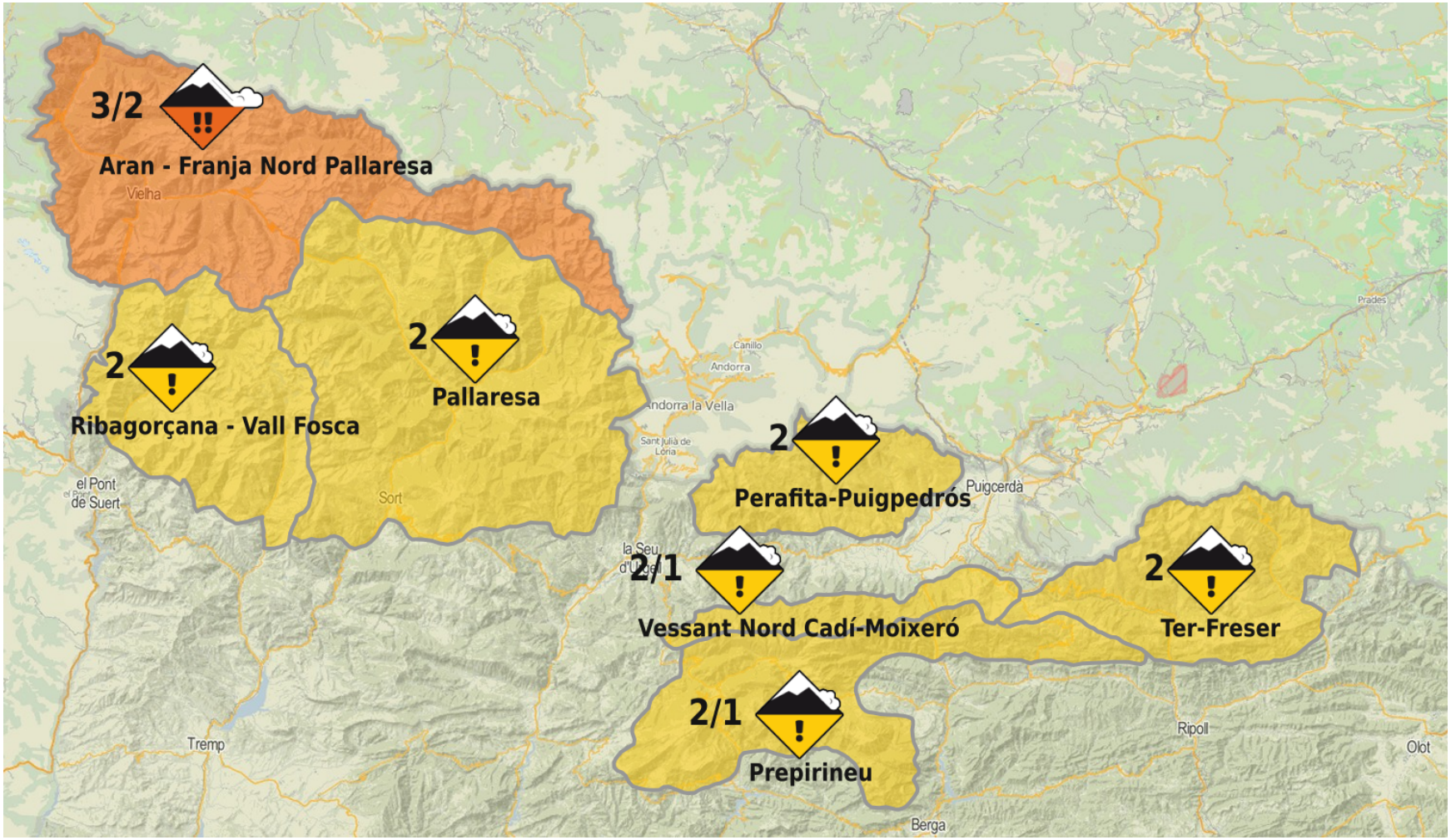

5 MUY FUERTE	4 FUERTE	3 NOTABLE	2 LIMITADO	1 DÉBIL

ICGC Institut Cartogràfic i Geològic de Catalunya

meteo.cat Servei Meteorològic de Catalunya

Boletín de peligro de aludes Aran - Franja Nord Pallaresa Del 03/04/2026 al 04/04/2026

(Válido fuera pistas de esquí y zonas no controladas)

NOTABLE (3) por encima de 2.000 m.
LIMITADO (2) por debajo.

Situación primaria

Nieve venteada

Distribución

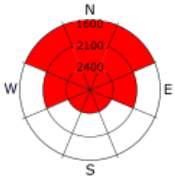

Tamaño

Origen

Tendencia

Situación secundaria

Nieve húmeda

Distribución

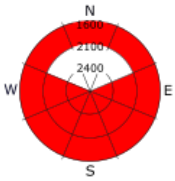

Tamaño

Origen

Tendencia

Estado del manto nivoso

El viernes ha habido numerosos aludes, tanto naturales como provocados, de tamaños 2 y 3 (suficiente para enterrar a un grupo de personas) en forma de placas blandas de nieve reciente o de placas de viento. Se prevé que el sábado las placas tiendan a ser progresivamente más difíciles de desencadenar en terreno soleado, donde será necesaria una sobrecarga fuerte; en umbrías, donde la nieve del último episodio reposa a menudo sobre niveles débiles persistentes, las placas serán todavía sensibles al desencadenamiento por sobrecarga débil. Además se espera que el manto humedece superficialmente y, a lo largo de la jornada, haya aludes de nieve húmeda de tamaños 1 y 2 (suficiente para enterrar a una persona). Serán más frecuentes en las cotas más bajas y en el terreno más soleado, cerca de puntos oscuros como rocas y árboles. También se espera la caída natural de deslizamientos basales de tamaño 2 en terreno propicio.

Distribución del manto nivoso

El último episodio de nevadas ha encalado el suelo por encima de unos 1.400 m. Los espesores a unos 2.200 m son ligeramente superiores a los normales en la Franja Norte de la Pallaresa y en la mitad sur de Arán, donde rondan los 200-240 cm. En la mitad norte de Arán son los normales por estas fechas con unos 150-170 cm de espesor total.

Tendencia para las próximas 48-72h

En buena parte del terreno encontraremos cierto rehielo matinal, que irá cediendo y podrá haber aludes de nieve húmeda. Las placas sensibles al desencadenamiento accidental irán quedando restringidas en el terreno más umbrío. Peligro EN DESCENSO.

El próximo boletín será emitido el día 2026-04-04

5 MUY FUERTE	4 FUERTE	3 NOTABLE	2 LIMITADO	1 DÉBIL

EAWS EUROPEAN AVALANCHE WARNING SERVICES

ICGC Institut Cartogràfic i Geològic de Catalunya

meteo.cat Servei Meteorològic de Catalunya

Boletín de peligro de aludes Ribagorçana - Vall Fosca Del 03/04/2026 al 04/04/2026

(Válido fuera pistas de esquí y zonas no controladas)

LIMITADO (2)

Situación primaria

Nieve húmeda

Distribución

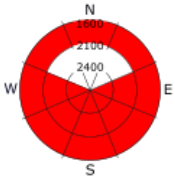

Tamaño

Origen

Tendencia

Situación secundaria

Nieve venteada

Distribución

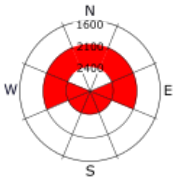

Tamaño

Origen

Tendencia

Estado del manto nivoso

Durante la jornada irá tomando protagonismo el humedecimiento de la nieve. A primera hora el manto estará encostrado en muchos lugares, pero irá transformando por la insolación y las temperaturas elevadas, pudiendo caer purgas de nieve húmeda en terreno inclinado, especialmente alrededor de puntos oscuros y afectando principalmente a la nieve de los últimos episodios.

Además, actualmente existen placas de viento en lugares resguardados de todas las orientaciones. Se trata de acumulaciones locales, más abundantes y de mayor tamaño en la mitad norte del sector, y que pueden desprenderse al paso de una persona. El sábado serán más fáciles de desencadenar aquellas que se encuentren en terreno umbrío o cerca de las cimas y crestas más elevadas en solanas. En caso de caer, los aludes podrán alcanzar tamaño 2 o, de forma local, tamaño 3 (suficiente para enterrar a un grupo de personas) en sotaventos muy claros del norte del sector.

Distribución del manto nivoso

Aunque hay nieve desde unos 1.500 m en umbrías por el último episodio de nevadas, la nieve presenta cierta continuidad a partir de 1.700 m en terreno umbrío y de 1.900 m solanas. Los grosores alcanzan los 100-120 cm a unos 2.200 m, con frecuentes deflaciones y acumulaciones por encima del nivel del bosque. Estos valores se acercan a los normales para la época.

Tendencia para las próximas 48-72h

Continuará avanzando el humedecimiento de la nieve, aunque no se espera una actividad de aludes de nieve húmeda muy frecuente. Peligro EN DESCENSO.

El próximo boletín será emitido el día 2026-04-04

5 MUY FUERTE	4 FUERTE	3 NOTABLE	2 LIMITADO	1 DÉBIL

EAWS EUROPEAN AVALANCHE WARNING SERVICES

ICGC Institut Cartogràfic i Geològic de Catalunya

Servei Meteorològic de Catalunya meteo.cat

Boletín de peligro de aludes Pallaresa
Del 03/04/2026 al 04/04/2026

(Válido fuera pistas de esquí y zonas no controladas)

LIMITADO (2)

Situación primaria

Nieve húmeda

Distribución

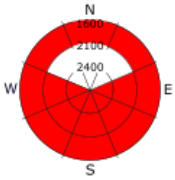

Tamaño

Origen

Tendencia

Situación secundaria

Nieve venteada

Distribución

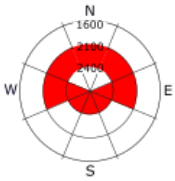

Tamaño

Origen

Tendencia

Estado del manto nivoso

Durante la jornada irá tomando protagonismo el humedecimiento de la nieve. A primera hora el manto estará encostrado en muchos lugares, pero irá transformando por la insolación y las temperaturas elevadas, pudiendo caer purgas de nieve húmeda en terreno inclinado, especialmente alrededor de puntos oscuros y afectando principalmente a la nieve de los últimos episodios. Además, actualmente existen placas de viento en lugares resguardados de todas las orientaciones. Se trata de acumulaciones locales, más abundantes y de mayor tamaño en la mitad norte del sector, y que pueden desprenderse al paso de una persona. El sábado serán más fáciles de desencadenar aquellas que se encuentren en terreno umbrío o cerca de las cimas y crestas más elevadas en solanas. En caso de caer, los aludes podrán alcanzar tamaño 2 o, de forma local, tamaño 3 (suficiente para enterrar a un grupo de personas) en sotaventos muy claros del norte del sector.

Distribución del manto nivoso

Aunque hay nieve desde unos 1.400 m en umbrías por último episodio de nevadas, la nieve presenta cierta continuidad por encima de 1.700 m en terreno umbrío y de 1.900 m solanas. Los espesores alcanzan los 110-150 cm en cotas medias, con frecuentes acumulaciones y deflaciones por encima del nivel del bosque.

Tendencia para las próximas 48-72h

Continuará avanzando el humedecimiento de la nieve, aunque no se espera una actividad de aludes de nieve húmeda muy frecuente. Peligro EN DESCENSO.

El próximo boletín será emitido el día 2026-04-04

5 MUY FUERTE	4 FUERTE	3 NOTABLE	2 LIMITADO	1 DÉBIL

EAWS EUROPEAN AVALANCHE WARNING SERVICES

ICGC Institut Cartogràfic i Geològic de Catalunya

Servei Meteorològic de Catalunya

Boletín de peligro de aludes Perafita-Puigpedrós Del 03/04/2026 al 04/04/2026

(Válido fuera pistas de esquí y zonas no controladas)

LIMITADO (2)

Situación primaria

Nieve húmeda

Distribución

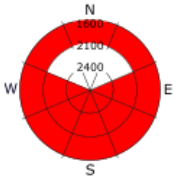

Tamaño

Origen

Tendencia

Situación secundaria

Nieve venteada

Distribución

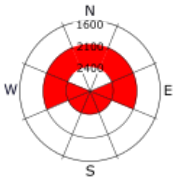

Tamaño

Origen

Tendencia

Estado del manto nivoso

Durante la jornada humedeciendo la nieve. A primera hora el manto estará encostrado en muchos lugares, pero irá transformando por la insolación y las temperaturas elevadas, pudiendo caer purgas de nieve húmeda en terreno inclinado, especialmente alrededor de puntos oscuros y afectando principalmente a la nieve de los últimos episodios. Además, actualmente existen placas de viento en lugares protegidos de todas las orientaciones. Se trata de acumulaciones locales, más abundantes y de mayor tamaño en la mitad norte del sector, y que pueden desprenderse al paso de una persona. El sábado serán más fáciles de desencadenar aquellas que se encuentren en terreno umbrío o cerca de las cimas y crestas más elevadas en solanas. En caso de caer, los aludes podrán alcanzar tamaño 2 o, de forma local, tamaño 3 (suficiente para enterrar a un grupo de personas) en sotaventos muy claros del norte del sector.

Distribución del manto nivoso

Hay nieve por encima de 1.500 m en umbrías por las últimas nevadas, con continuidad por encima de unos 1.900 m, y de 2.200 m en solanas. Es esquiable a partir de unos 2.000 m en N. Los espesores, aunque irregulares, rondan los 80-120 cm en umbrías, a 2.300 m; existen frecuentes deflaciones y acumulaciones por encima del nivel del bosque. Son grosores por encima de los habituales en esta época.

Tendencia para las próximas 48-72h

Continuará avanzando el humedecimiento de la nieve, aunque no se espera una actividad de aludes de nieve húmeda muy frecuente. Peligro EN DESCENSO.

El próximo boletín será emitido el día 2026-04-04

5 MUY FUERTE	4 FUERTE	3 NOTABLE	2 LIMITADO	1 DÉBIL

EAWS EUROPEAN AVALANCHE WARNING SERVICES

ICGC Institut Cartogràfic i Geològic de Catalunya

Servei Meteorològic de Catalunya

Boletín de peligro de aludes Vessant Nord Cadí-Moixeró Del 03/04/2026 al 04/04/2026

(Válido fuera pistas de esquí y zonas no controladas)

LIMITADO (2) en el Moixeró por encima del nivel del bosque.
DÉBIL (1) en el resto.

Situación primaria

Nieve venteada

Distribución

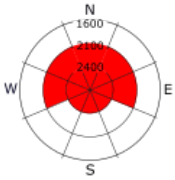

Tamaño

Origen

Tendencia

Situación secundaria

Nieve húmeda

Distribución

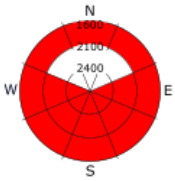

Tamaño

Origen

Tendencia

Estado del manto nivoso

Actualmente hay placas de viento, principalmente en el Moixeró, ya que en el Cadí las nevadas han sido muy escasas. Se trata de placas duras pero lo suficientemente delgadas para ser desencadenadas al paso de una sola persona. Se encuentran principalmente en sotaventos orientados a sur y este, pero también a zonas muy resguardadas del viento del resto de orientaciones. En caso de desprenderse se tratará de aludes de hasta tamaño 2, suficiente para enterrar a una persona. Las placas en el terreno más soleado tenderán a estabilizar.
Además, se espera que el sábado continúe el humedecimiento del manto debido a la insolación y al incremento de temperaturas. Podría haber aludes que afectarán sobre todo a la nieve más reciente, blanda y superficial, proveniente del episodio entre el martes y el miércoles. Los posibles aludes tendrán lugar en el terreno más soleado y serán por lo general de tamaño 1, suficiente para producir caídas y lesiones.

Distribución del manto nivoso

Podemos encontrar una delgada capa de nieve a 1.700 m por el último episodio de nevadas, pero en solanas el manto no es continuo hasta unos 1.900 m. Los grosores están alrededor de 160-180 cm a 2.200 m, con algunas acumulaciones y deflaciones por encima del nivel del bosque. Estos valores son muy excedentarios para la época del año.

Tendencia para las próximas 48-72h

Irá tomando terreno el problema de nieve húmeda. Peligro EN DESCENSO.

El próximo boletín será emitido el día 2026-04-04

5 MUY FUERTE	4 FUERTE	3 NOTABLE	2 LIMITADO	1 DÉBIL

EAWS EUROPEAN AVALANCHE WARNING SERVICES

ICGC Institut Cartogràfic i Geològic de Catalunya

Servei Meteorològic de Catalunya

Boletín de peligro de aludes Prepirineu
Del 03/04/2026 al 04/04/2026

(Válido fuera pistas de esquí y zonas no controladas)

LIMITADO (2) en el Moixeró por encima del nivel del bosque.
DÉBIL (1) en el resto.

Situación primaria

Nieve húmeda

Distribución

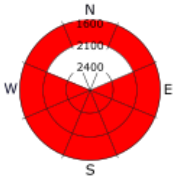

Tamaño

Origen

Tendencia

Situación secundaria

Nieve venteada

Distribución

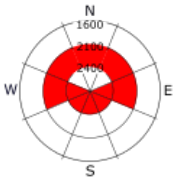

Tamaño

Origen

Tendencia

Estado del manto nivoso
Se espera que el manto humedece a causa de la insolación y el incremento de temperaturas. Podría haber aludes que afectarán sobre todo a la nieve más reciente, blanda y superficial, proveniente del episodio entre el martes y el miércoles. Los posibles aludes tendrán lugar en el terreno más soleado y serán por lo general de tamaño 1, suficiente para producir caídas y lesiones. Actualmente hay placas de viento, principalmente en el Moixeró, ya que en el Cadí las nevadas han sido muy escasas. Se trata de placas duras pero lo suficientemente delgadas para ser desencadenadas al paso de una sola persona. Se encuentran principalmente en sotaventos orientados a sur y este, pero también a zonas muy resguardadas del viento del resto de orientaciones. En caso de desprenderse se tratará de aludes de hasta tamaño 1, aunque no se descartan mayores en el Moixeró. En terreno soleado será más difícil el desencadenamiento accidental de placas.

Distribución del manto nivoso
Aunque podemos encontrar nieve en cotas más bajas por último episodio de nevadas, el manto es continuo por encima de unos 1.700 m en terreno umbrío y de unos 1.900 ma solanas. Los espesores, aunque irregulares, rondan los 90-120 cm a 2.300 m.

Tendencia para las próximas 48-72h
Continuará ganando protagonismo el problema de la nieve húmeda, con rehielo matinal efectivo y humedecimiento superficial asociado al calor y la insolación. Peligro EN DESCENSO.

El próximo boletín será emitido el día 2026-04-04

5 MUY FUERTE	4 FUERTE	3 NOTABLE	2 LIMITADO	1 DÉBIL

EAWS EUROPEAN AVALANCHE WARNING SERVICES

ICGC Institut Cartogràfic i Geològic de Catalunya

Servei Meteorològic de Catalunya

Boletín de peligro de aludes Ter-Freser Del 03/04/2026 al 04/04/2026

(Válido fuera pistas de esquí y zonas no controladas)

LIMITADO (2)

Situación primaria

Nieve venteada

Distribución

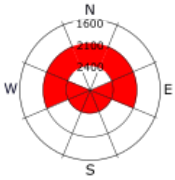

Tamaño

Origen

Tendencia

Situación secundaria

Nieve húmeda

Distribución

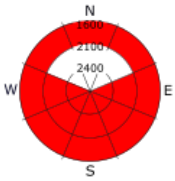

Tamaño

Origen

Tendencia

Estado del manto nivoso

Actualmente hay placas de viento en el sector, ubicadas a sotaventos de las diferentes orientaciones. Se trata de placas duras, por lo general, pero sensibles al desencadenamiento al paso de una persona, las más gruesas a orientaciones sur. Aunque tienden a estabilizar a orientaciones soleadas, todavía sería posible su desencadenamiento accidental por encima de 2.400 m, y no se descarta que los aludes alcancen tamaño 3, suficiente para enterrar a un grupo de personas. En el resto del terreno, los aludes de placa de viento serán de tamaño 2, suficiente para enterrar a una persona. La nieve humedecerá el viernes por el sol y el incremento de temperatura, dando lugar a purgas de nieve húmeda en muchas vertientes, que afectarán sobre todo a la nieve de los últimos episodios, es decir, la que queda por encima de la corteza marrón. Serán aludes de tamaño 1 por lo general, pero no se descarta algún alud de nieve húmeda de tamaño 2.

Distribución del manto nivoso

Hay algo de nieve en el suelo por encima de unos 1.400 ma umbrías por el último episodio de nevadas. El manto es esquiable a umbrías a partir de unos 1.800 m en umbrías. Los grosores son muy excedentarios para la época del año y en lugares no afectados por el viento oscilan entre 70-100 cm a unos 2.000 m, y más de 150 cm por encima de 2.400 m, muy variable por los efectos del viento.

Tendencia para las próximas 48-72h

Condiciones típicamente primaverales, con manto endurecido a primera hora y humedecimiento, y algunos aludes de fusión, a lo largo de las horas de sol. Tendencia a la estabilización de las placas de viento. Peligro EN DESCENSO.

El próximo boletín será emitido el día 2026-04-04

5 MUY FUERTE	4 FUERTE	3 NOTABLE	2 LIMITADO	1 DÉBIL

EAWS EUROPEAN AVALANCHE WARNING SERVICES