MINISTERO DELLA DIFESA

meteomont Servizio Nazionale di previsione neve e valanghe

EAWS EUROPEAN AVALANCHE WARNING SERVICES

CARABINIERI

In collaborazione con: arpav

# DOLOMITI MERIDIONALI

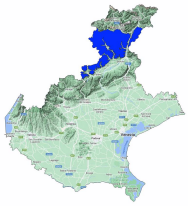

Bollettino Valanghe N. 394/2026 del 02/04/2026 ore 14.00
Validità 48 ore prossima emissione 03/04/2026

**A cura del Servizio METEOMONT dell'ARMA dei CARABINIERI**
**In collaborazione con Servizio Meteorologico dell'Aeronautica militare**

## SITUAZIONE alle 14:00 del 02/04/2026

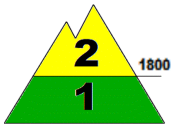


**SITUAZIONE TIPO: neve a debole coesione e vento.**




**SITUAZIONE TIPO: passaggio da poca a molta neve.**

| Quota neve (mslm) | Nord | Sud |
|---|---|---|
| | 1500 - 1800 | 1900 - 2200 |

| Altezza Neve (cm) | Neve al suolo | Neve Fresca | Quota (mslm) |
|---|---|---|---|
| | 90 | 000 | 2000 |
| | 80 | 000 | 2300 |

**VALANGHE OSSERVATE: Nessuna valanga.**

## PREVISIONI 03/04/2026

## GRADO DI PERICOLO: MODERATO 2

## SITUAZIONE TIPO: neve a debole coesione e vento.

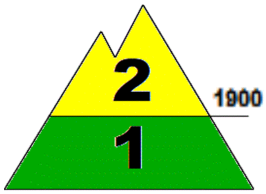


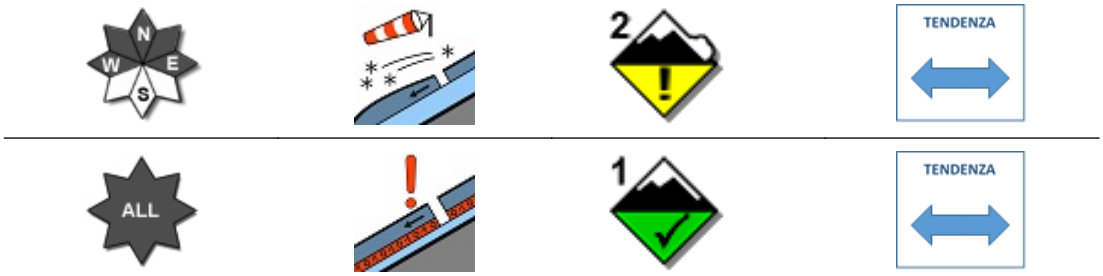


## SITUAZIONE TIPO: passaggio da poca a molta neve.

**MANTO NEVOSO: La stabilità del manto nevoso è scarsa su pochi punti (aree) per versanti da ovest a est al di sopra di 1900 mslm, possibili valanghe di dimensioni grandi.**
**La stabilità del manto nevoso è discreta su pochi punti (aree) per tutte le esposizioni al di sotto di 1900 mslm, possibili valanghe di dimensioni medie.**

## AVVERTENZE

In considerazione degli importanti accumuli di neve ventata in conche, canaloni, cambi di pendenza e pendii sotto vento in genere, è richiesta un'ottima valutazione locale della stabilità ed individuazione dell'itinerario.

## SCALA EUROPEA DEL GRADO DI PERICOLO VALANGHE

## LEGENDA PROBLEMA

**Bollettino realizzato su scala sinottica-regionale (standard EAWS). La sua valutazione non può escludere in alcun modo la necessità di una seria e capace valutazione locale del pericolo (singolo pendio) che può essere anche sensibilmente diverso. Le previsioni meteorologiche sono relative all'orario UTC (per l'Italia +1 in inverno e +2 in estate).**

MINISTERO DELLA DIFESA

meteomont
Servizio Nazionale di previsione neve e valanghe

EAWS EUROPEAN AVALANCHE WARNING SERVICES

CARABINIERI

In collaborazione con: arpav

# DOLOMITI MERIDIONALI

## PREVISIONE METEO

| Quota | | 03/04/2026 h6:00 | 03/04/2026 h12:00 | 03/04/2026 h18:00 |
|---|---|---|---|---|
| 1000 | Venti | 03 nodi da N-Ovest | 01 Nodi da Est | 02 nodi da N-Ovest |
| | Temperature | +03 °C | +09 °C | +06 °C |
| | Temp.percepita | 2 °C | 9 °C | 6 °C |
| 2000 | Venti | 02 Nodi da Nord | 02 Nodi da Nord | 03 Nodi da Nord |
| | Temperature | +00 °C | +01 °C | +01 °C |
| | Temp.percepita | 0 °C | 1 °C | -1 °C |
| 3000 | Venti | 02 Nodi da Nord | 03 Nodi da Nord | 04 Nodi da Nord |
| | Temperature | -08 °C | -08 °C | -07 °C |
| | Temp.percepita | -8 °C | -11 °C | -11 °C |
| Zero termico | | 1900-2100 m. | 2000-2200 m. | 2100-2300 m. |
| Fenomeno | | — | — | — |
| Stato del cielo | | | | |

## LEGENDA FENOMENI

— Assenza Fenomeni · Nebbia · Foschia · Pioggia debole · Pioggia moderata · Pioggia forte · Temporali

Nevicata debole · Nevicata moderata · Nevicata forte

## STATO DEL CIELO

Sereno · Poco nuvoloso · Nuvoloso · Molto nuvoloso · Coperto

## Parametri meteonivometrici registrati presso i campi di rilevamento il 02/04/2026.

| Località | Comune | Quota (m.s.l.m.) | Altezza neve (cm) | Neve caduta nelle 24 ore (cm) | Temp. Min (°C) | Temp. Max (°C) | Condizioni del tempo |
|---|---|---|---|---|---|---|---|
| LE BUSE | Falcade (BL) | 1820 | 60 | 0 | -5 | +7 | Assenza di precipitazioni |
| P.SO PADON | Livinallongo del Col di Lana (BL) | 2369 | 80 | 0 | -7 | -1 | Assenza di precipitazioni |
| PIZ FORCA * | Falcade (BL) | 2285 | 32 | 0 | N.P. | N.P. | Assenza di precipitazioni |

(*) Rilievi fuori campo

**L'INFORMAZIONE E' PREVENZIONE - LEGGI L'ATTUALE GRADO DI PERICOLO VALANGHE!**

**IL CAPO DEL CENTRO NAZIONALE METEOMONT**
**(Ten. Col. RFI Emanuela Gini)**
**FIRMA AUTOGRAFA OMESSA AI SENSI**
**DELL'ART.3 DEL D.LGS N.39/1993**

Bollettino realizzato su scala sinottica-regionale (standard EAWS). La sua valutazione non può escludere in alcun modo la necessità di una seria e capace valutazione locale del pericolo (singolo pendio) che può essere anche sensibilmente diverso. Le previsioni meteorologiche sono relative all'orario UTC (per l'Italia +1 in inverno e +2 in estate).