MINISTERO DELLA DIFESA

meteomont
Servizio Nazionale di previsione neve e valanghe

EAWS EUROPEAN AVALANCHE WARNING SERVICES

CARABINIERI

GRAN SASSO EST - LAGA EST

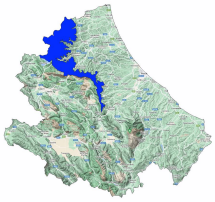

Bollettino Valanghe N. 382/2026 del 03/04/2026 ore 14.00
Validità 48 ore prossima emissione 04/04/2026
A cura del Servizio METEOMONT dell'ARMA dei CARABINIERI
In collaborazione con Servizio Meteorologico dell'Aeronautica militare

SITUAZIONE alle 14:00 del 03/04/2026

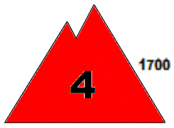

SITUAZIONE TIPO: neve a debole coesione e vento.



SITUAZIONE TIPO: pioggia su neve.

	Nord	Sud
Quota neve (mslm)	*800 - 900*	*900 - 1000*

	Neve al suolo	Neve Fresca	Quota (mslm)
Altezza Neve (cm)	*300*	*010*	*1753*
	175	*017*	*1380*

VALANGHE OSSERVATE: Alcune valanghe di grandi dimensioni, Valanghe di neve a debole coesione di fondo.

PREVISIONI 04/04/2026

GRADO DI PERICOLO: FORTE 4

SITUAZIONE TIPO: neve a debole coesione e vento.



SITUAZIONE TIPO: situazione primaverile.

MANTO NEVOSO: La stabilità del manto nevoso è scarsa su molti punti (aree) per tutte le esposizioni al di sopra di 1700 mslm, possibili valanghe di dimensioni grandi.
La stabilità del manto nevoso è scarsa su molti punti (aree) per tutte le esposizioni al di sotto di 1700 mslm, possibili valanghe di dimensioni grandi.

AVVERTENZE

Sono assolutamente da evitare le attività escursionistiche al di fuori dalle piste battute e segnalate.

SCALA EUROPEA DEL GRADO DI PERICOLO VALANGHE

LEGENDA PROBLEMA

Bollettino realizzato su scala sinottica-regionale (standard EAWS). La sua valutazione non può escludere in alcun modo la necessità di una seria e capace valutazione locale del pericolo (singolo pendio) che può essere anche sensibilmente diverso. Le previsioni meteorologiche sono relative all'orario UTC (per l'Italia +1 in inverno e +2 in estate).

MINISTERO DELLA DIFESA

meteomont
Servizio Nazionale di previsione neve e valanghe

EAWS EUROPEAN AVALANCHE WARNING SERVICES

CARABINIERI

GRAN SASSO EST - LAGA EST

PREVISIONE METEO

Quota		04/04/2026 h6:00	04/04/2026 h12:00	04/04/2026 h18:00
1000	Venti	03 Nodi da N-Est	03 Nodi da N-Est	03 Nodi da Est
	Temperature	+01 °C	+02 °C	+03 °C
	Temp.percepita	-1 °C	0 °C	2 °C
2000	Venti	11 Nodi da N-Est	10 Nodi da N-Est	09 Nodi da N-Est
	Temperature	-01 °C	+00 °C	+02 °C
	Temp.percepita	-7 °C	-5 °C	-2 °C
3000	Venti	15 Nodi da N-Est	14 Nodi da N-Est	15 Nodi da N-Est
	Temperature	-06 °C	-04 °C	-03 °C
	Temp.percepita	-14 °C	-11 °C	-10 °C
Zero termico		1700-1900 m.	1900-2100 m.	2200-2400 m.
Fenomeno		—	—	—
Stato del cielo				

LEGENDA FENOMENI

— Assenza Fenomeni · Nebbia · Foschia · Pioggia debole · Pioggia moderata · Pioggia forte · Temporali

Nevicata debole · Nevicata moderata · Nevicata forte

STATO DEL CIELO

Sereno · Poco nuvoloso · Nuvoloso · Molto nuvoloso · Coperto

Parametri meteonivometrici registrati presso i campi di rilevamento il 03/04/2026.

Località	Comune	Quota (m.s.l.m.)	Altezza neve (cm)	Neve caduta nelle 24 ore (cm)	Temp. Min (°C)	Temp. Max (°C)	Condizioni del tempo
FAVACCHIOLE	Crognaleto (TE)	1016	54	0	+1	+2	Pioggia debole continua
STELLA ALPINA DI FARINDOLA *	Farindola (PE)	968	30	0	+0	+5	Pioggia debole intermittente
PIANO SAN PIETRO	Isola del Gran Sasso d'Italia (TE)	950	53	0	N.P.	N.P.	Pioggia debole intermittente
PRATI DI TIVO	Pietracamela (TE)	1380	175	17	0	+1	Pioggia mista a neve
CEPPO	Rocca Santa Maria (TE)	1349	110	N.P.	+1	+1	Pioggia debole intermittente
SAN PAOLO	Acquasanta Terme (AP)	960	28	0	+1	+2	Pioggia moderata
COLLE SAN GIACOMO	Civitella del Tronto (TE)	1075	40	0	-2	+5	Assenza di precipitazioni
PILONE DI MEZZO *	Pietracamela (TE)	1753	300	10	N.P.	N.P.	Pioggia debole intermittente

(*) Rilievi fuori campo

L'INFORMAZIONE E' PREVENZIONE - LEGGI L'ATTUALE GRADO DI PERICOLO VALANGHE!

IL CAPO DEL CENTRO NAZIONALE METEOMONT
(Ten. Col. RFI Emanuela Gini)
FIRMA AUTOGRAFA OMESSA AI SENSI
DELL'ART.3 DEL D.LGS N.39/1993

Bollettino realizzato su scala sinottica-regionale (standard EAWS). La sua valutazione non può escludere in alcun modo la necessità di una seria e capace valutazione locale del pericolo (singolo pendio) che può essere anche sensibilmente diverso. Le previsioni meteorologiche sono relative all'orario UTC (per l'Italia +1 in inverno e +2 in estate).