MINISTERO DELLA DIFESA

meteomont
Servizio Nazionale di previsione neve e valanghe

EAWS EUROPEAN AVALANCHE WARNING SERVICES

CARABINIERI

AERONAUTICA MILITARE SERVIZIO METEOROLOGICO

MAJELLA

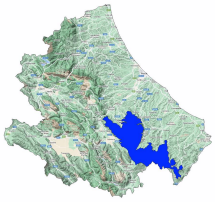

Bollettino Valanghe N. 380/2026 del 02/04/2026 ore 14.00
Validità 48 ore prossima emissione 03/04/2026

A cura del Servizio METEOMONT dell'ARMA dei CARABINIERI
In collaborazione con Servizio Meteorologico dell'Aeronautica militare

SITUAZIONE alle 14:00 del 02/04/2026

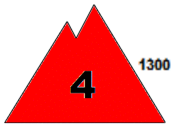

SITUAZIONE TIPO: neve a debole coesione e vento.



SITUAZIONE TIPO: pioggia su neve.

Quota neve (mslm)	Nord	Sud
	900 - 1000	1000 - 1100

Altezza Neve (cm)	Neve al suolo	Neve Fresca	Quota (mslm)
	141	015	1164
	120	005	1250

VALANGHE OSSERVATE: -.

PREVISIONI 03/04/2026

GRADO DI PERICOLO: FORTE 4

SITUAZIONE TIPO: neve a debole coesione e vento.



SITUAZIONE TIPO: pioggia su neve.

MANTO NEVOSO: La stabilità del manto nevoso è scarsa su molti punti (aree) per tutte le esposizioni al di sopra di 1400 mslm, possibili valanghe di dimensioni grandi.
La stabilità del manto nevoso è scarsa su molti punti (aree) per tutte le esposizioni al di sotto di 1400 mslm, possibili valanghe di dimensioni grandi.

AVVERTENZE

Sono assolutamente da evitare le attività escursionistiche al di fuori dalle piste battute e segnalate.

SCALA EUROPEA DEL GRADO DI PERICOLO VALANGHE

LEGENDA PROBLEMA

Bollettino realizzato su scala sinottica-regionale (standard EAWS). La sua valutazione non può escludere in alcun modo la necessità di una seria e capace valutazione locale del pericolo (singolo pendio) che può essere anche sensibilmente diverso. Le previsioni meteorologiche sono relative all'orario UTC (per l'Italia +1 in inverno e +2 in estate).

MINISTERO DELLA DIFESA

meteomont
Servizio Nazionale di previsione neve e valanghe

EAWS EUROPEAN AVALANCHE WARNING SERVICES

CARABINIERI

MAJELLA

PREVISIONE METEO

Quota		03/04/2026 h6:00	03/04/2026 h12:00	03/04/2026 h18:00
1000	Venti	04 Nodi da Nord	04 Nodi da N-Est	03 Nodi da Nord
	Temperature	-02 °C	-01 °C	-02 °C
	Temp.percepita	-5 °C	-4 °C	-4 °C
2000	Venti	11 Nodi da Nord	08 Nodi da N-Est	09 Nodi da Nord
	Temperature	-04 °C	-03 °C	-03 °C
	Temp.percepita	-10 °C	-8 °C	-8 °C
3000	Venti	17 Nodi da N-Est	12 Nodi da N-Est	07 Nodi da Nord
	Temperature	-08 °C	-07 °C	-05 °C
	Temp.percepita	-17 °C	-14 °C	-10 °C
Zero termico		1300-1500 m.	1400-1600 m.	1300-1500 m.
Fenomeno				—
Stato del cielo				

LEGENDA FENOMENI

— Assenza Fenomeni
Nebbia
Foschia
Pioggia debole
Pioggia moderata
Pioggia forte
Temporali
Nevicata debole
Nevicata moderata
Nevicata forte

STATO DEL CIELO

Sereno
Poco nuvoloso
Nuvoloso
Molto nuvoloso
Coperto

Parametri meteonivometrici registrati presso i campi di rilevamento il 02/04/2026.

Località	Comune	Quota (m.s.l.m.)	Altezza neve (cm)	Neve caduta nelle 24 ore (cm)	Temp. Min (°C)	Temp. Max (°C)	Condizioni del tempo
QUARTARANA	Campo di Giove (AQ)	1200	95	35	-2	+2	Nevicata moderata
VALICO FORCHETTA *	Palena (CH)	1250	120	5	0	+2	Nevicata debole continua
PIZZOFERRATO *	Pizzoferrato (CH)	1440	38	3	N.P.	N.P.	Nevicata debole continua
SCHIAPPARO *	Pretoro (CH)	1164	141	15	N.P.	N.P.	Pioggia mista a neve
GIARDINO BOTANICO *	Sant'Eufemia a Maiella (PE)	915	85	0	N.P.	N.P.	Pioggia moderata
MONTE ROTELLA *	Rocca Pia (AQ)	1695	139	10	N.P.	N.P.	Nevicata debole continua

(*) Rilievi fuori campo

L'INFORMAZIONE E' PREVENZIONE - LEGGI L'ATTUALE GRADO DI PERICOLO VALANGHE!

IL CAPO DEL CENTRO NAZIONALE METEOMONT
(Ten. Col. RFI Emanuela Gini)
FIRMA AUTOGRAFA OMESSA AI SENSI
DELL'ART.3 DEL D.LGS N.39/1993

Bollettino realizzato su scala sinottica-regionale (standard EAWS). La sua valutazione non può escludere in alcun modo la necessità di una seria e capace valutazione locale del pericolo (singolo pendio) che può essere anche sensibilmente diverso. Le previsioni meteorologiche sono relative all'orario UTC (per l'Italia +1 in inverno e +2 in estate).