Bulletin d'estimation du risque d'avalanche

(valable en dehors des pistes balisées et ouvertes)

MASSIF : Aravis

Rédigé le vendredi 3 avril 2026 à 16h

Estimation des risques pour le : SAMEDI 04 AVRIL

RETOUR DU PRINTEMPS EN MONTAGNE.

2

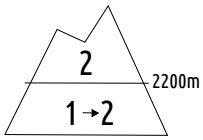

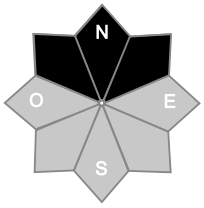

Au-dessus de 2200m indice de risque limité, plus bas indice faible évoluant en limité.

Départs spontanés : Coulées humides au soleil.

Déclenchements provoqués : Plaques à vent encore un peu réactives en adrets d'altitude.

Indices de risque : 5 très fort - 4 fort - 3 marqué - 2 limité - 1 faible -- En noir : les pentes les plus dangereuses

Stabilité du manteau neigeux

Situation avalancheuse typique : neige ventée — neige humide

Déclenchements provoqués :

* Des plaques à vent sont encore présentes dans la neige récente et froide en altitude. Elles se sont formées sous la Bise des derniers jours. Ces plaques sont présentes principalement près des arêtes/crêtes, mais dans les secteurs les plus exposés, on peut en retrouver plus bas. Cassure de 20/40 cm, localement un peu plus. Taille 1 à 2 (petites à moyennes).
* Au fil de l'humidification, ces plaques sont temporairement plus réactives, mais ne sont pas plus épaisses ni larges.

Départs spontanés :

* Coulées de neige humide en journée sous le soleil au fil de l'humidification. Les orientations concernées évoluent au fil de l'ensoleillement. Les pentes raides réagissent un peu plus rapidement.
* A toute heure du jour et de la nuit, des fissures de reptations peuvent s'ouvrir et des avalanches de fond sont possibles sur les terrains lisses (pentes herbeuses, dalles rocheuses, ...). Taille 1 à 2.

Qualité de la neige

Enneigement :

Bon pour un début avril. On peut chausser skis ou raquettes dès 1200/1300 m en versants N, et 1400/1600 m en versants S.

Qualité de la neige ce samedi :

* 20/30 cm de neige froide récente et meuble, reposant sur un fond dur.
* Selon l'exposition au vent de N/NE de la semaine passée, on retrouve parfois des accumulations de neige plus importantes, ou au contraire, des zones dures voire ravagées par le vent. Les crêtes et sommets sont les plus ravagées par le vent.
* Nombreuses corniches et accumulations/congères.
* En cours de journée, la neige s'humidifie dans un large sud (SE/S/SW/S).

Aperçu météo pour le samedi 04 avril

nuit	matin	après-midi	soir

Remontée brutale des températures. Sensation de chaleur très marquée.

Pluie-Neige				
Iso 0 °C	2 000 m	2 800 m	3 000 m	3 100 m
Vent 2000 m	↓ 15 km/h	↙ 15 km/h	↙ 5 km/h	↗ 10 km/h
Vent 2500 m	↓ 25 km/h	↙ 20 km/h	↙ 10 km/h	← 15 km/h

Épaisseur de neige hors-piste

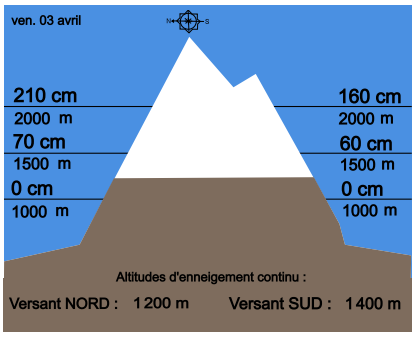

Précipitations à 1800 m

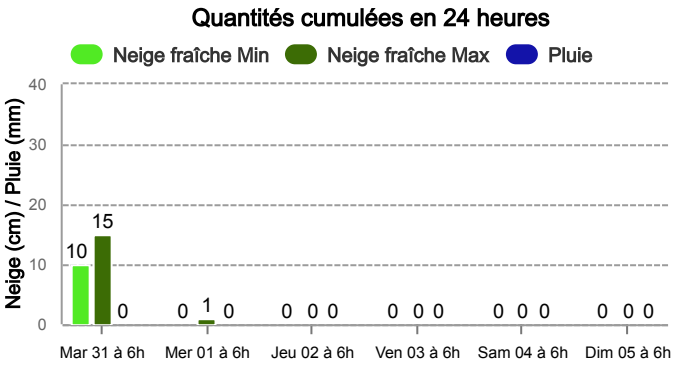

Tendance du dimanche 05 avril

2

Indice de risque limité

La chaleur se poursuit et les risques liés à l'humidification de la neige sont toujours présents. L'humidification commence également dans les versants nord. Le risque se maintient.

Pour consulter la vigilance en cours, veuillez vous rendre sur le site https://vigilance.meteofrance.fr/fr

Météo-France - 73 avenue de Paris, 94165 Saint-Mandé cedex - Contact : contact@meteo.fr

Rédigé par Météo-France avec la contribution des observateurs du réseau nivo-météorologiques. Partenariat : ANMSM (Maires de Stations de Montagne), DSF (Domaines Skiables de France), ADSP (Directeurs de Pistes et de la Sécurité des Stations de Sports d'Hiver) et autres acteurs de la montagne.

Bulletin neige & avalanches par téléphone au 0 892 68 10 20 Service 0,35 € / min + prix appel

RÉPUBLIQUE FRANÇAISE
Liberté Égalité Fraternité

METEO FRANCE
À VOS CÔTÉS, DANS UN CLIMAT QUI CHANGE

Bulletin d'estimation du risque d'avalanche

(valable en dehors des pistes balisées et ouvertes)

MASSIF : Aravis

Rédigé le vendredi 3 avril 2026 à 16h

Conditions nivo-météo des 7 derniers jours

	sam. 28/03				dim. 29/03				lun. 30/03				mar. 31/03				mer. 01/04				jeu. 02/04				ven. 03/04			
	03h	09h	15h	21h	03h	09h	15h	21h	03h	09h	15h	21h	03h	09h	15h	21h	03h	09h	15h	21h	03h	09h	15h	21h	03h	09h	15h	21h
Météo																												
Vent (km/h)	40	40	30	50	60	50	30	30	25	35	45	65	65	65	60	60	70	70	50	40	30	40	40	50	50	30	20	15
à 2500m																												
Vent (km/h)	30	30	20	40	50	30	20	20	10	20	35	40	45	40	45	40	40	35	35	20	20	20	30	30	20	20	15	5
à 2000m																												

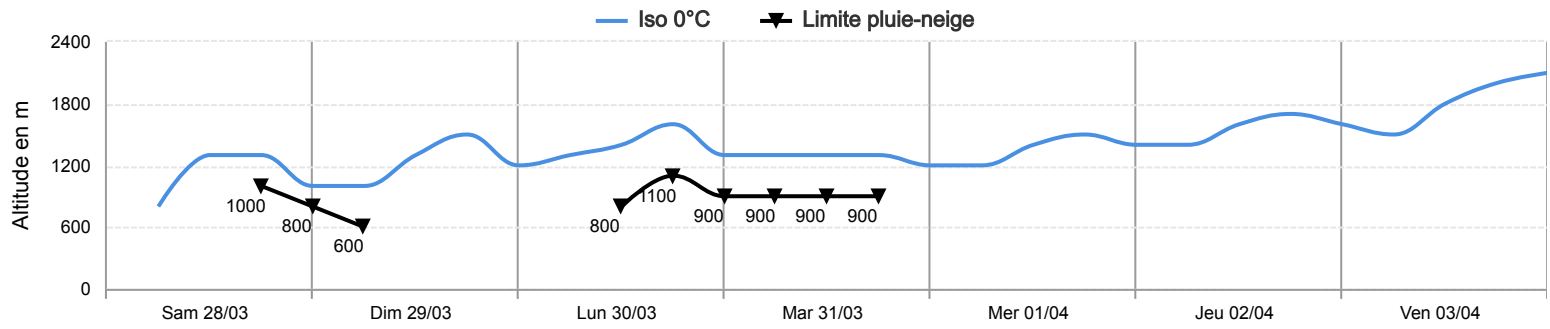

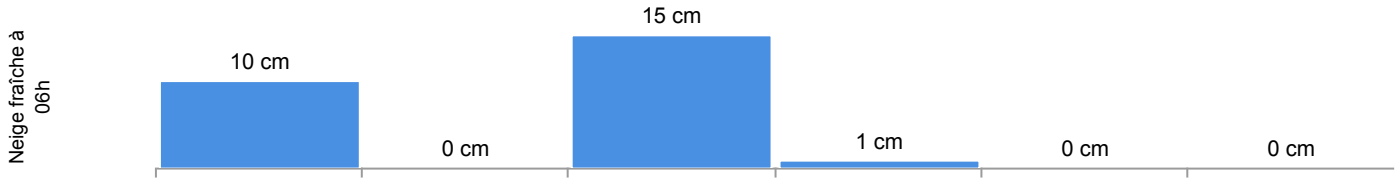

Risque d'avalanche	sam. 28/03	dim. 29/03	lun. 30/03	mar. 31/03	mer. 01/04	jeu. 02/04	ven. 03/04
	2	2	2	3	3	2	2

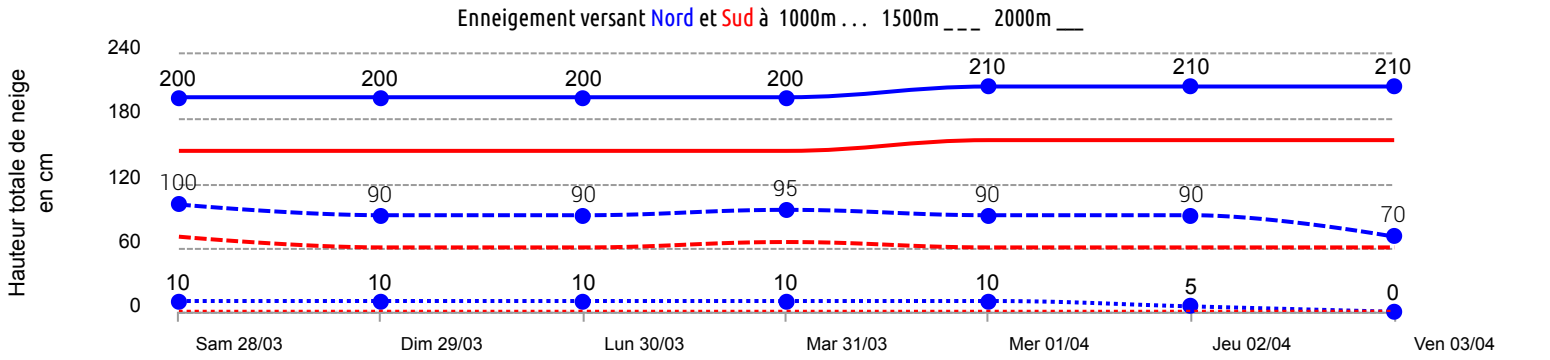

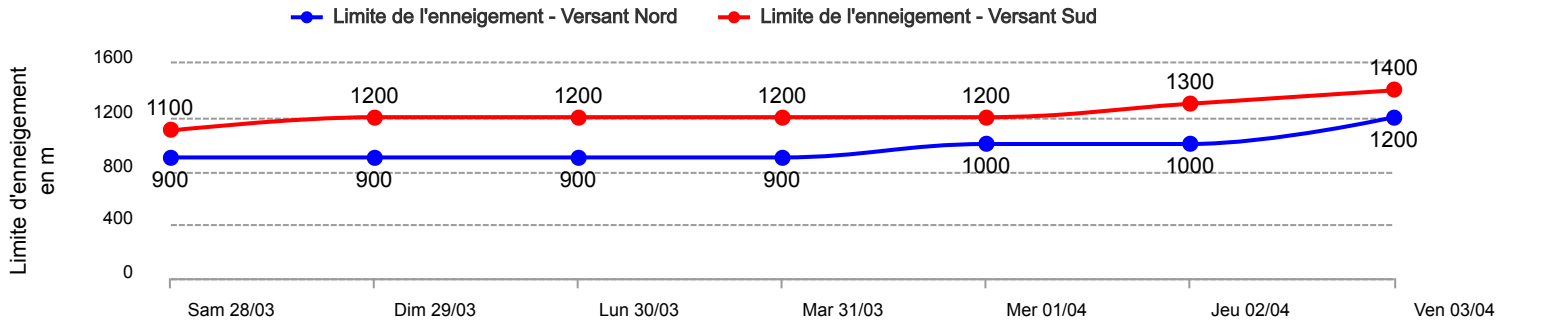

Pour consulter la vigilance en cours, veuillez vous rendre sur le site https://vigilance.meteofrance.fr/fr

Météo-France - 73 avenue de Paris, 94165 Saint-Mandé cedex - Contact : contact@meteo.fr

Bulletin neige & avalanches par téléphone au

0 892 68 10 20 Service 0,35 € / min + prix appel

Rédigé par Météo-France avec la contribution des observateurs du réseau nivo-météorologiques. Partenariat : ANMSM (Maires de Stations de Montagne), DSF (Domaines Skiables de France), ADSP (Directeurs de Pistes et de la Sécurité des Stations de Sports d'Hiver) et autres acteurs de la montagne.