# Bulletin d'estimation du risque d'avalanche

(valable en dehors des pistes balisées et ouvertes)

# MASSIF : Belledonne

Rédigé le vendredi 3 avril 2026 à 16h

## Estimation des risques pour le : SAMEDI 04 AVRIL

**REDOUX AU SOLEIL, QUELQUES COULEES OU AVALANCHES HUMIDES AU FIL DES HEURES... EN NORD D'ALTITUDE, RARES PLAQUES...**

2

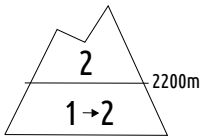


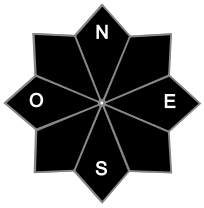


Au soleil + rares N

Au-dessus de 2200m indice de risque limité, plus bas indice faible évoluant en limité.

**Départs spontanés :** Suivant la course du soleil, quelques nouvelles coulées puis avalanches en pentes raides/humidifiées (près des rochers), de taille 1 à 2...

**Déclenchements provoqués :** Rare plaque de surface en versant Nord à Nord-Ouest d'altitude. En pente bien humide, possible coulée ponctuelle sous les skis...

Indices de risque : 5 très fort - 4 fort - 3 marqué - 2 limité - 1 faible -- En noir : les pentes les plus dangereuses

## Stabilité du manteau neigeux

**Situation avalancheuse typique :** neige humide neige ventée

*Un peu d'activité printanière suivant la course du soleil, et plus en altitude. En faces Nord de rares plaques. Attention aux surfaces durcies/regelées.*

**Départs spontanés :**

Regel nocturne puis samedi le redoux sera net en versants ensoleillés et se produit davantage en altitude. Au fil de la journée et notamment près des rochers on peut s'attendre à quelques nouvelles coulées humides. En longue pente raide possible avalanche plus conséquente.
Une rupture spontanée de corniche n'est pas exclue, notamment sous 2500m environ...

**Déclenchements provoqués :**

En faces Nord d'altitude, la neige récente a été soufflée (bise de Nord-Est). Risque résiduel de plaque de surface, parfois dure. Le travail du vent est les accumulations seraient assez visibles, prendre des distances... Rupture potentielle 20/40 cm environ
En pentes soutenues et bien humidifiées (suivant la course du soleil), le skieur se méfiera d'un risque de coulée humide ponctuelle sous un virage, la neige plus récente pouvant glisser sur les sous-couches denses...

**Autres :** A l'ombre neige durcie par le regel, anciennes traces parfois lustrées. En pentes où le soleil est plus rasant des secteurs temporairement croutés et ski délicat....

## Qualité de la neige

**Qualification de l'enneigement :** L'enneigement est bon dès la moyenne montagne, et même abondant vers les combes d'altitude
**Limites skiables :** Vers 1100/1300m en plein Nord (hors sapins), 1500/1800m au soleil...

**Qualité de la neige samedi :** En Sud neige plus transformée, quasi printanière à modeste altitude... Regel nocturne puis rapide humidification suivant la course du soleil. Humidification plus conséquente par rapport aux jours précédents...
Neige encore sèche en plein Nord au dessus de 2200m environ. Neige poudreuse dense (15/30 cm) ou bien cartonnée/durcie par la bise du début de semaine...

## Aperçu météo pour le samedi 04 avril

| | nuit | matin | après-midi | soir |
|---|---|---|---|---|
| | | | | |

Grand beau. Regel nocturne, puis net redoux en journée, très printanier !

| Pluie-Neige | | | | |
|---|---|---|---|---|
| Iso 0 °C | 2 100 m | 2 900 m | 3 000 m | 3 200 m |
| Vent 2000 m | ↙ 15 km/h | ← 15 km/h | → 10 km/h | ← 10 km/h |
| Vent 3000 m | ↓ 35 km/h | ↙ 25 km/h | ↙ 10 km/h | ↗ 5 km/h |

## Épaisseur de neige hors-piste

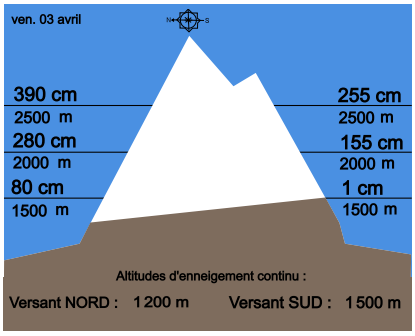


## Précipitations à 1800 m

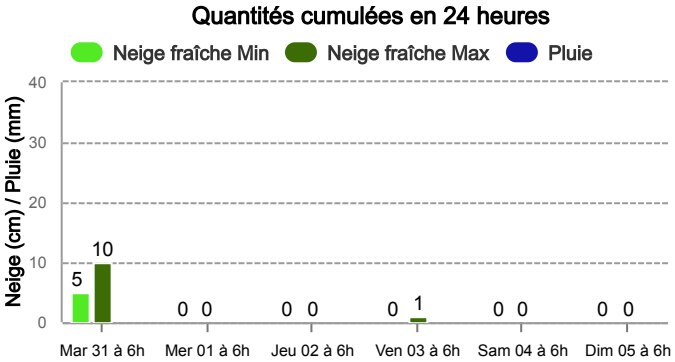


## Tendance du dimanche 05 avril

2

**Indice de risque limité**

Risque stationnaire ou en légère baisse. Quelques coulées ou avalanches de printemps...

Pour consulter la vigilance en cours, veuillez vous rendre sur le site https://vigilance.meteofrance.fr/fr

Météo-France - 73 avenue de Paris, 94165 Saint-Mandé cedex - Contact : contact@meteo.fr

Rédigé par Météo-France avec la contribution des observateurs du réseau nivo-météorologiques. Partenariat : ANMSM (Maires de Stations de Montagne), DSF (Domaines Skiables de France), ADSP (Directeurs de Pistes et de la Sécurité des Stations de Sports d'Hiver) et autres acteurs de la montagne.

Bulletin neige & avalanches par téléphone au **0 892 68 10 20** Service 0,35 € / min + prix appel

RÉPUBLIQUE FRANÇAISE
*Liberté Égalité Fraternité*

METEO FRANCE
À VOS CÔTÉS, DANS UN CLIMAT QUI CHANGE

# Bulletin d'estimation du risque d'avalanche

## (valable en dehors des pistes balisées et ouvertes)

# MASSIF : Belledonne

Rédigé le vendredi 3 avril 2026 à 16h

## Conditions nivo-météo des 7 derniers jours

| | sam. 28/03 | | | | dim. 29/03 | | | | lun. 30/03 | | | | mar. 31/03 | | | | mer. 01/04 | | | | jeu. 02/04 | | | | ven. 03/04 | | | |
|---|---|---|---|---|---|---|---|---|---|---|---|---|---|---|---|---|---|---|---|---|---|---|---|---|---|---|---|---|
| | 03h | 09h | 15h | 21h | 03h | 09h | 15h | 21h | 03h | 09h | 15h | 21h | 03h | 09h | 15h | 21h | 03h | 09h | 15h | 21h | 03h | 09h | 15h | 21h | 03h | 09h | 15h | 21h |
| Météo | | | | | | | | | | | | | | | | | | | | | | | | | | | | |
| Vent (km/h) | 40 | 50 | 50 | 35 | 45 | 35 | 20 | 25 | 40 | 60 | 70 | 85 | 90 | 100 | 100 | 70 | 65 | 55 | 25 | 30 | 35 | 55 | 55 | 55 | 50 | 45 | 40 | 30 |
| à 3000m | | | | | | | | | | | | | | | | | | | | | | | | | | | | |
| Vent (km/h) | 30 | 40 | 40 | 25 | 40 | 25 | 15 | 20 | 30 | 50 | 60 | 65 | 60 | 60 | 60 | 35 | 25 | 15 | 30 | 10 | 15 | 25 | 30 | 20 | 25 | 30 | 15 | 15 |
| à 2000m | | | | | | | | | | | | | | | | | | | | | | | | | | | | |

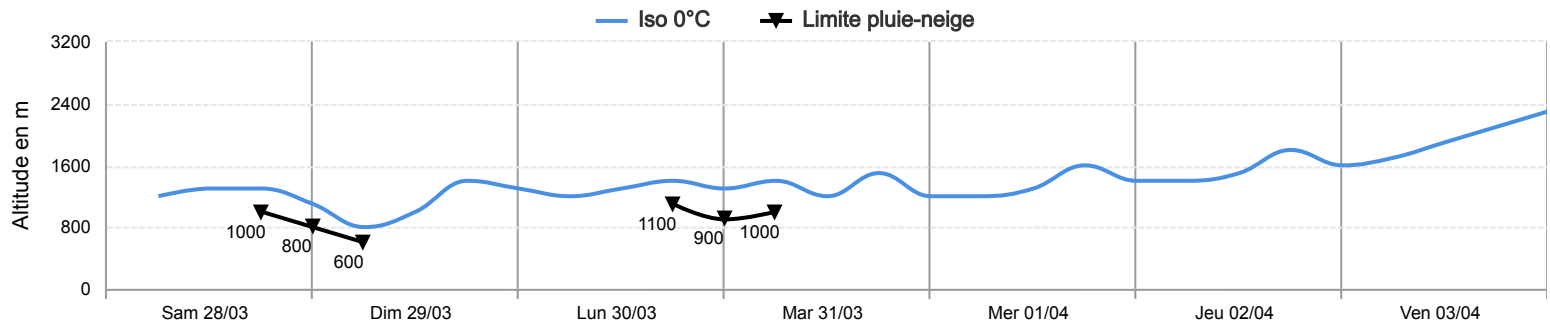


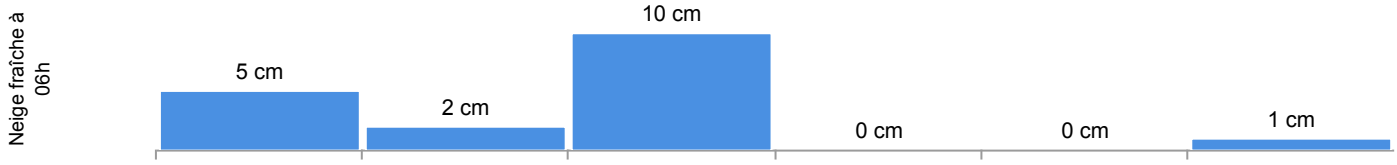


| Risque d'avalanche | sam. 28/03 | dim. 29/03 | lun. 30/03 | mar. 31/03 | mer. 01/04 | jeu. 02/04 | ven. 03/04 |
|---|---|---|---|---|---|---|---|
| | 3 | 2 | 2 | 3 | 3 | 2 | 2 |

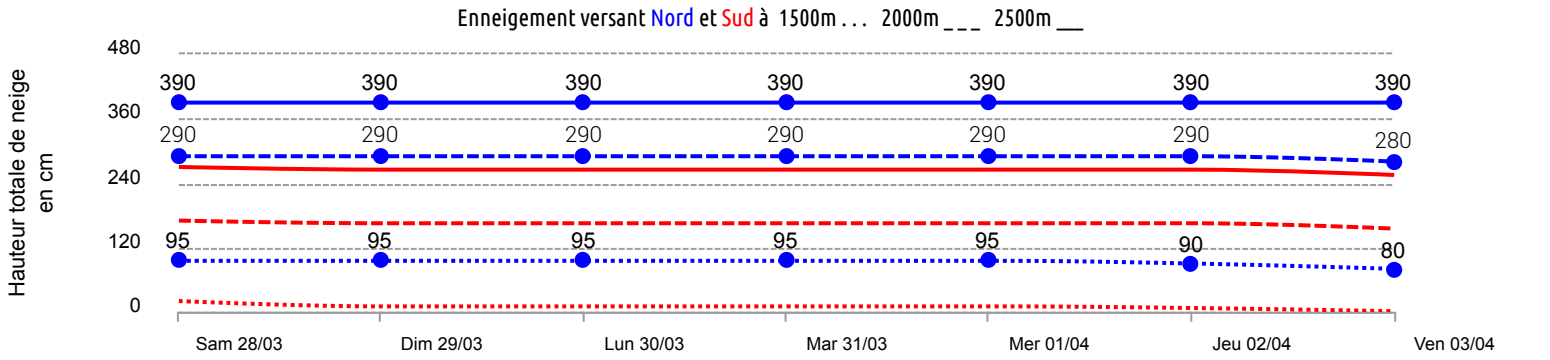


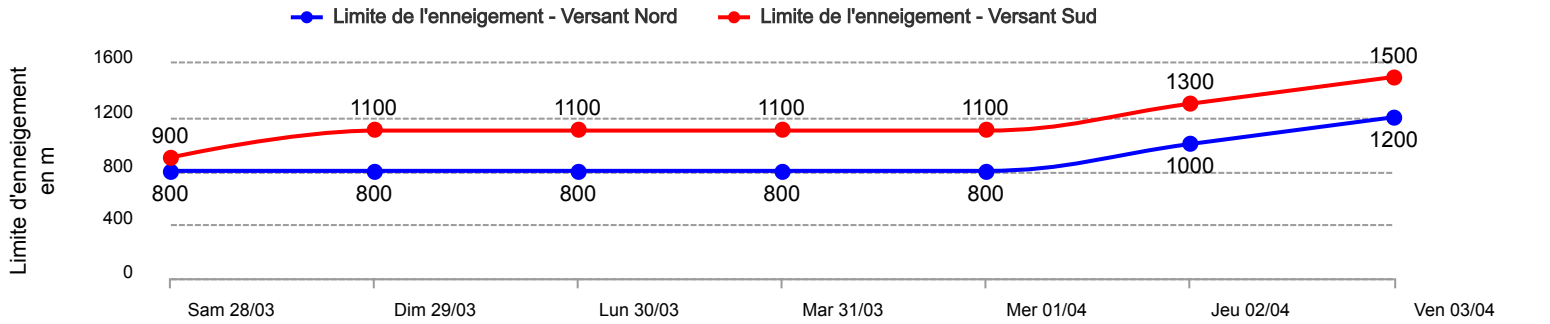


Pour consulter la vigilance en cours, veuillez vous rendre sur le site https://vigilance.meteofrance.fr/fr


Météo-France - 73 avenue de Paris, 94165 Saint-Mandé cedex - Contact : contact@meteo.fr


Bulletin neige & avalanches par téléphone au

0 892 68 10 20 Service 0,35 € / min + prix appel


Rédigé par Météo-France avec la contribution des observateurs du réseau nivo-météorologiques. Partenariat : ANMSM (Maires de Stations de Montagne), DSF (Domaines Skiables de France), ADSP (Directeurs de Pistes et de la Sécurité des Stations de Sports d'Hiver) et autres acteurs de la montagne.