Bulletin d'estimation du risque d'avalanche

(valable en dehors des pistes balisées et ouvertes)

MASSIF : Capcir Puymorens

Rédigé le vendredi 3 avril 2026 à 16h

Estimation des risques pour le : SAMEDI 04 AVRIL

STABILISATION PROGRESSIVE DANS LA NEIGE VENTÉE DES DERNIERS JOURS; NOUVELLE HUMIDIFICATION DANS LES VERSANTS AU SOLEIL.

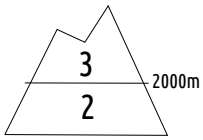

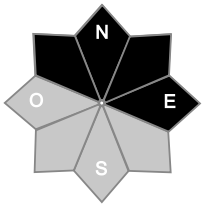

Au-dessus de 2000m indice de risque marqué, plus bas indice limité.

Départs spontanés : Départs d'avalanches dans les versants prenant le soleil au fil de la journée

Déclenchements provoqués : Avalanches de plaques encore déclenchables surtout dans les versants Nord-Ouest à Est d'altitude

Indices de risque : 5 très fort - 4 fort - 3 marqué - 2 limité - 1 faible -- En noir : les pentes les plus dangereuses

Stabilité du manteau neigeux

Situation avalancheuse typique : neige ventée neige humide

Des avalanches de plaques ont été observées ce vendredi dans la neige récente des versants Nord-Est au-dessus de 2000 m.

Déclenchements provoqués :

Stabilisation progressive des couches fragiles temporaires dans la neige récente, avec tout de même des avalanches de plaques de taille moyenne à grande, déclenchables dans les versants Nord-Ouest à Est d'altitude. En effet, au-dessus de 2000m, les structures de plaques, formées ces derniers jours, dans les 40 à 60 cm de neige ventée, sont encore réactives dans ces versants. Les accumulations sont plus dures et compactes proche des crêtes et sommets, mais peuvent aussi être d'aspect poudreux et parfois même loin des crêtes.

Sous 2000 m, un déclenchement par un skieur est peu probable ou alors plutôt un départ ponctuel dans la neige humide en coupant une pente raide déjà bien humidifiée.

Observables : Avalanches récentes, aspect ventée de la surface et accumulations locales, fissures éventuelles devant les skis.

Départs spontanés :

Des départs ponctuels d'avalanches de taille moyenne dans la neige récente sont attendus dans les pentes raides des versants ensoleillés (sous les rochers notamment). De rares départs linéaires de plus grande taille sont tout de même encore possibles en altitude, dans les pentes raides des versants Nord-Est à Sud, où les accumulations ont été les plus importantes.

Autre : Corniches volumineuses proches des crêtes avec les chutes de neige ventée des derniers jours.

Qualité de la neige

Enneigement :

L'enneigement est excellent cette année pour un début avril avec des cumuls conséquents en altitude malgré des crêtes et sommets exposés au vent d'ouest à nord-ouest souvent dégarnis. On peut toujours chausser les skis vers 1500 m sur la neige récente mais plutôt à partir de 1600/1700 m avec de la neige plus ancienne.

Qualité de la neige :

Samedi matin, le regel devrait être bon à partir de 1600/1800 m sauf aux endroits où les nuages tardent à se dissiper (proche de l'Ariège notamment). Plus bas, la neige sera humide dès le matin. En journée, l'humidification reprend en surface jusqu'en haut du massif en versant ensoleillés, et en tous versants jusqu'à 2000/2200 m avec de la neige humide en profondeur à basse altitude. Dans les zones ayant eu les plus gros cumuls de neige fraîche ces derniers jours, on trouvera des secteurs poudreux dans les versants ombragés à partir de 2100/2200m (Nord du Capcir, vallée du Galbe).

Aperçu météo pour le samedi 04 avril

nuit	matin	après-midi	soir

Belle journée après la dissipation rapide de quelques nuages bas en fin de nuit proche de l'Ariège. Douceur et vent en nette baisse.

Pluie-Neige				
Iso 0 °C	2 600 m	2 900 m	3 100 m	3 400 m
Vent 2000 m	40 km/h	30 km/h	10 km/h	5 km/h
Vent 3000 m	50 km/h	40 km/h	25 km/h	20 km/h

Épaisseur de neige hors-piste

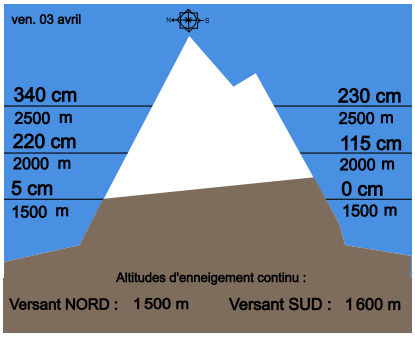

Précipitations à 1800 m

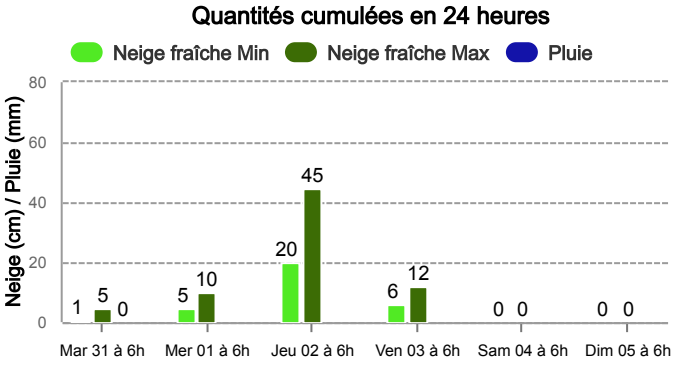

Tendance du dimanche 05 avril

Indice de risque limité

Tendance à la baisse avec la stabilisation de la neige des derniers jours.

Pour consulter la vigilance en cours, veuillez vous rendre sur le site https://vigilance.meteofrance.fr/fr

Météo-France - 73 avenue de Paris, 94165 Saint-Mandé cedex - Contact : contact@meteo.fr

Rédigé par Météo-France avec la contribution des observateurs du réseau nivo-météorologiques. Partenariat : ANMSM (Maires de Stations de Montagne), DSF (Domaines Skiables de France), ADSP (Directeurs de Pistes et de la Sécurité des Stations de Sports d'Hiver) et autres acteurs de la montagne.

Bulletin neige & avalanches par téléphone au 0 892 68 10 20 Service 0,35 € / min + prix appel

RÉPUBLIQUE FRANÇAISE
Liberté Égalité Fraternité

METEO FRANCE
À VOS CÔTÉS, DANS UN CLIMAT QUI CHANGE

Bulletin d'estimation du risque d'avalanche

(valable en dehors des pistes balisées et ouvertes)

MASSIF : Capcir Puymorens

Rédigé le vendredi 3 avril 2026 à 16h

Conditions nivo-météo des 7 derniers jours

	sam. 28/03				dim. 29/03				lun. 30/03				mar. 31/03				mer. 01/04				jeu. 02/04				ven. 03/04			
	03h	09h	15h	21h	03h	09h	15h	21h	03h	09h	15h	21h	03h	09h	15h	21h	03h	09h	15h	21h	03h	09h	15h	21h	03h	09h	15h	21h
Météo																												
Vent (km/h)	60	70	85	105	115	110	95	85	80	80	95	100	95	85	95	95	90	85	90	95	90	90	95	85	75	70	50	45
à 3000m																												
Vent (km/h)	45	60	60	80	90	90	80	65	70	70	80	85	80	80	80	80	80	75	85	85	75	75	80	75	60	55	40	35
à 2000m																												

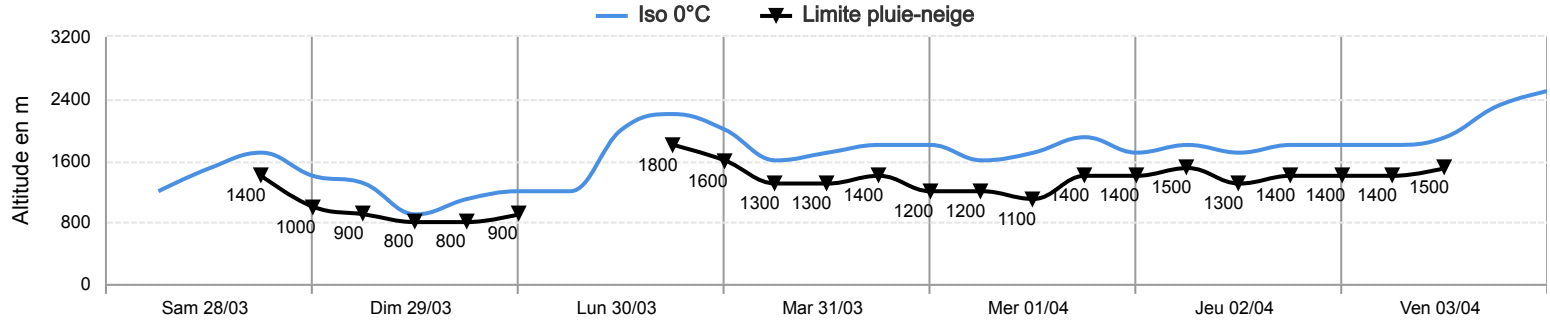

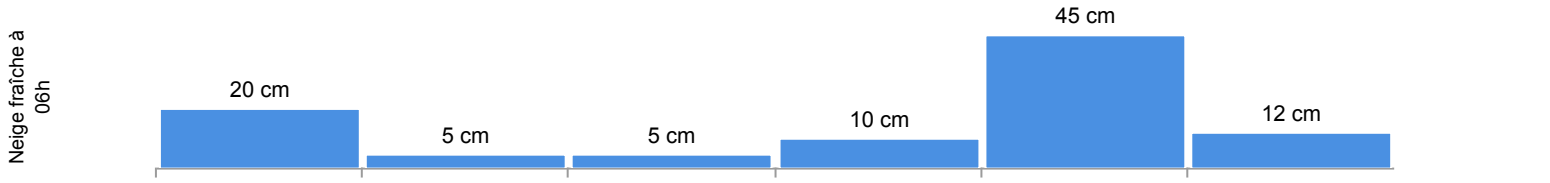

Risque d'avalanche	sam. 28/03	dim. 29/03	lun. 30/03	mar. 31/03	mer. 01/04	jeu. 02/04	ven. 03/04
	2	3	3	3	3	4	4

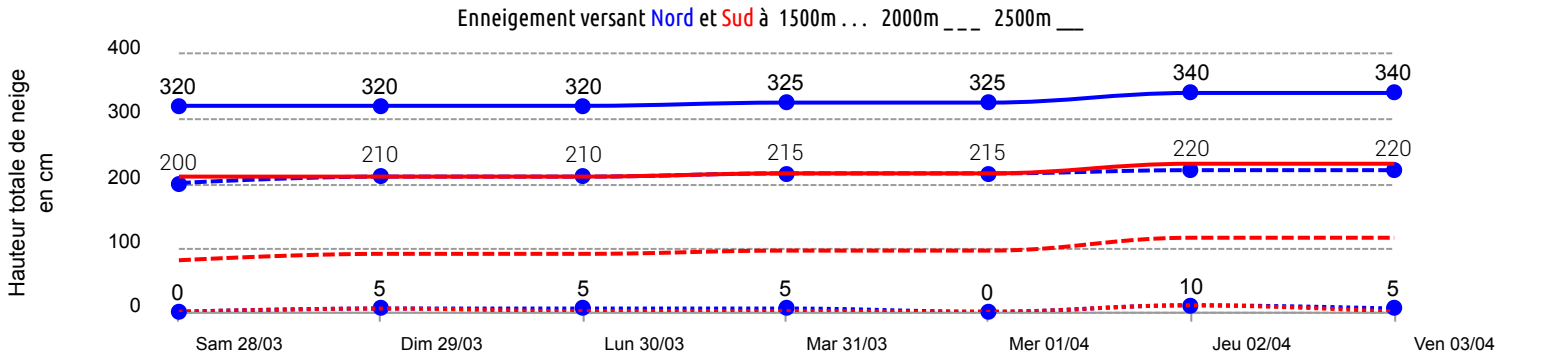

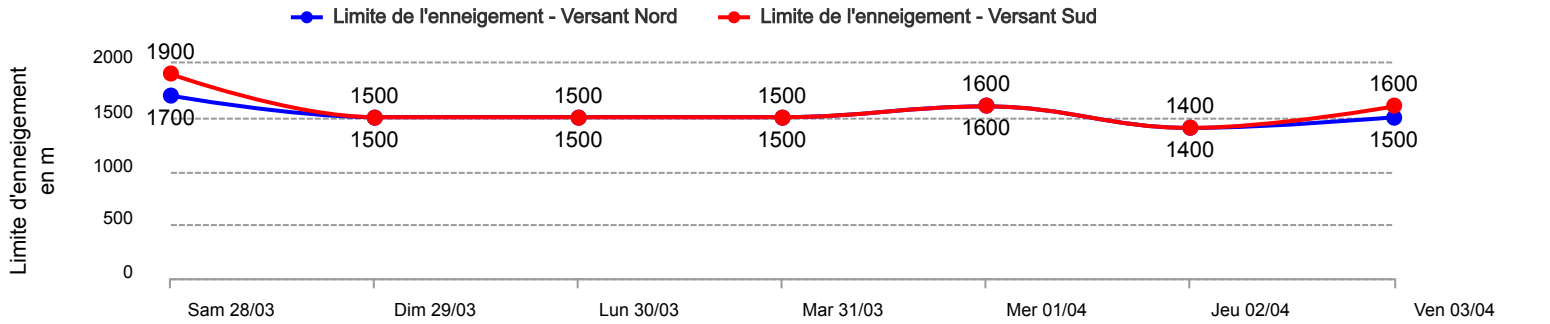

Pour consulter la vigilance en cours, veuillez vous rendre sur le site https://vigilance.meteofrance.fr/fr

Météo-France - 73 avenue de Paris, 94165 Saint-Mandé cedex - Contact : contact@meteo.fr

Rédigé par Météo-France avec la contribution des observateurs du réseau nivo-météorologiques. Partenariat : ANMSM (Maires de Stations de Montagne), DSF (Domaines Skiables de France), ADSP (Directeurs de Pistes et de la Sécurité des Stations de Sports d'Hiver) et autres acteurs de la montagne.

Bulletin neige & avalanches par téléphone au
0 892 68 10 20 Service 0,35 € / min + prix appel