Bulletin d'estimation du risque d'avalanche

(valable en dehors des pistes balisées et ouvertes)

MASSIF : Cerdagne Canigou

Rédigé le vendredi 3 avril 2026 à 16h

Estimation des risques pour le : SAMEDI 04 AVRIL

ENCORE QUELQUES STRUCTURES DE PLAQUES PRÉSENTES EN ALTITUDE ET HUMIDIFICATION QUI GAGNE EN PROFONDEUR.

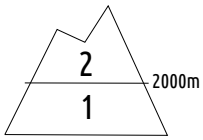

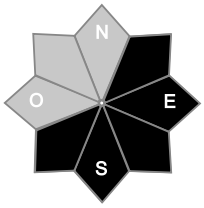

Au-dessus de 2000m indice de risque limité, plus bas indice faible.

Départs spontanés : Départs ponctuels en neige humide dans les pentes raides des versants ensoleillés

Déclenchements provoqués : Encore quelques structures de plaques en altitude dans la neige ventée récente

Indices de risque : 5 très fort - 4 fort - 3 marqué - 2 limité - 1 faible -- En noir : les pentes les plus dangereuses

Stabilité du manteau neigeux

Situation avalancheuse typique : neige ventée neige humide

Déclenchements provoqués :

Avalanches de plaques encore déclenchables par un pratiquant, dans les versants Nord-Ouest à Est au-dessus de 2000/2200 m. Ces avalanches seront de taille petite à moyenne, toutefois suffisante pour un ensevelissement. Ces instabilités dans la neige récente se sont formées avec les chutes de neige et le vent des derniers jours. Elles sont plutôt présentes du Canigou au Cambre d'Ase là où les derniers cumuls de neige ont été plus importants. Elles se trouvent parfois loin des crêtes avec un aspect poudreux dans des combes abritées et plus dure et compacte proche des crêtes et sommets.

Observables : neige fraîche, accumulations de neige ventée dans certaines pentes.

Départs spontanés :

Reprise de l'activité en neige humide en journée avec des départs ponctuels d'avalanche dans les versants ensoleillés de taille petite à moyenne, plutôt dans les versants Sud à Est où les accumulations des derniers jours ont été plus importantes.

Qualité de la neige

Enneigement :

L'enneigement est excellent cette année, dans les meilleurs des 20 dernières années, avec des cumuls conséquents en altitude malgré des crêtes et sommets exposés au vent de nord-ouest souvent dégarnis. On peut plutôt chausser sur une sous-couche de neige plus ancienne à partir de 1600/1700 m, parfois plus haut en sud.

Qualité de la neige :

Samedi matin, le regel devrait être bon à partir de 1800/1900 m sauf en forêt. Plus bas, la neige sera humide dès le matin.

En journée, l'humidification se fait en surface jusqu'en haut du massif en versant ensoleillés, et en tous versants jusqu'à 2200/2300 m avec de la neige humide en profondeur à basse altitude. On trouvera tout de même des secteurs poudreux avec la neige des derniers jours dans les versants ombragés à partir de 2200/2300m. En altitude, la neige est souvent bien travaillée par le vent avec de belles corniches et des zones hétérogènes et des crêtes pelées ou même glacées notamment vers le Puigmal.

Aperçu météo pour le samedi 04 avril

nuit	matin	après-midi	soir

Belle journée douce et bien ensoleillée. Vent qui faiblit au fil de la journée.

Pluie-Neige				
Iso 0 °C	2 600 m	3 000 m	3 100 m	3 400 m
Vent 2000 m	↘ 35 km/h	↓ 30 km/h	↙ 15 km/h	← 15 km/h
Vent 3000 m	↓ 55 km/h	↓ 40 km/h	↘ 30 km/h	→ 25 km/h

Épaisseur de neige hors-piste

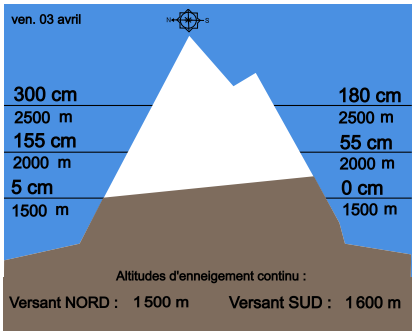

Précipitations à 1800 m

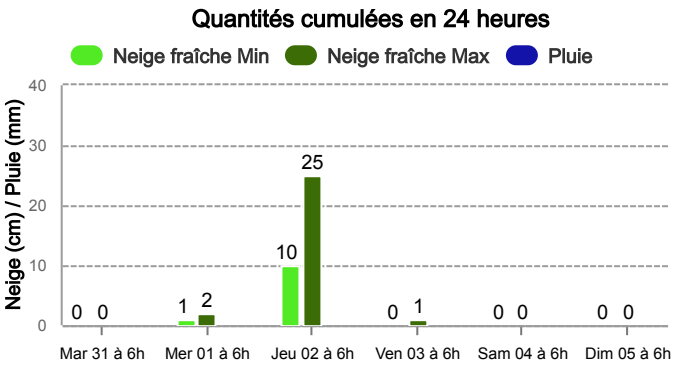

Tendance du dimanche 05 avril

Indice de risque limité

Stationnaire avec une reprise de l'activité en neige humide en journée.

Pour consulter la vigilance en cours, veuillez vous rendre sur le site https://vigilance.meteofrance.fr/fr

Météo-France - 73 avenue de Paris, 94165 Saint-Mandé cedex - Contact : contact@meteo.fr

Rédigé par Météo-France avec la contribution des observateurs du réseau nivo-météorologiques. Partenariat : ANMSM (Maires de Stations de Montagne), DSF (Domaines Skiables de France), ADSP (Directeurs de Pistes et de la Sécurité des Stations de Sports d'Hiver) et autres acteurs de la montagne.

Bulletin neige & avalanches par téléphone au 0 892 68 10 20 Service 0,35 € / min + prix appel

RÉPUBLIQUE FRANÇAISE
Liberté Égalité Fraternité

METEO FRANCE
À VOS CÔTÉS, DANS UN CLIMAT QUI CHANGE

Bulletin d'estimation du risque d'avalanche

(valable en dehors des pistes balisées et ouvertes)

MASSIF : Cerdagne Canigou

Rédigé le vendredi 3 avril 2026 à 16h

Conditions nivo-météo des 7 derniers jours

	sam. 28/03				dim. 29/03				lun. 30/03				mar. 31/03				mer. 01/04				jeu. 02/04				ven. 03/04			
	03h	09h	15h	21h	03h	09h	15h	21h	03h	09h	15h	21h	03h	09h	15h	21h	03h	09h	15h	21h	03h	09h	15h	21h	03h	09h	15h	21h
Météo																												
Vent (km/h)	75	70	80	105	120	110	90	90	90	85	90	100	105	90	100	105	100	90	95	100	100	95	95	90	85	75	55	50
à 3000m																												
Vent (km/h)	60	50	60	80	95	85	65	70	60	60	70	75	65	65	70	75	70	70	75	80	70	65	70	70	60	55	40	35
à 2000m																												

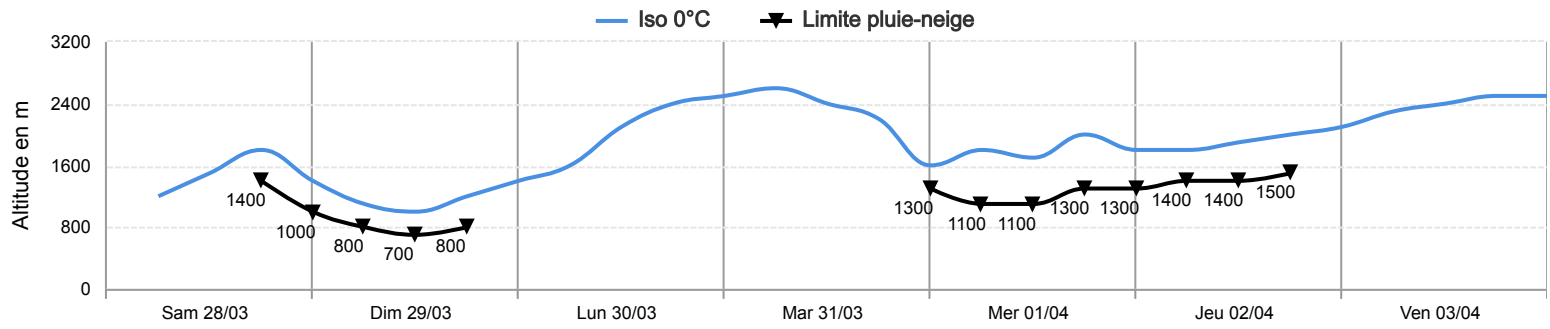

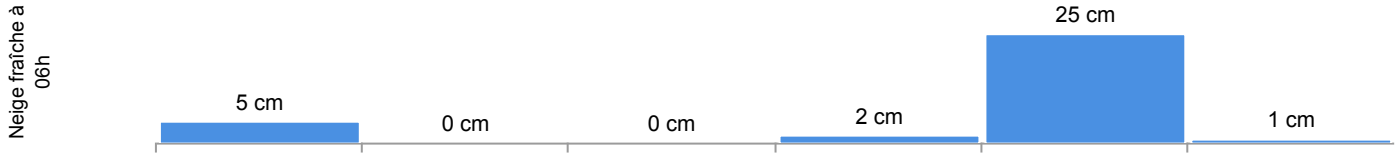

Risque d'avalanche	sam. 28/03	dim. 29/03	lun. 30/03	mar. 31/03	mer. 01/04	jeu. 02/04	ven. 03/04
	2	2	2	2	2	2	2

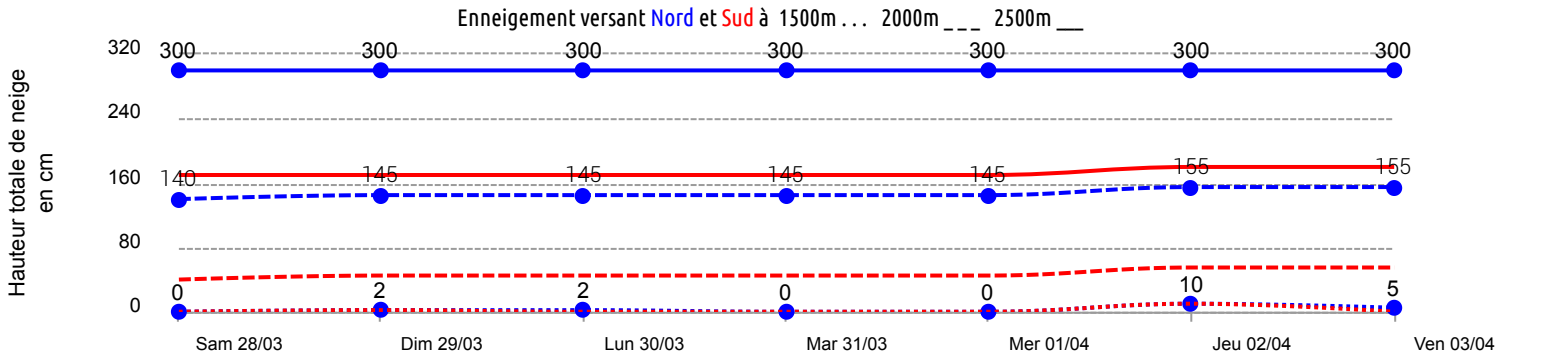

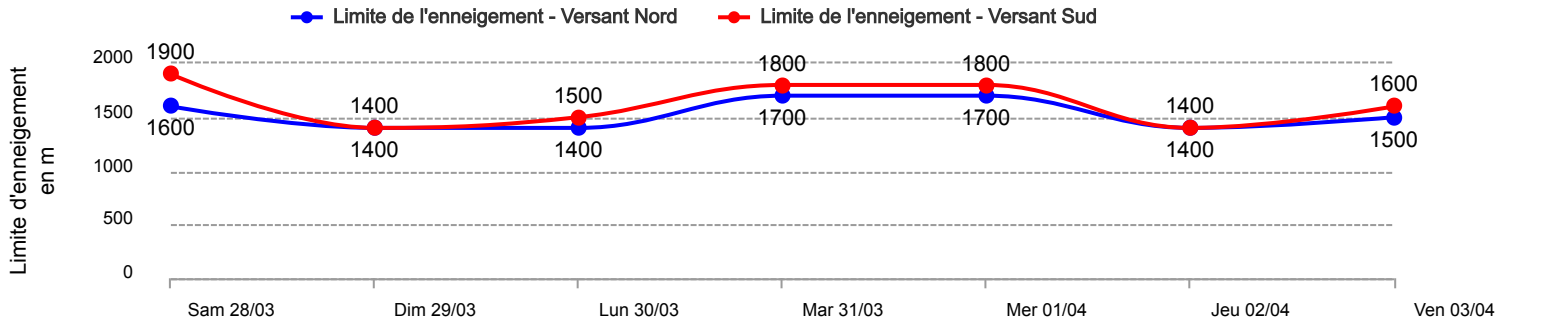

Pour consulter la vigilance en cours, veuillez vous rendre sur le site https://vigilance.meteofrance.fr/fr

Météo-France - 73 avenue de Paris, 94165 Saint-Mandé cedex - Contact : contact@meteo.fr

Rédigé par Météo-France avec la contribution des observateurs du réseau nivo-météorologiques. Partenariat : ANMSM (Maires de Stations de Montagne), DSF (Domaines Skiables de France), ADSP (Directeurs de Pistes et de la Sécurité des Stations de Sports d'Hiver) et autres acteurs de la montagne.

Bulletin neige & avalanches par téléphone au
0 892 68 10 20 Service 0,35 € / min + prix appel