Bulletin d'estimation du risque d'avalanche

(valable en dehors des pistes balisées et ouvertes)

MASSIF : Couserans

Rédigé le vendredi 3 avril 2026 à 16h

Estimation des risques pour le : SAMEDI 04 AVRIL

STABILISATION PROGRESSIVE DANS LA NEIGE DES DERNIERS JOURS; HUMIDIFICATION DANS LES VERSANTS AU SOLEIL.

3

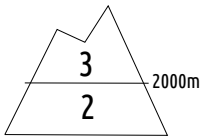

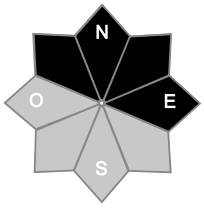

Au-dessus de 2000m indice de risque marqué, plus bas indice limité.

Départs spontanés : Départs d'avalanches dans les versants prenant le soleil au fil de la journée

Déclenchements provoqués : Avalanches de plaques encore déclenchables plutôt dans les versants Nord-Ouest à Est d'altitude

Indices de risque : 5 très fort - 4 fort - 3 marqué - 2 limité - 1 faible -- En noir : les pentes les plus dangereuses

Stabilité du manteau neigeux

Situation avalancheuse typique : neige ventée neige humide

Déclenchements provoqués :
Stabilisation progressive des couches fragiles temporaires dans la neige récente, avec tout de même des avalanches de plaques de taille moyenne, à rarement grande, déclenchables dans les versants Nord-Ouest à Est d'altitude. En effet, au-dessus de 2000m, les structures de plaques, formées ces derniers jours, sont encore réactives dans ces versants. Les accumulations sont plus dures et compactes proche des crêtes et sommets, mais aussi d'aspect poudreux et parfois même loin des crêtes.
Sous 2000 m, un déclenchement par un skieur est peu probable ou alors plutôt un départ ponctuel dans la neige humide en coupant une pente raide déjà bien humidifiée.
Observables : Avalanches récentes, aspect ventée de la surface et accumulations locales, fissures éventuelles devant les skis.

Départs spontanés :
Des départs ponctuels d'avalanches de taille moyenne dans la neige récente sont attendus dans les pentes raides des versants ensoleillés (sous les rochers notamment). De rares départs linéaires de plus grande taille sont tout de même encore possibles en altitude, dans les pentes raides des versants Nord-Est à Sud, où les accumulations ont été les plus importantes.

Autre : Corniches volumineuses proches des crêtes avec les chutes de neige ventée des derniers jours.

Qualité de la neige

Enneigement :
L'enneigement est vraiment très bon pour la saison avec des cumuls conséquents en altitude mais des crêtes et sommets exposés au vent d'ouest à nord-ouest souvent assez dégarnis. Même si la neige est visible dès 1300 m dans certains secteurs ombragés et en fond de vallée, il est envisageable de chausser les skis plutôt à partir de 1400/1600 m sur une couche de neige plus épaisse.

Qualité de la neige :
Samedi matin, regel plus ou moins efficace sous 2000m avec des nuages qui restent présents une bonne partie de la nuit prochaine et des éclaircies qui ne se font qu'en deuxième partie de nuit. Au-dessus, bon regel en sud, et neige certainement encore légère et poudreuse dans les combes abritées en nord, plus dure et tassée là où le vent a soufflé.
En journée, l'humidification reprend plutôt en surface jusqu'en haut du massif en versant sud, et en toutes orientations jusqu'à 2000/2100 m avec de la neige humide en profondeur et gorgée d'eau au soleil.

Aperçu météo pour le samedi 04 avril

nuit	matin	après-midi	soir

Le soleil revient dès samedi matin après la dissipation des nuages bas présents la nuit prochaine.
Vent faible et douceur en journée.

Pluie-Neige				
Iso 0 °C	2 400 m	3 000 m	3 200 m	3 300 m
Vent 2000 m	↓ 20 km/h	↙ 15 km/h	↙ 15 km/h	↙ 15 km/h
Vent 3000 m	↓ 40 km/h	↓ 35 km/h	↓ 25 km/h	→ 20 km/h

Épaisseur de neige hors-piste

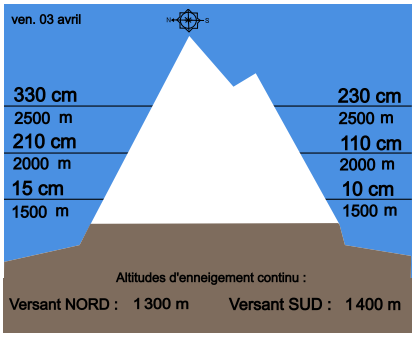

Précipitations à 1800 m

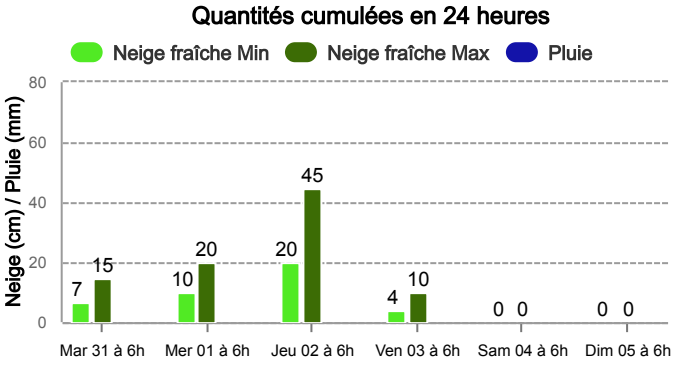

Tendance du dimanche 05 avril

2

Indice de risque limité

Tendance à la baisse avec la poursuite de la stabilisation.

Pour consulter la vigilance en cours, veuillez vous rendre sur le site https://vigilance.meteofrance.fr/fr

Météo-France - 73 avenue de Paris, 94165 Saint-Mandé cedex - Contact : contact@meteo.fr

Rédigé par Météo-France avec la contribution des observateurs du réseau nivo-météorologiques. Partenariat : ANMSM (Maires de Stations de Montagne), DSF (Domaines Skiables de France), ADSP (Directeurs de Pistes et de la Sécurité des Stations de Sports d'Hiver) et autres acteurs de la montagne.

Bulletin neige & avalanches par téléphone au **0 892 68 10 20** Service 0,35 € / min + prix appel

RÉPUBLIQUE FRANÇAISE
Liberté Égalité Fraternité

METEO FRANCE
À VOS CÔTÉS, DANS UN CLIMAT QUI CHANGE

Bulletin d'estimation du risque d'avalanche

(valable en dehors des pistes balisées et ouvertes)

MASSIF : Couserans

Rédigé le vendredi 3 avril 2026 à 16h

Conditions nivo-météo des 7 derniers jours

	sam. 28/03				dim. 29/03				lun. 30/03				mar. 31/03				mer. 01/04				jeu. 02/04				ven. 03/04			
	03h	09h	15h	21h	03h	09h	15h	21h	03h	09h	15h	21h	03h	09h	15h	21h	03h	09h	15h	21h	03h	09h	15h	21h	03h	09h	15h	21h
Météo																												
Vent (km/h)	40	45	70	85	110	100	90	70	65	55	60	70	60	60	70	75	75	75	80	85	80	70	70	70	60	50	45	40
à 3000m																												
Vent (km/h)	20	20	30	60	85	65	50	40	35	25	40	45	45	35	40	45	45	45	55	65	55	45	50	50	35	20	20	20
à 2000m																												

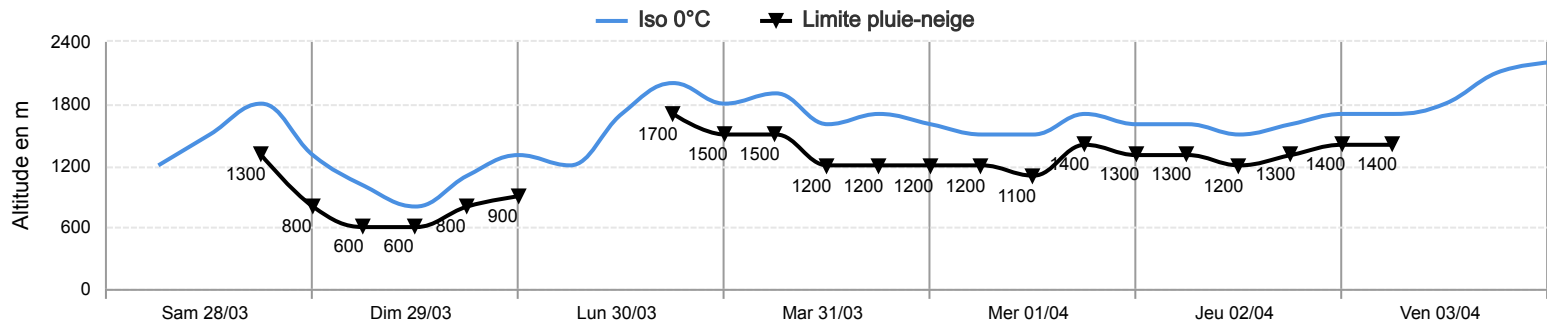

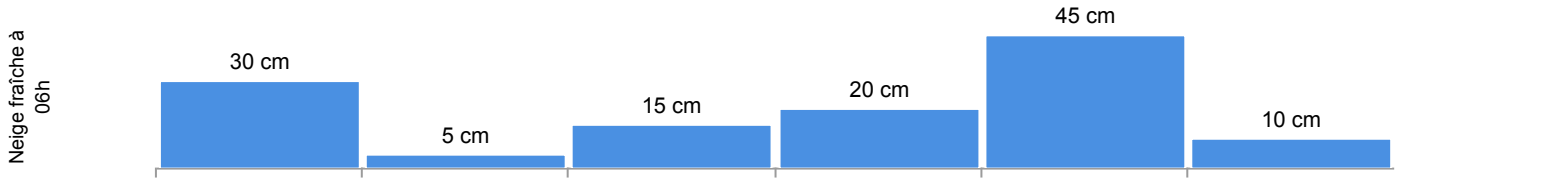

Risque d'avalanche	sam. 28/03	dim. 29/03	lun. 30/03	mar. 31/03	mer. 01/04	jeu. 02/04	ven. 03/04
	2	3	3	3	4	4	4

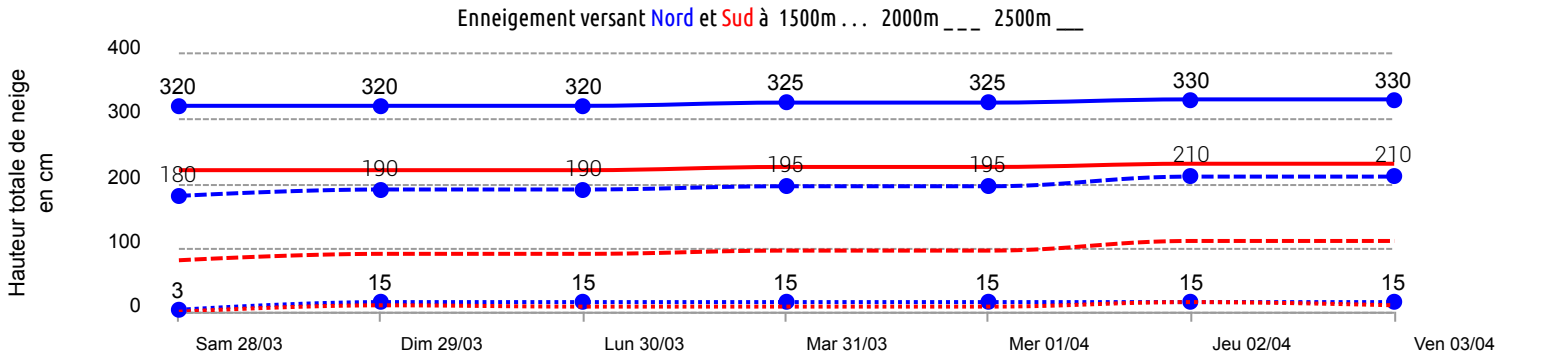

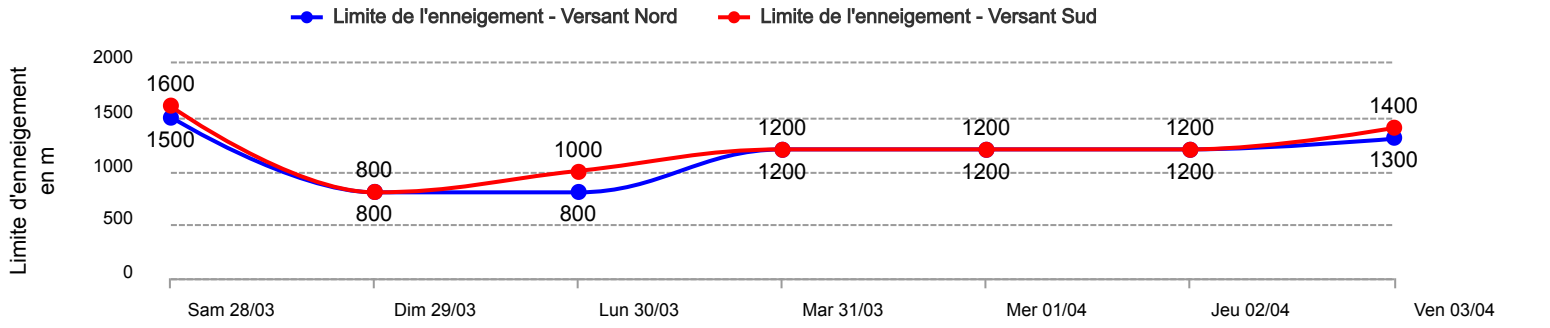

Pour consulter la vigilance en cours, veuillez vous rendre sur le site https://vigilance.meteofrance.fr/fr

Météo-France - 73 avenue de Paris, 94165 Saint-Mandé cedex - Contact : contact@meteo.fr

Rédigé par Météo-France avec la contribution des observateurs du réseau nivo-météorologiques. Partenariat : ANMSM (Maires de Stations de Montagne), DSF (Domaines Skiables de France), ADSP (Directeurs de Pistes et de la Sécurité des Stations de Sports d'Hiver) et autres acteurs de la montagne.

Bulletin neige & avalanches par téléphone au
0 892 68 10 20 Service 0,35 € / min + prix appel