RÉPUBLIQUE FRANÇAISE
Liberté Égalité Fraternité

METEO FRANCE
À VOS CÔTÉS, DANS UN CLIMAT QUI CHANGE

Bulletin d'estimation du risque d'avalanche
(valable en dehors des pistes balisées et ouvertes)
MASSIF : Embrunais Parpaillon

Rédigé le vendredi 3 avril 2026 à 16h

Estimation des risques pour le : SAMEDI 04 AVRIL

MANTEAU NEIGEUX GÉNÉRALEMENT STABILISÉ

2

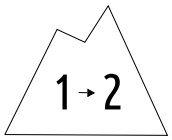

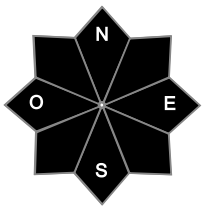

Indice de risque faible évoluant en limité.

Départs spontanés : quelques départs ponctuels, plus rarement linéaires, en neige humide

Déclenchements provoqués : rares plaques résiduelles en neige sèche en altitude

Indices de risque : 5 très fort - 4 fort - 3 marqué - 2 limité - 1 faible -- En noir : les pentes les plus dangereuses

Stabilité du manteau neigeux

Situation avalancheuse typique : neige humide

Départs spontanés : peu probables en début de journée après un bon regel nocturne, puis possibles départs de neige humide en pentes raides au soleil. Départs ponctuels en poire, plus rarement linéaires. Petite taille, moyenne non exclue.

Déclenchements provoqués : rares plaques résiduelles dans quelques pentes d'altitude au-dessus de 2200 m environ, plutôt en large secteur nord, généralement loin des crêtes. Elles sont le plus souvent d'aspect durci par le vent, et bien identifiables. Déclenchement encore possible par un skieur, engendrant une avalanche peu étendue de taille petite à parfois moyenne.
Par ailleurs, un skieur, évoluant tardivement en pentes raides ensoleillées, peut provoquer un départ ponctuel en neige humide sous les skis.

Qualité de la neige

L'enneigement est proche des normales pour un début avril.
Hauteurs de neige observées : 102 cm à la nivôse du Parpaillon à 2500 m.

Limite d'enneigement skiable : au plus bas à 1500 m en ubacs bien protégés ou sur pistes forestières, plutôt 2000/2100 m en adrets.

État de la neige de surface : en adrets, manteau printanier, dur/ regelé, s'humidifiant en journée. En ubacs sous 2000/2200 m neige souvent croutée, plus haut neige durcie, travaillée par le vent, encore localement légère dans des secteurs bien abrités. Sur les crêtes, d'épaisses corniches côtoient des zones pelées par le vent.

Aperçu météo pour le samedi 04 avril

	nuit	matin	après-midi	soir
Soleil et douceur marquée				
Pluie-Neige				
Iso 0 °C	2 800 m	3 000 m	3 000 m	3 200 m
Vent 2000 m	↘ 10 km/h	↖ 10 km/h	↗ 15 km/h	↖ 10 km/h
Vent 3000 m	↓ 20 km/h	↓ 20 km/h	↓ 10 km/h	↙ 10 km/h

Épaisseur de neige hors-piste

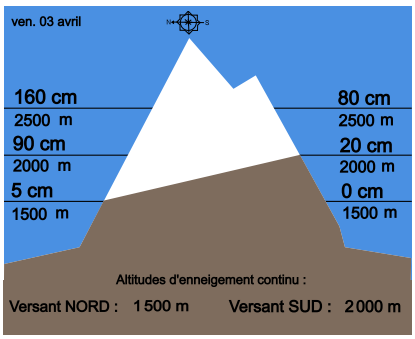

Précipitations à 1800 m

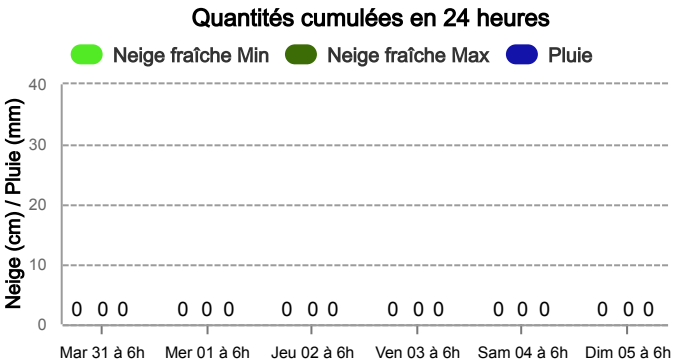

Tendance du dimanche 05 avril

2

Indice de risque limité

Risque limité. Plaques résiduelles en ubac d'altitude et activité naturelle en neige humide.

Pour consulter la vigilance en cours, veuillez vous rendre sur le site https://vigilance.meteofrance.fr/fr

Météo-France - 73 avenue de Paris, 94165 Saint-Mandé cedex - Contact : contact@meteo.fr

Rédigé par Météo-France avec la contribution des observateurs du réseau nivo-météorologiques. Partenariat : ANMSM (Maires de Stations de Montagne), DSF (Domaines Skiables de France), ADSP (Directeurs de Pistes et de la Sécurité des Stations de Sports d'Hiver) et autres acteurs de la montagne.

Bulletin neige & avalanches par téléphone au
0 892 68 10 20 Service 0,35 € / min + prix appel

RÉPUBLIQUE FRANÇAISE
Liberté Égalité Fraternité

METEO FRANCE
À VOS CÔTÉS, DANS UN CLIMAT QUI CHANGE

Bulletin d'estimation du risque d'avalanche
(valable en dehors des pistes balisées et ouvertes)
MASSIF : Embrunais Parpaillon

Rédigé le vendredi 3 avril 2026 à 16h

Conditions nivo-météo des 7 derniers jours

	sam. 28/03				dim. 29/03				lun. 30/03				mar. 31/03				mer. 01/04				jeu. 02/04				ven. 03/04			
	03h	09h	15h	21h	03h	09h	15h	21h	03h	09h	15h	21h	03h	09h	15h	21h	03h	09h	15h	21h	03h	09h	15h	21h	03h	09h	15h	21h
Météo																												
Vent (km/h)	30	25	30	25	25	40	25	20	30	50	80	90	80	70	60	45	40	40	50	50	50	30	25	15	25	40	30	30
à 3000m																												
Vent (km/h)	10	10	20	20	20	30	25	15	10	20	50	70	70	60	45	30	25	25	35	35	25	15	25	15	15	15	15	10
à 2000m																												

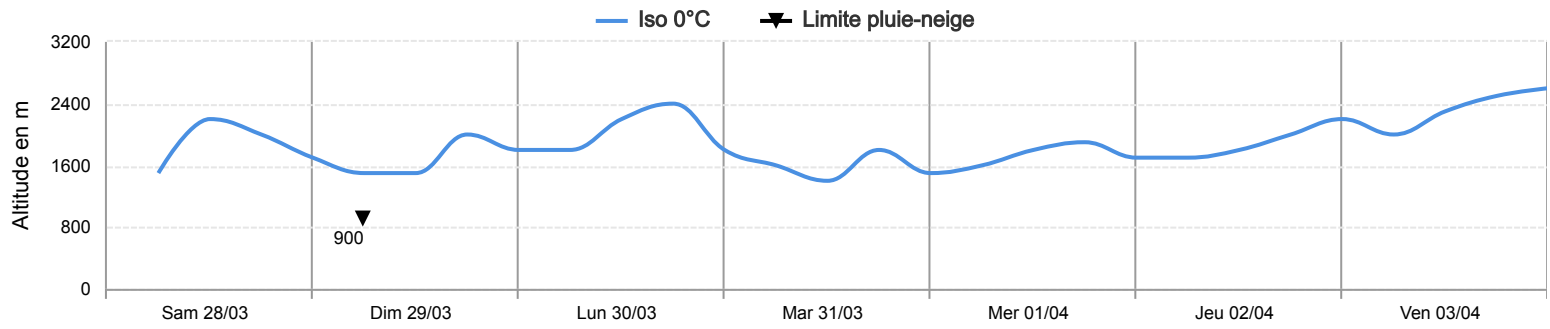

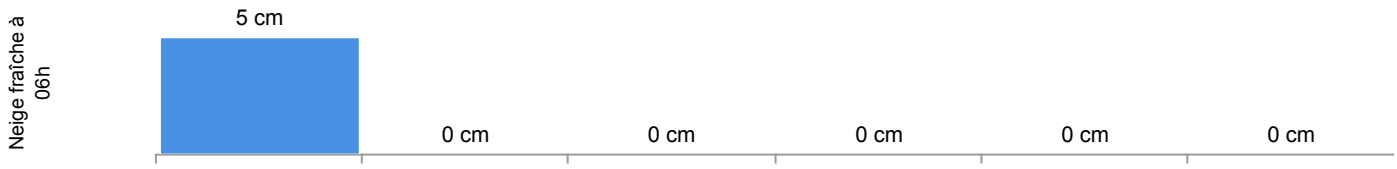

Risque d'avalanche	sam. 28/03	dim. 29/03	lun. 30/03	mar. 31/03	mer. 01/04	jeu. 02/04	ven. 03/04
	2	2	2	2	2	2	1

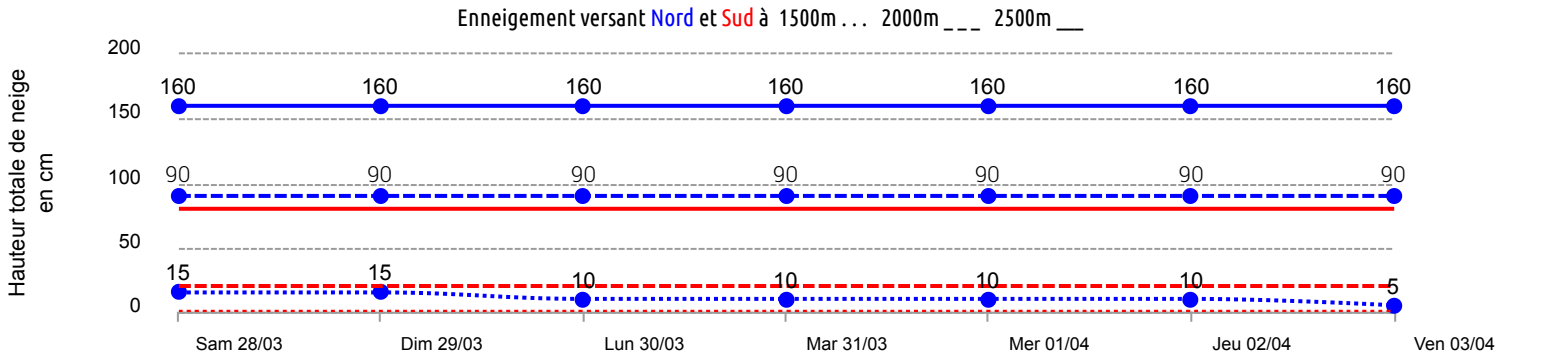

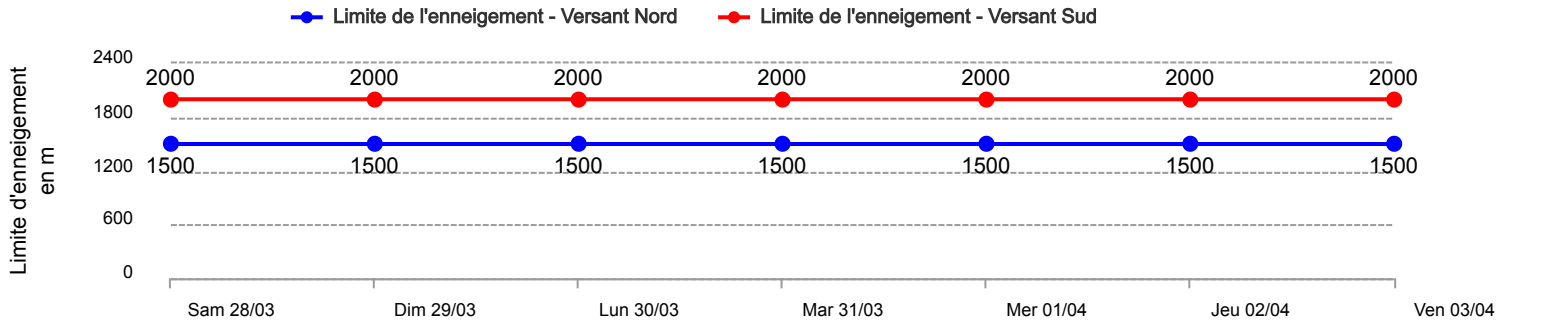

Pour consulter la vigilance en cours, veuillez vous rendre sur le site https://vigilance.meteofrance.fr/fr

Météo-France - 73 avenue de Paris, 94165 Saint-Mandé cedex - Contact : contact@meteo.fr

Rédigé par Météo-France avec la contribution des observateurs du réseau nivo-météorologiques. Partenariat : ANMSM (Maires de Stations de Montagne), DSF (Domaines Skiables de France), ADSP (Directeurs de Pistes et de la Sécurité des Stations de Sports d'Hiver) et autres acteurs de la montagne.

Bulletin neige & avalanches par téléphone au
0 892 68 10 20 Service 0,35 € / min + prix appel