Bulletin d'estimation du risque d'avalanche
(valable en dehors des pistes balisées et ouvertes)

MASSIF : Haute-Maurienne

Rédigé le vendredi 3 avril 2026 à 16h

Estimation des risques pour le : SAMEDI 04 AVRIL

GRANDE DOUCEUR : ÉVOLUTION RAPIDE VERS UN MANTEAU PRINTANIER.
ENCORE QUELQUES INSTABILITÉS EN NEIGE FROIDE EN NORD.

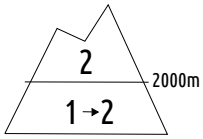

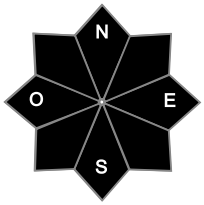

Au-dessus de 2000m indice de risque limité, plus bas indice faible évoluant en limité.

Départs spontanés : nombreux petits départs en neige humide au fil de la journée.

Déclenchements provoqués : quelques plaques en neige ventée dans les versants froids.

Indices de risque : 5 très fort - 4 fort - 3 marqué - 2 limité - 1 faible -- En noir : les pentes les plus dangereuses

Stabilité du manteau neigeux

Situation avalancheuse typique : neige humide neige ventée

Départs spontanés : nombreux départs en neige humide dans les versants ensoleillés, au fil de la journée. Généralement des petites avalanches, mais quelques tailles moyennes sont aussi attendues (notamment couloirs et pentes raides qui se "purgent"). Attention car à cette période de l'année le soleil commence à être haut et atteint aussi les pentes NE/NO.

Déclenchements provoqués : il subsiste de **quelques plaques en neige ventée dans les versants Nord/ au-dessus de 2000/2200 m**. Elles sont encore localement réactives, notamment dans les zones d'accumulation en pente raide. Ces plaques sont constituées d'une neige fortement densifiée voire durcie par le vent en surface, ce qui permet dans la plupart des cas de les identifier. **Cassures modestes, 20 à 50 cm** donnant des avalanches petites à moyennes. A noter que dans les secteurs très ventés, lorsque l'ancienne neige (souvent dure/croutée) ré-apparaît en surface, le risque est bien moindre (et le ski moins bon...).
Observables : test du bâton, fissures sous les skis.

Qualité de la neige

Enneigement : un peu au dessus de la moyenne, mais les prochains jours de chaleur vont bien attaquer le manteau.

Limite skiable : vers 1300 m en Nord, 1600 m en Sud.

Qualité de la neige : encore une neige froide dans les versants Nord, dès 2000/2200 m, avec une poudre tassée agréable sauf dans les secteurs ayant subi la bise et alors parfois très hétérogènes (croupes/crêtes pelées).
Dans tous les autres versants, manteau en cours de "printanisation" : neige n'ayant pas encore subi suffisamment de cycles gel/dégel pour assurer une portance dans tous les secteurs au matin (sauf en Sud où ça devrait déjà être bon jusqu'à ~2500 m). Puis bottage/collante l'après-midi :-(

Aperçu météo pour le samedi 04 avril

nuit	matin	après-midi	soir

Redoux marqué sous une magnifique journée très ensoleillée. Vent faible.

Pluie-Neige				
Iso 0 °C	2 400 m	2 800 m	3 000 m	3 100 m
Vent 2500 m	↓ 15 km/h	→ 10 km/h	→ 10 km/h	↖ 10 km/h
Vent 3500 m	↓ 25 km/h	↓ 20 km/h	↓ 15 km/h	↓ 15 km/h

Épaisseur de neige hors-piste

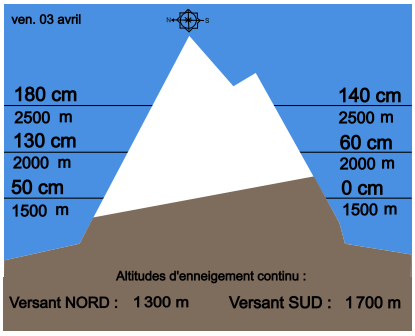

Précipitations à 1800 m

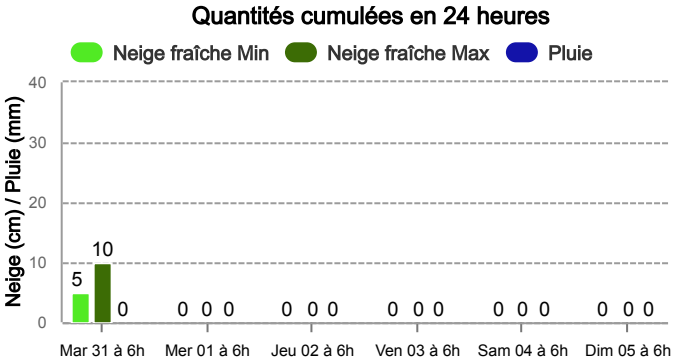

Tendance du dimanche 05 avril

Indice de risque limité

Évolution rapide vers une situation de neige humide printanière avec un risque faible le matin, devenant limité en journée. Les rares plaques en neige froide deviennent anecdotiques.

Pour consulter la vigilance en cours, veuillez vous rendre sur le site https://vigilance.meteofrance.fr/fr

Météo-France - 73 avenue de Paris, 94165 Saint-Mandé cedex - Contact : contact@meteo.fr

Rédigé par Météo-France avec la contribution des observateurs du réseau nivo-météorologiques. Partenariat : ANMSM (Maires de Stations de Montagne), DSF (Domaines Skiables de France), ADSP (Directeurs de Pistes et de la Sécurité des Stations de Sports d'Hiver) et autres acteurs de la montagne.

Bulletin neige & avalanches par téléphone au
0 892 68 10 20 Service 0,35 € / min + prix appel

RÉPUBLIQUE FRANÇAISE
Liberté Égalité Fraternité

METEO FRANCE
À VOS CÔTÉS, DANS UN CLIMAT QUI CHANGE

Bulletin d'estimation du risque d'avalanche
(valable en dehors des pistes balisées et ouvertes)
MASSIF : Haute-Maurienne

Rédigé le vendredi 3 avril 2026 à 16h

Conditions nivo-météo des 7 derniers jours

	sam. 28/03				dim. 29/03				lun. 30/03				mar. 31/03				mer. 01/04				jeu. 02/04				ven. 03/04			
	03h	09h	15h	21h	03h	09h	15h	21h	03h	09h	15h	21h	03h	09h	15h	21h	03h	09h	15h	21h	03h	09h	15h	21h	03h	09h	15h	21h
Météo																												
Vent (km/h)	30	40	40	30	30	30	30	30	50	95	105	75	60	50	50	50	45	25	25	30	30	35	35	35	30	30	30	25
à 3500m																												
Vent (km/h)	20	30	30	20	20	20	20	20	20	55	70	35	25	30	35	35	25	20	20	20	20	25	25	25	20	20	20	15
à 2500m																												

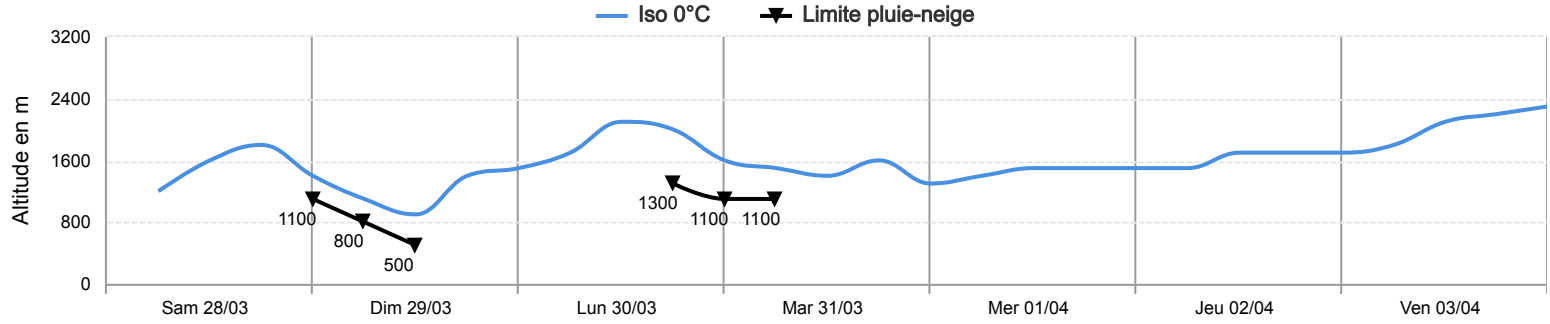

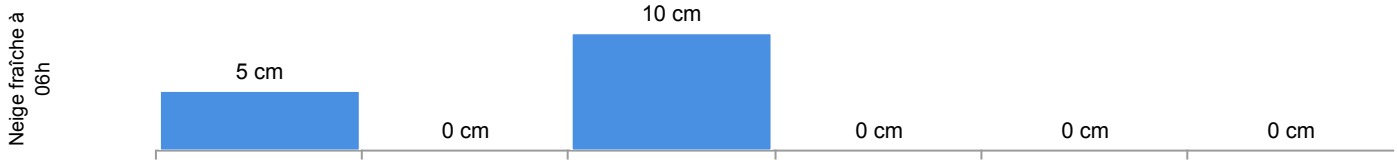

Risque d'avalanche	sam. 28/03	dim. 29/03	lun. 30/03	mar. 31/03	mer. 01/04	jeu. 02/04	ven. 03/04
	2	2	2	3	3	3	2

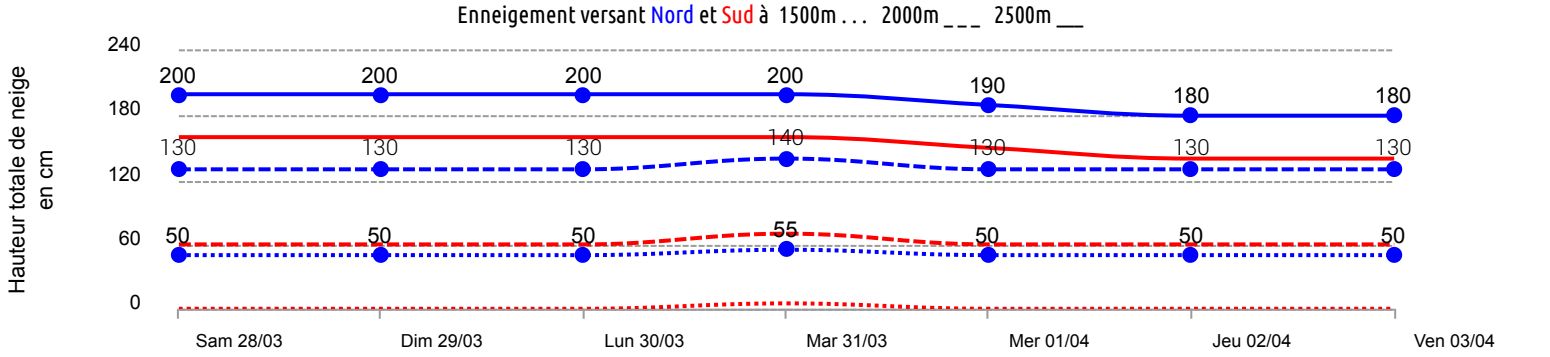

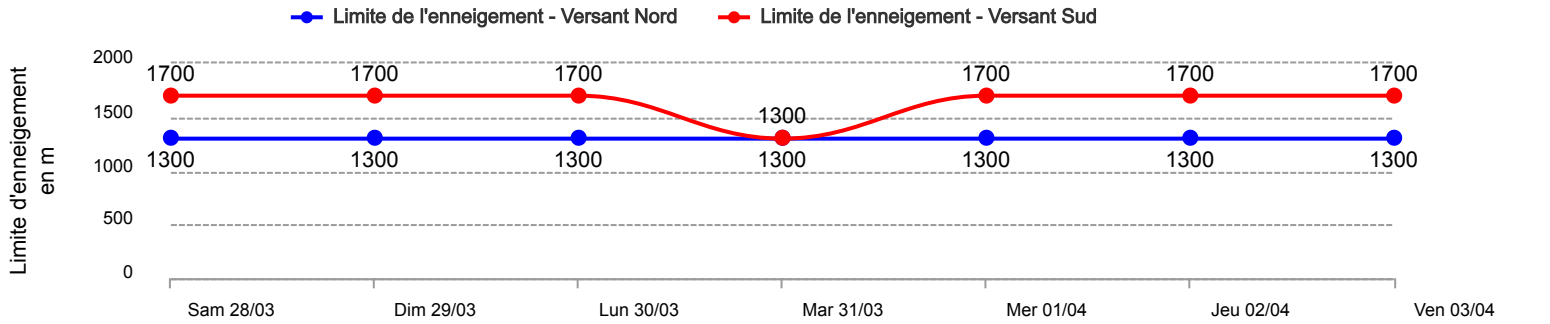

Pour consulter la vigilance en cours, veuillez vous rendre sur le site https://vigilance.meteofrance.fr/fr

Météo-France - 73 avenue de Paris, 94165 Saint-Mandé cedex - Contact : contact@meteo.fr

Rédigé par Météo-France avec la contribution des observateurs du réseau nivo-météorologiques. Partenariat : ANMSM (Maires de Stations de Montagne), DSF (Domaines Skiables de France), ADSP (Directeurs de Pistes et de la Sécurité des Stations de Sports d'Hiver) et autres acteurs de la montagne.

Bulletin neige & avalanches par téléphone au
0 892 68 10 20 Service 0,35 € / min + prix appel