Bulletin d'estimation du risque d'avalanche

(valable en dehors des pistes balisées et ouvertes)

MASSIF : Haute-Tarentaise

Rédigé le vendredi 3 avril 2026 à 16h

Estimation des risques pour le : SAMEDI 04 AVRIL

GRANDE DOUCEUR : ÉVOLUTION RAPIDE VERS UN MANTEAU PRINTANIER. RARES INSTABILITÉS EN NEIGE FROIDE EN NORD.

2

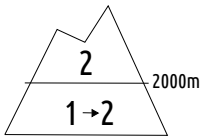

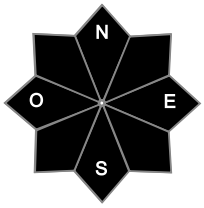

Au-dessus de 2000m indice de risque limité, plus bas indice faible évoluant en limité.

Départs spontanés : nombreux petits départs en neige humide au fil de la journée.

Déclenchements provoqués : rares plaques en neige ventée dans les versants froids.

Indices de risque : 5 très fort - 4 fort - 3 marqué - 2 limité - 1 faible -- En noir : les pentes les plus dangereuses

Stabilité du manteau neigeux

Situation avalancheuse typique : neige humide neige ventée

Départs spontanés : nombreux départs en neige humide dans les versants ensoleillés, au fil de la journée. Généralement des petites avalanches, mais quelques tailles moyennes sont aussi attendues (notamment couloirs et pentes raides qui se "purgent"). Attention car à cette période de l'année le soleil commence à être haut et atteint aussi les pentes NE/NO.

Déclenchements provoqués : il subsiste de **rares plaques en neige ventée dans les versants Nord au-dessus de 2000/2200 m**. Elles sont encore localement réactives, notamment dans les zones d'accumulation en pente raide. Ces plaques sont constituées d'une neige fortement densifiée voire durcie par le vent en surface, ce qui permet dans la plupart des cas de les identifier. **Cassures modestes, 15 à 30 cm** donnant des avalanches petites à moyennes.

Qualité de la neige

Enneigement : un peu au dessus de la moyenne, mais les prochains jours de chaleur vont bien attaquer le manteau.

Limite skiable : vers 1300 m en Nord, 1600 m en Sud.

Qualité de la neige : encore une neige froide dans les versants Nord, dès 2000/2200 m, avec une poudre tassée agréable sauf dans les secteurs ayant subi la bise et alors parfois très hétérogènes (croupes/crêtes pelées).
Dans tous les autres versants, manteau en cours de "printanisation" : neige n'ayant pas encore subi suffisamment de cycles gel/dégel pour assurer une portance dans tous les secteurs au matin (sauf en Sud où ça devrait déjà être bon jusqu'à ~2500 m). Puis bottage/collante l'après-midi :-(

Aperçu météo pour le samedi 04 avril

	nuit	matin	après-midi	soir
Ciel bleu et douceur marquée. Vent faible.				
Pluie-Neige				
Iso 0 °C	2 300 m	2 800 m	3 100 m	3 100 m
Vent 2500 m	↘ 15 km/h	↘ 15 km/h	→ 10 km/h	← 10 km/h
Vent 3500 m	↓ 25 km/h	↓ 25 km/h	↘ 20 km/h	↘ 20 km/h

Épaisseur de neige hors-piste

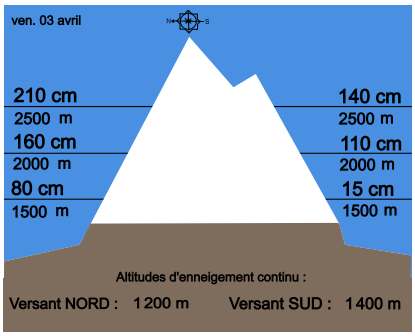

Précipitations à 1800 m

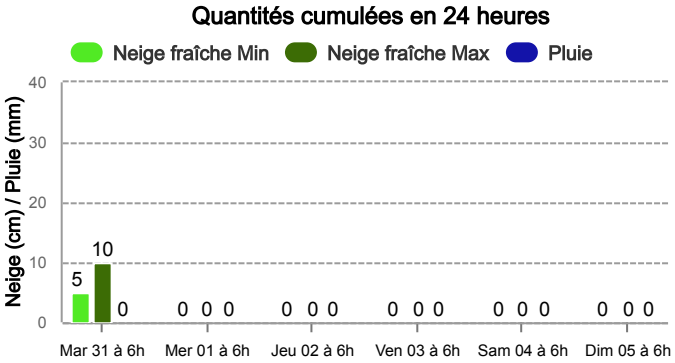

Tendance du dimanche 05 avril

2 **Indice de risque limité**

Évolution rapide vers une situation de neige humide printanière avec un risque faible le matin, devenant limité en journée. Les rares plaques en neige froide deviennent anecdotiques.

Pour consulter la vigilance en cours, veuillez vous rendre sur le site https://vigilance.meteofrance.fr/fr

Météo-France - 73 avenue de Paris, 94165 Saint-Mandé cedex - Contact : contact@meteo.fr

Rédigé par Météo-France avec la contribution des observateurs du réseau nivo-météorologiques. Partenariat : ANMSM (Maires de Stations de Montagne), DSF (Domaines Skiables de France), ADSP (Directeurs de Pistes et de la Sécurité des Stations de Sports d'Hiver) et autres acteurs de la montagne.

Bulletin neige & avalanches par téléphone au **0 892 68 10 20** Service 0,35 € / min + prix appel

RÉPUBLIQUE FRANÇAISE
Liberté Égalité Fraternité

METEO FRANCE
À VOS CÔTÉS, DANS UN CLIMAT QUI CHANGE

Bulletin d'estimation du risque d'avalanche

(valable en dehors des pistes balisées et ouvertes)

MASSIF : Haute-Tarentaise

Rédigé le vendredi 3 avril 2026 à 16h

Conditions nivo-météo des 7 derniers jours

	sam. 28/03				dim. 29/03				lun. 30/03				mar. 31/03				mer. 01/04				jeu. 02/04				ven. 03/04			
	03h	09h	15h	21h	03h	09h	15h	21h	03h	09h	15h	21h	03h	09h	15h	21h	03h	09h	15h	21h	03h	09h	15h	21h	03h	09h	15h	21h
Météo																												
Vent (km/h)	30	40	40	30	25	25	20	20	30	65	70	75	80	50	45	55	70	35	20	20	30	40	40	40	40	30	25	25
à 3500m																												
Vent (km/h)	20	30	30	20	20	20	15	15	15	30	55	60	50	30	30	35	30	20	15	15	20	30	30	30	30	20	15	15
à 2500m																												

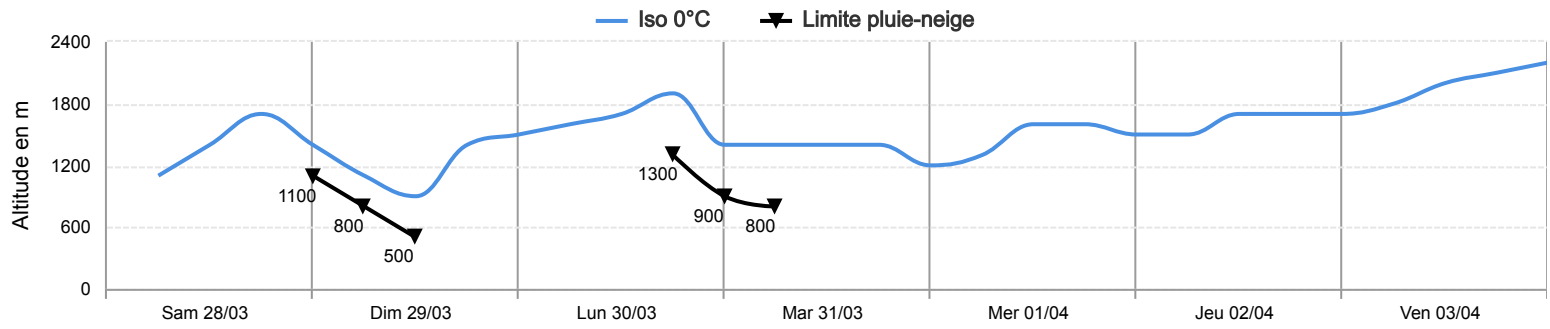

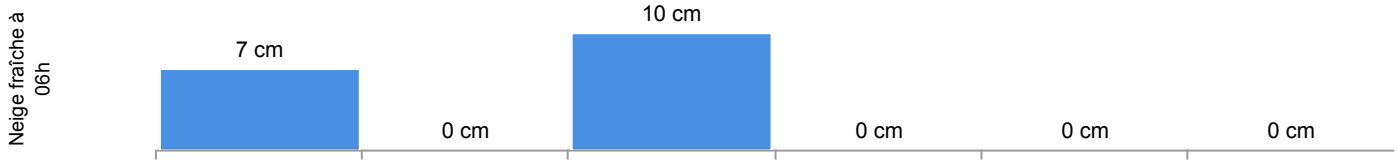

Risque d'avalanche	sam. 28/03	dim. 29/03	lun. 30/03	mar. 31/03	mer. 01/04	jeu. 02/04	ven. 03/04
	2	2	2	3	2	2	2

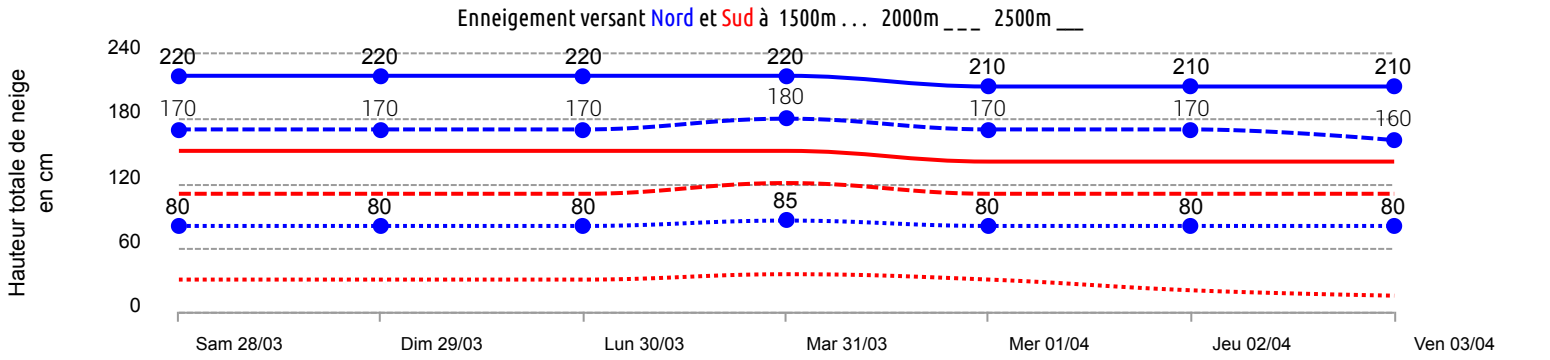

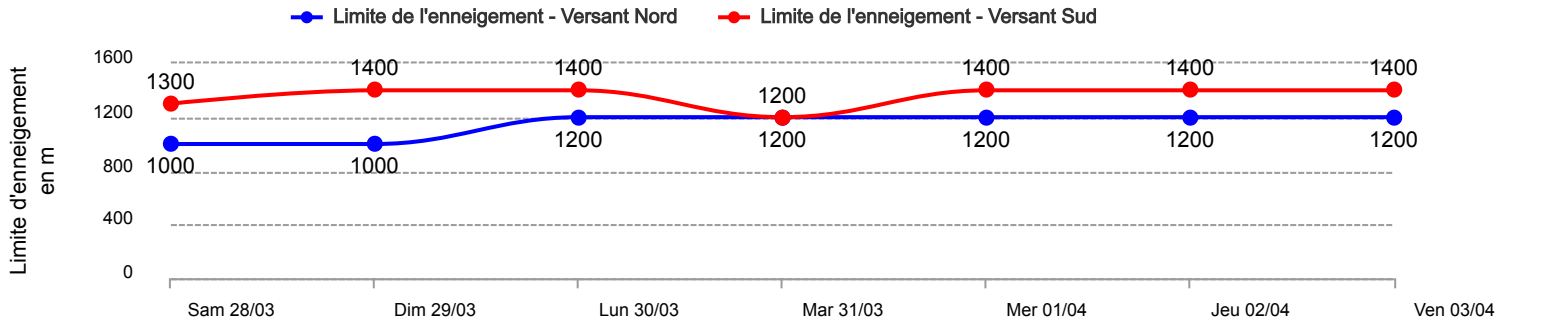

Pour consulter la vigilance en cours, veuillez vous rendre sur le site https://vigilance.meteofrance.fr/fr

Météo-France - 73 avenue de Paris, 94165 Saint-Mandé cedex - Contact : contact@meteo.fr

Bulletin neige & avalanches par téléphone au

0 892 68 10 20 Service 0,35 € / min + prix appel

Rédigé par Météo-France avec la contribution des observateurs du réseau nivo-météorologiques. Partenariat : ANMSM (Maires de Stations de Montagne), DSF (Domaines Skiables de France), ADSP (Directeurs de Pistes et de la Sécurité des Stations de Sports d'Hiver) et autres acteurs de la montagne.