Bulletin d'estimation du risque d'avalanche
(valable en dehors des pistes balisées et ouvertes)

MASSIF : Mercantour

Rédigé le vendredi 3 avril 2026 à 16h

Estimation des risques pour le : SAMEDI 04 AVRIL

DÉPARTS SUPERFICIELS EN NEIGE HUMIDE

2

1 → 2

N O E S

Indice de risque faible évoluant en limité.

Départs spontanés : peu probables

Déclenchements provoqués : plaques résiduelles dans la neige ventée. Très rares.

Indices de risque : 5 très fort - 4 fort - 3 marqué - 2 limité - 1 faible -- En noir : les pentes les plus dangereuses

Stabilité du manteau neigeux

Situation avalancheuse typique : neige humide

Départs spontanés : peu probables le matin avec le regel nocturne. Puis des avalanches de neige humide se produisent dans les pentes raides, au fil de l'ensoleillement. Départs superficiels générant principalement des avalanches de petite taille (taille 1), très rarement moyenne (taille 2).

Déclenchements provoqués : - le manteau neigeux est bien stabilisé. Des plaques résiduelles peuvent persister dans de très rares pentes d'altitude, notamment en versants nord-ouest, nord et nord-est au-dessus de 2400 m environ. Elles deviennent difficiles à déclencher par un seul skieur et sont facilement identifiables. Elles génèrent des avalanches de petite taille (taille 1), plus rarement de taille moyenne (taille 2).
- Par ailleurs, un skieur peut provoquer un départ ponctuel et généralement superficiel en neige humide, en évoluant tardivement dans une pente raide ensoleillée. Avalanches de taille petite.

Qualité de la neige

Enneigement plutôt excédentaire pour un début avril.
Hauteurs de neige observées : 148 cm à la nivose de Millefonts à 2430 m, 100 cm à Isola 2000 à 1912 m.

Enneigement skiable : vers 1400/1500 m en terrain favorable en ubacs, 1800/1900 m en adrets peu pentus.

État de la neige en surface : manteau neigeux printanier bien regelé en adrets, fortement durci par le vent en altitude. Humidification superficielle au soleil en journée.

Aperçu météo pour le samedi 04 avril

nuit	matin	après-midi	soir

Ensoleillé et de plus en plus doux.

Pluie-Neige				
Iso 0 °C	2 700 m	2 800 m	2 900 m	3 100 m
Vent 2000 m	15 km/h	10 km/h	15 km/h	10 km/h
Vent 3000 m	15 km/h	10 km/h	20 km/h	10 km/h

Épaisseur de neige hors-piste

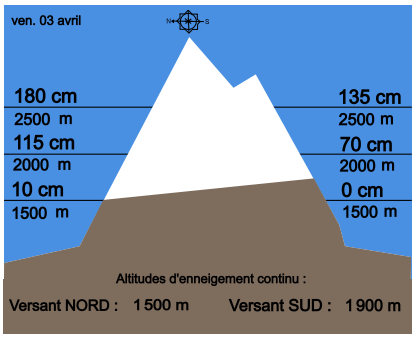

Précipitations à 1800 m

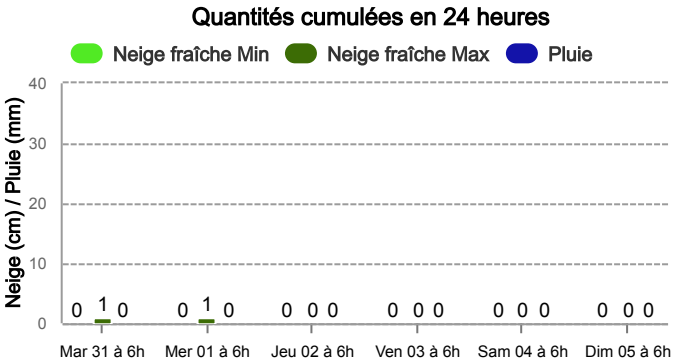

Tendance du dimanche 05 avril

2

Indice de risque limité

Maintien d'un risque limité. L'humidification du manteau neigeux se poursuit lentement.

Pour consulter la vigilance en cours, veuillez vous rendre sur le site https://vigilance.meteofrance.fr/fr

Météo-France - 73 avenue de Paris, 94165 Saint-Mandé cedex - Contact : contact@meteo.fr

Rédigé par Météo-France avec la contribution des observateurs du réseau nivo-météorologiques. Partenariat : ANMSM (Maires de Stations de Montagne), DSF (Domaines Skiables de France), ADSP (Directeurs de Pistes et de la Sécurité des Stations de Sports d'Hiver) et autres acteurs de la montagne.

Bulletin neige & avalanches par téléphone au
0 892 68 10 20 Service 0,35 € / min + prix appel

RÉPUBLIQUE FRANÇAISE
Liberté Égalité Fraternité

METEO FRANCE
À VOS CÔTÉS, DANS UN CLIMAT QUI CHANGE

Bulletin d'estimation du risque d'avalanche
(valable en dehors des pistes balisées et ouvertes)

MASSIF : Mercantour

Rédigé le vendredi 3 avril 2026 à 16h

Conditions nivo-météo des 7 derniers jours

	sam. 28/03				dim. 29/03				lun. 30/03				mar. 31/03				mer. 01/04				jeu. 02/04				ven. 03/04			
	03h	09h	15h	21h	03h	09h	15h	21h	03h	09h	15h	21h	03h	09h	15h	21h	03h	09h	15h	21h	03h	09h	15h	21h	03h	09h	15h	21h
Météo																												
Vent (km/h)	25	25	25	25	40	35	35	15	40	50	80	95	65	60	90	120	100	70	65	65	55	35	35	30	25	25	40	35
à 3000m																												
Vent (km/h)	10	15	20	20	30	30	20	10	25	20	40	55	40	50	75	90	75	50	50	40	40	30	20	25	30	20	25	20
à 2000m																												

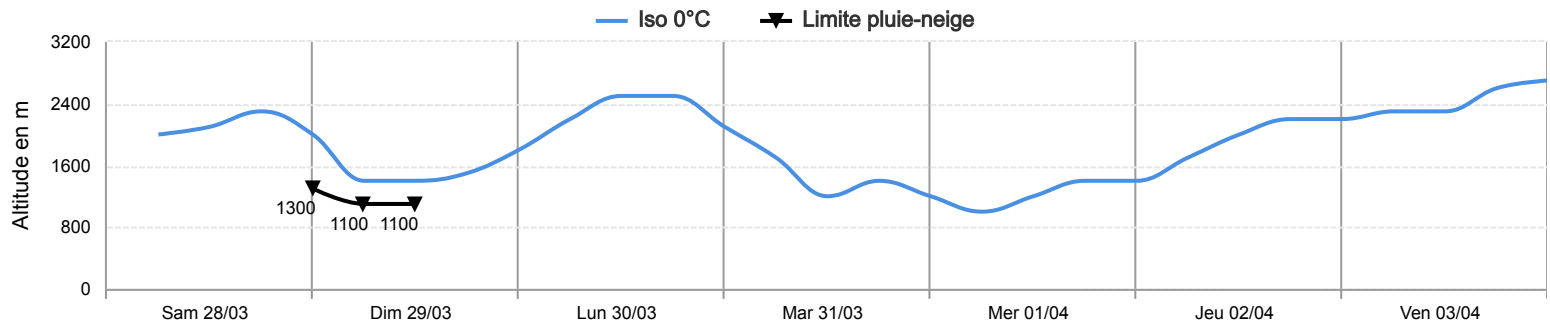

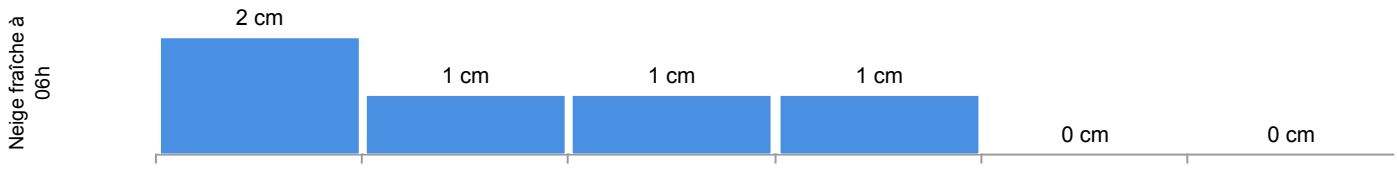

Risque d'avalanche	sam. 28/03	dim. 29/03	lun. 30/03	mar. 31/03	mer. 01/04	jeu. 02/04	ven. 03/04
	2	2	2	2	2	2	1

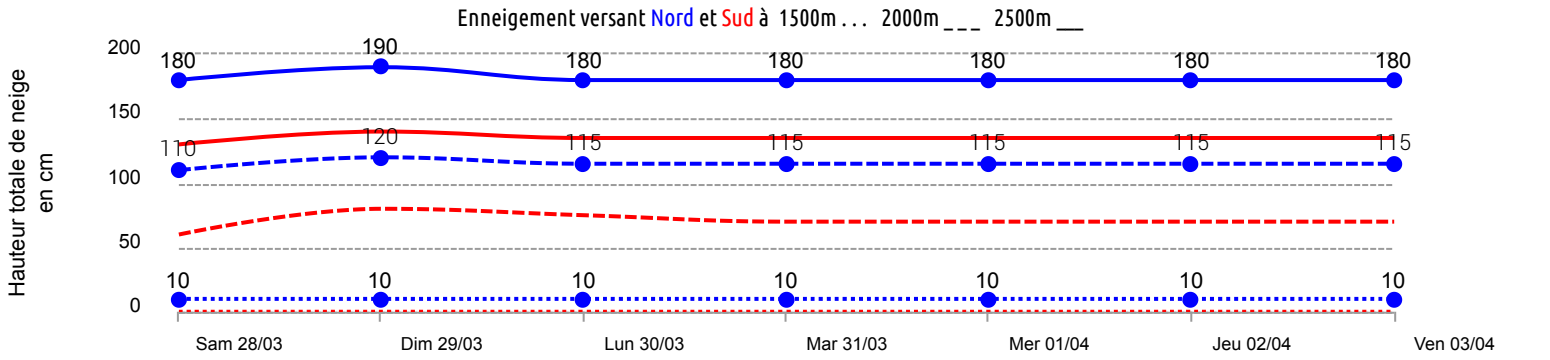

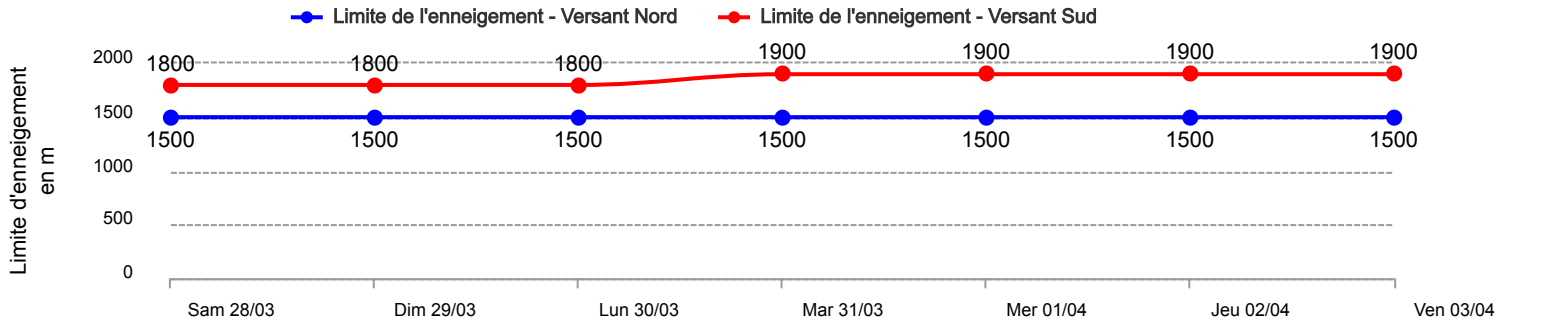

Pour consulter la vigilance en cours, veuillez vous rendre sur le site https://vigilance.meteofrance.fr/fr

Météo-France - 73 avenue de Paris, 94165 Saint-Mandé cedex - Contact : contact@meteo.fr

Rédigé par Météo-France avec la contribution des observateurs du réseau nivo-météorologiques. Partenariat : ANMSM (Maires de Stations de Montagne), DSF (Domaines Skiables de France), ADSP (Directeurs de Pistes et de la Sécurité des Stations de Sports d'Hiver) et autres acteurs de la montagne.

Bulletin neige & avalanches par téléphone au
0 892 68 10 20 Service 0,35 € / min + prix appel