Bulletin d'estimation du risque d'avalanche
(valable en dehors des pistes balisées et ouvertes)

MASSIF : Oisans

Rédigé le vendredi 3 avril 2026 à 16h

Estimation des risques pour le : SAMEDI 04 AVRIL

REDOUX AU SOLEIL, DAVANTAGE EN ALTITUDE : QUELQUES COULEES OU AVALANCHES HUMIDES AU FIL DES HEURES... EN FACES NORD, RARES PLAQUES...

2

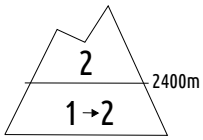

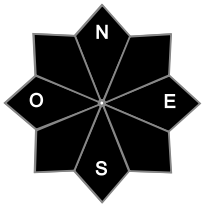

Au soleil + rares N

Au-dessus de 2400m indice de risque limité, plus bas indice faible évoluant en limité.

Départs spontanés : Suivant la course du soleil, quelques nouvelles coulées puis avalanches en pentes raides/humidifiées (près des rochers), de taille 1 à 2...

Déclenchements provoqués : Rare plaque de surface en versant Nord à Nord-Ouest d'altitude. En pente bien humide, possible coulée ponctuelle sous les skis...

Indices de risque : 5 très fort - 4 fort - 3 marqué - 2 limité - 1 faible -- En noir : les pentes les plus dangereuses

Stabilité du manteau neigeux

Situation avalancheuse typique : neige humide neige ventée

Un peu d'activité printanière suivant la course du soleil, et plus en altitude. En faces Nord de rares plaques. Attention aussi aux surfaces durcies/regelées.

Départs spontanés :

Regel nocturne puis samedi le redoux sera net en versants ensoleillés et se produit davantage en altitude. Au fil de la journée et notamment près des rochers on peut s'attendre à quelques nouvelles coulées humides. En longue pente raide possible avalanche plus conséquente.
Une rupture spontanée de corniche n'est pas exclue, notamment sous 2500/2800m environ ?

Déclenchements provoqués :

En faces Nord d'altitude, la neige récente a été soufflée (bise de Nord-Est). Risque résiduel de plaque de surface, parfois dure, notamment vers le Nord Oisans et le Taillefer où il neigé mardi.
Le travail du vent est les accumulations seraient assez visibles, prendre des distances... Rupture potentielle 15/30 cm environ
En pentes soutenues et bien humidifiées (suivant la course du soleil), le skieur se méfiera d'un risque de coulée humide ponctuelle sous un virage, la neige plus récente pouvant glisser sur les sous-couches denses...

Autres : A l'ombre neige durcie par regel, anciennes traces parfois lustrées. En pentes où le soleil est plus rasant des secteurs temporairement croutés et ski délicat....

Qualité de la neige

Qualification de l'enneigement : L'enneigement est bon dès la moyenne montagne "froide", les fonds de vallées et même abondant vers les combes. En revanche la haute altitude raide et certains glaciers sont assez secs...
Limites skiables : Vers 1300/1500m en Nord, 1600/2100m au soleil suivant l'exposition/ la raideur de la pente...

Qualité de la neige samedi : En Sud neige plus transformée, quasi printanière à modeste altitude... Regel nocturne puis rapide humidification suivant la course du soleil. Humidification plus conséquente par rapport aux jours précédents...
Neige encore sèche en plein Nord au dessus de 2200m environ. Neige rarement poudreuse dense en couloirs abrités ou bien souvent cartonnée/sculptée, durcie par la bise du début de semaine...

Aperçu météo pour le samedi 04 avril

	nuit	matin	après-midi	soir
Pluie-Neige				
Iso 0 °C	2 500 m	3 100 m	3 100 m	3 200 m
Vent 2500 m	15 km/h	10 km/h	5 km/h	5 km/h
Vent 3500 m	25 km/h	20 km/h	10 km/h	10 km/h

Grand beau. Regel nocturne, puis net redoux en journée, très printanier !

Épaisseur de neige hors-piste

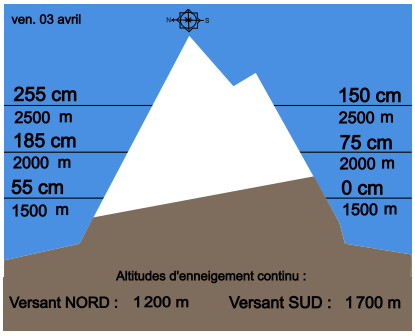

Précipitations à 1800 m

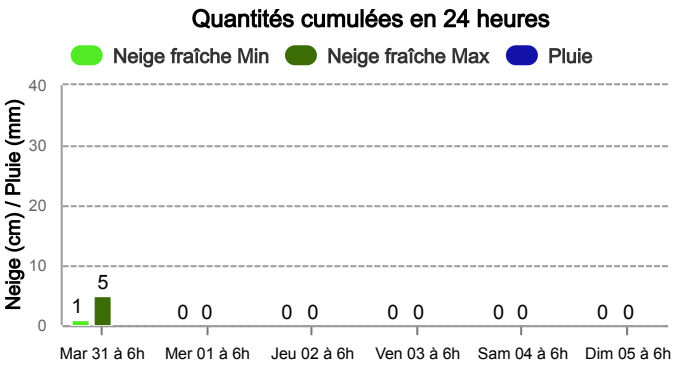

Tendance du dimanche 05 avril

2

Indice de risque limité

Risque stationnaire ou en légère baisse.
Quelques nouvelles coulées ou avalanches de printemps, parfois volumineuses...

Pour consulter la vigilance en cours, veuillez vous rendre sur le site https://vigilance.meteofrance.fr/fr

Météo-France - 73 avenue de Paris, 94165 Saint-Mandé cedex - Contact : contact@meteo.fr

Rédigé par Météo-France avec la contribution des observateurs du réseau nivo-météorologiques. Partenariat : ANMSM (Maires de Stations de Montagne), DSF (Domaines Skiables de France), ADSP (Directeurs de Pistes et de la Sécurité des Stations de Sports d'Hiver) et autres acteurs de la montagne.

Bulletin neige & avalanches par téléphone au
0 892 68 10 20 Service 0,35 € / min + prix appel

RÉPUBLIQUE FRANÇAISE
Liberté Égalité Fraternité

METEO FRANCE
À VOS CÔTÉS, DANS UN CLIMAT QUI CHANGE

Bulletin d'estimation du risque d'avalanche
(valable en dehors des pistes balisées et ouvertes)

MASSIF : Oisans

Rédigé le vendredi 3 avril 2026 à 16h

Conditions nivo-météo des 7 derniers jours

	sam. 28/03				dim. 29/03				lun. 30/03				mar. 31/03				mer. 01/04				jeu. 02/04				ven. 03/04			
	03h	09h	15h	21h	03h	09h	15h	21h	03h	09h	15h	21h	03h	09h	15h	21h	03h	09h	15h	21h	03h	09h	15h	21h	03h	09h	15h	21h
Météo																												
Vent (km/h)	55	50	55	55	50	35	30	25	50	80	95	105	120	120	110	80	70	60	25	25	25	35	45	40	40	40	30	30
à 3500m																												
Vent (km/h)	40	45	50	50	45	30	25	20	35	65	70	85	85	90	80	45	40	40	25	0	0	0	5	0	0	5	5	0
à 2500m																												

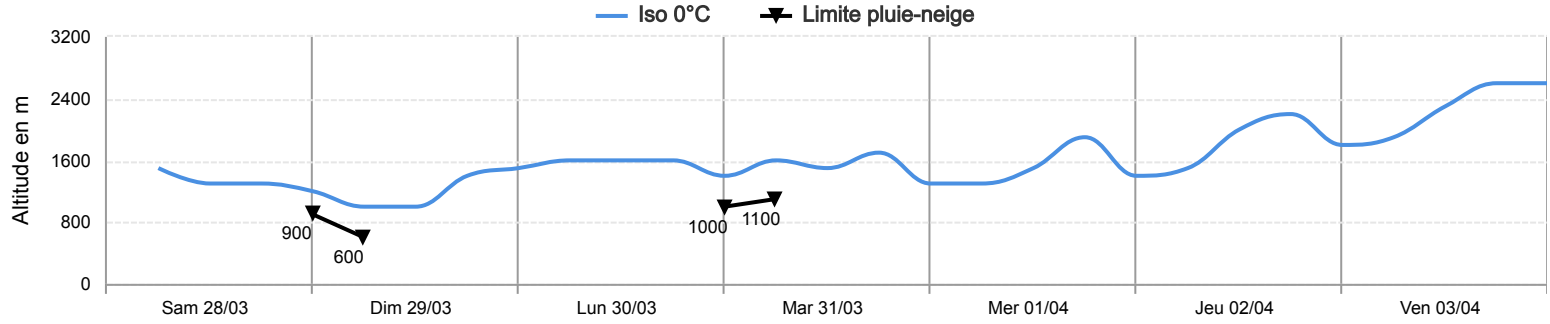

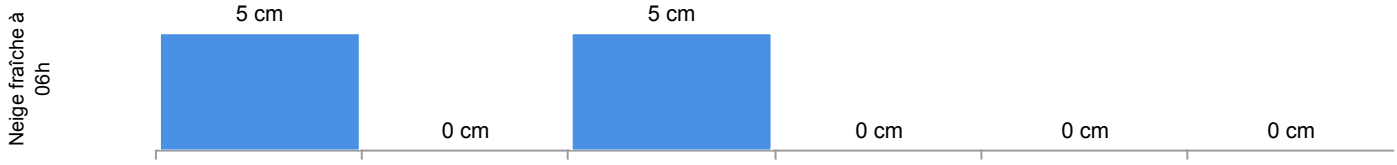

Risque d'avalanche	sam. 28/03	dim. 29/03	lun. 30/03	mar. 31/03	mer. 01/04	jeu. 02/04	ven. 03/04
	2	2	2	2	3	2	2

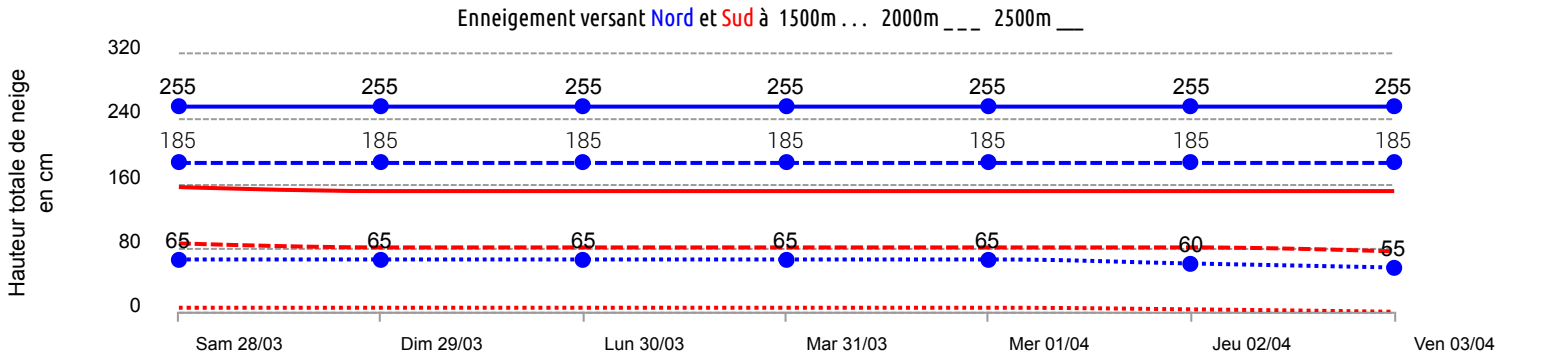

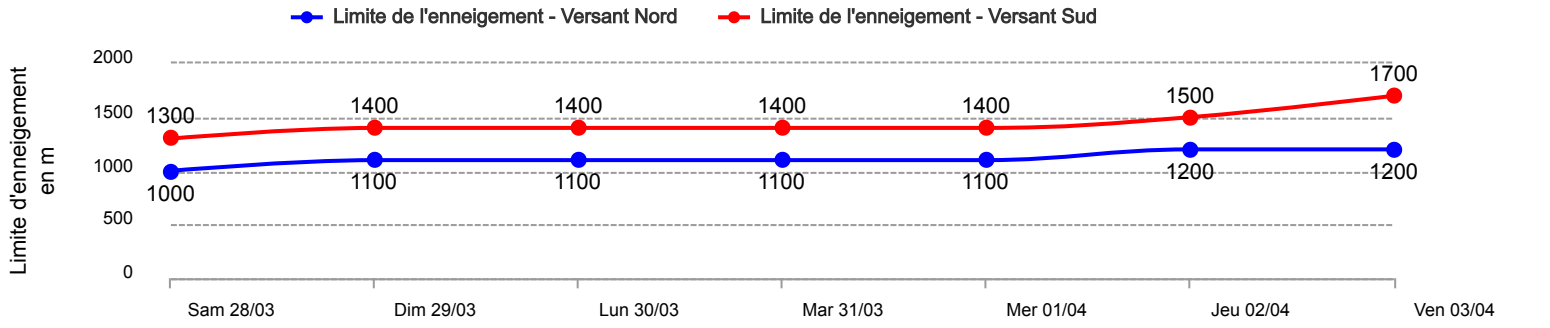

Pour consulter la vigilance en cours, veuillez vous rendre sur le site https://vigilance.meteofrance.fr/fr

Météo-France - 73 avenue de Paris, 94165 Saint-Mandé cedex - Contact : contact@meteo.fr

Bulletin neige & avalanches par téléphone au **0 892 68 10 20** Service 0,35 € / min + prix appel

Rédigé par Météo-France avec la contribution des observateurs du réseau nivo-météorologiques. Partenariat : ANMSM (Maires de Stations de Montagne), DSF (Domaines Skiables de France), ADSP (Directeurs de Pistes et de la Sécurité des Stations de Sports d'Hiver) et autres acteurs de la montagne.