Bulletin d'estimation du risque d'avalanche

(valable en dehors des pistes balisées et ouvertes)

MASSIF : Haute-Bigorre

Rédigé le vendredi 3 avril 2026 à 17h

Estimation des risques pour le : SAMEDI 04 AVRIL

NEIGE VENTÉE EN NORD, NEIGE HUMIDE AU SOLEIL

3

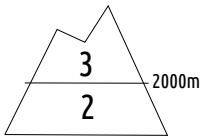

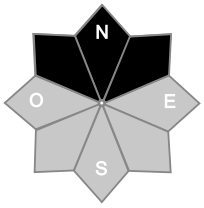

Quelques plaques

Au-dessus de 2000m indice de risque marqué, plus bas indice limité.

Départs spontanés : Au fil de l'ensoleillement, rarement grandes

Déclenchements provoqués : Plaques facilement déclenchables en versants nord d'altitude

Indices de risque : 5 très fort - 4 fort - 3 marqué - 2 limité - 1 faible -- En noir : les pentes les plus dangereuses

Stabilité du manteau neigeux

Situation avalancheuse typique : neige ventée neige humide

Déclenchements provoqués :
Au-dessus de 2000m, dans les expositions ombragées, des plaques sont en place, formées lors des dernières chutes de neige. Elles se situent préférentiellement dans les zones abritées du vent : derrière des crêtes ou cols, dans les combes, etc, et sont plus nombreuses dans les expositions nord-est, plus protégées du vent et où les accumulations sont plus nombreuses. Elles sont encore facilement déclenchables, formées d'un empilement de neiges hétérogènes. Les accumulations mobilisables parfois importantes peuvent parfois entraîner le déclenchement d'une grande avalanche.
Au sein du massif, les cumuls ont été assez variables, certains secteurs, par exemple de Gavarnie à Piau, peuvent avoir reçu des cumuls moindres, inférieurs à 25cm, les plaques y sont moins nombreuses, souvent mieux identifiables avec l'alternance de zones d'érosion et d'accumulation.

Déclenchements spontanés :
Au fil de l'ensoleillement (est le matin, puis sud et ouest l'après-midi), des départs en neige humide sont attendus, mobilisant la neige récente. Ils sont en général de petite taille, parfois moyenne avec des départs linéaires. Une grande est possible, partant d'une accumulation en sud-est en haut du massif.

Qualité de la neige

Enneigement : Bon pour la saison, débutant par plaques vers 1300m, continu vers 1500m en nord, mais sans sous-couche jusqu'à 1800m en sud.
État de la neige : Une trentaine de centimètres de neige récente vers 1800m, inégalement répartie : zones pelées par le vent avec la glace ou le sol qui affleure, et des accumulations ailleurs.
Les cumuls récents sont hétérogènes, plus importants vers l'avant de la chaîne en général.
Samedi, des pentes exposées nord, rares sous 2000m, un peu plus nombreuses plus haut, sont encore en neige sèche, les autres sont croûtées le matin, en neige humide peu portante ensuite.

Aperçu météo pour le samedi 04 avril

	nuit	matin	après-midi	soir
Largement ensoleillé, vent faible				
Pluie-Neige				
Iso 0 °C	2 500 m	3 100 m	3 200 m	3 300 m
Vent 2000 m	↙ 15 km/h	↖ 10 km/h	← 10 km/h	↗ 10 km/h
Vent 3000 m	↙ 45 km/h	↖ 20 km/h	↗ 15 km/h	↑ 15 km/h

Épaisseur de neige hors-piste

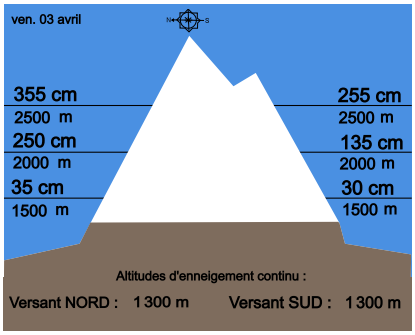

Précipitations à 1800 m

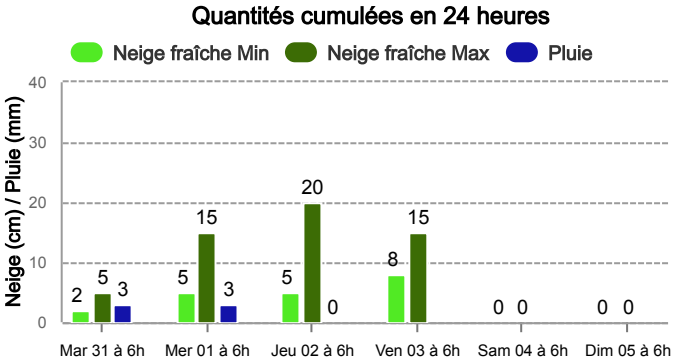

Tendance du dimanche 05 avril

2

Indice de risque limité

Raréfaction progressive des plaques, poursuite de l'humidification au soleil

Pour consulter la vigilance en cours, veuillez vous rendre sur le site https://vigilance.meteofrance.fr/fr

Météo-France - 73 avenue de Paris, 94165 Saint-Mandé cedex - Contact : contact@meteo.fr

Rédigé par Météo-France avec la contribution des observateurs du réseau nivo-météorologiques. Partenariat : ANMSM (Maires de Stations de Montagne), DSF (Domaines Skiables de France), ADSP (Directeurs de Pistes et de la Sécurité des Stations de Sports d'Hiver) et autres acteurs de la montagne.

Bulletin neige & avalanches par téléphone au **0 892 68 10 20** Service 0,35 € / min + prix appel

RÉPUBLIQUE FRANÇAISE
Liberté Égalité Fraternité

METEO FRANCE
À VOS CÔTÉS, DANS UN CLIMAT QUI CHANGE

Bulletin d'estimation du risque d'avalanche

(valable en dehors des pistes balisées et ouvertes)

MASSIF : Haute-Bigorre

Rédigé le vendredi 3 avril 2026 à 17h

Conditions nivo-météo des 7 derniers jours

	sam. 28/03				dim. 29/03				lun. 30/03				mar. 31/03				mer. 01/04				jeu. 02/04				ven. 03/04			
	03h	09h	15h	21h	03h	09h	15h	21h	03h	09h	15h	21h	03h	09h	15h	21h	03h	09h	15h	21h	03h	09h	15h	21h	03h	09h	15h	21h
Météo																												
Vent (km/h)	45	55	60	85	90	105	85	75	65	70	75	80	70	70	70	90	75	80	90	90	85	90	80	75	60	50	40	35
à 3000m																												
Vent (km/h)	15	20	30	55	65	70	60	40	25	25	35	40	35	35	35	45	40	40	45	60	50	50	50	45	35	15	20	15
à 2000m																												

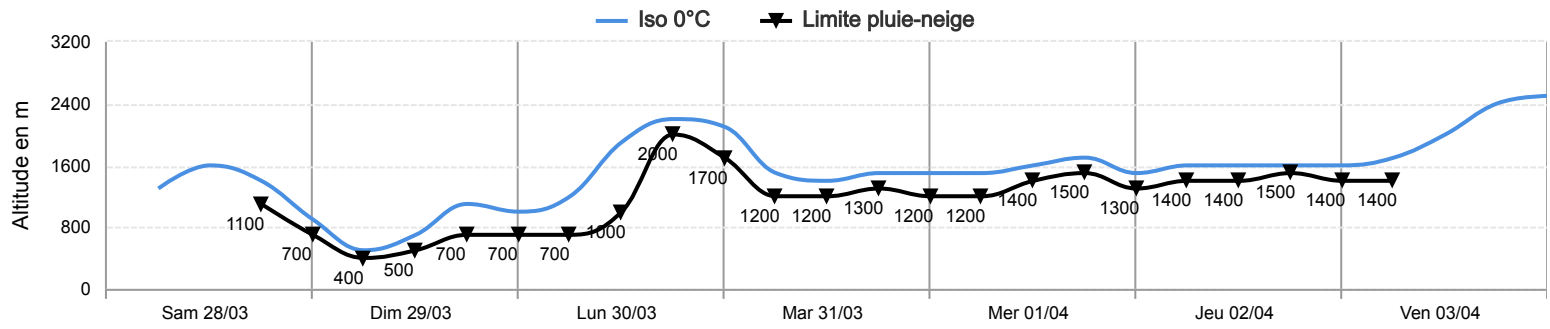

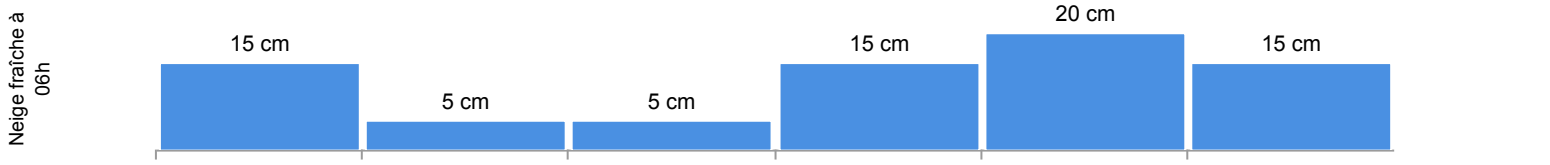

Risque d'avalanche	sam. 28/03	dim. 29/03	lun. 30/03	mar. 31/03	mer. 01/04	jeu. 02/04	ven. 03/04
	2	3	3	3	4	4	4

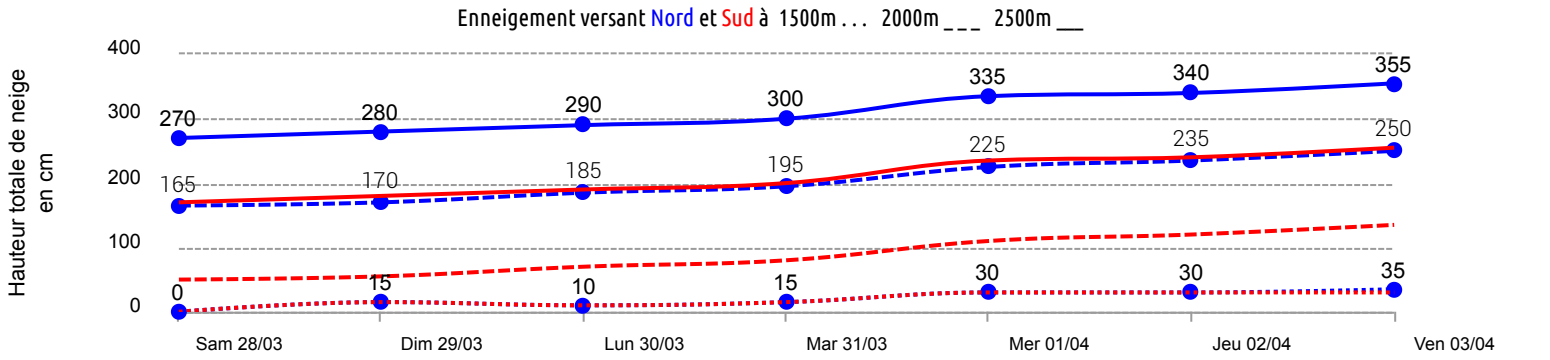

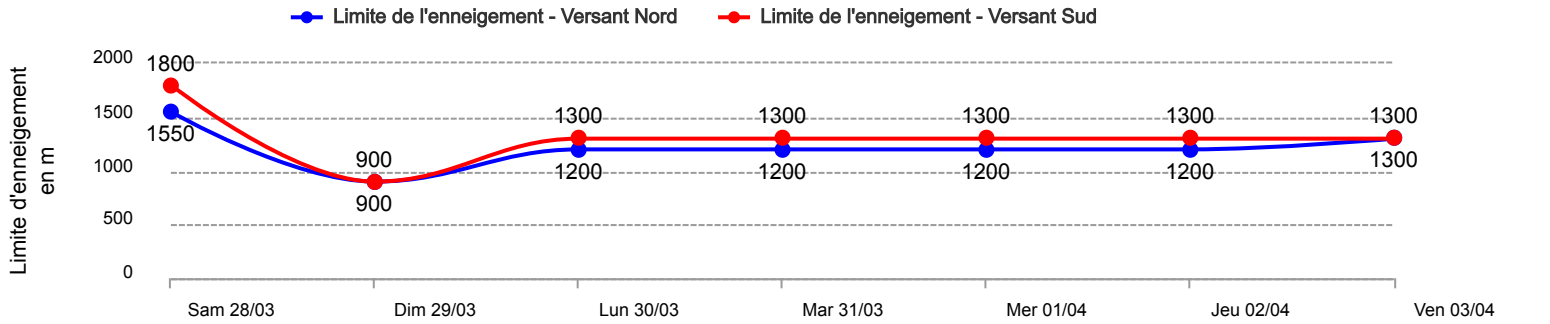

Pour consulter la vigilance en cours, veuillez vous rendre sur le site https://vigilance.meteofrance.fr/fr

Météo-France - 73 avenue de Paris, 94165 Saint-Mandé cedex - Contact : contact@meteo.fr

Rédigé par Météo-France avec la contribution des observateurs du réseau nivo-météorologiques. Partenariat : ANMSM (Maires de Stations de Montagne), DSF (Domaines Skiables de France), ADSP (Directeurs de Pistes et de la Sécurité des Stations de Sports d'Hiver) et autres acteurs de la montagne.

Bulletin neige & avalanches par téléphone au
0 892 68 10 20 Service 0,35 € / min + prix appel