GOBIERNO DE ESPAÑA
VICEPRESIDENCIA TERCERA DEL GOBIERNO
MINISTERIO PARA LA TRANSICIÓN ECOLÓGICA Y EL RETO DEMOGRÁFICO

Boletín de información nivológica y de peligro de aludes

Pirineo Catalán

aemet Agencia Estatal de Meteorología

sábado, 4 de abril de 2026

Pronóstico hasta las 24 horas del domingo, día 5 de abril

(Válido fuera de pistas de esquí balizadas y abiertas)

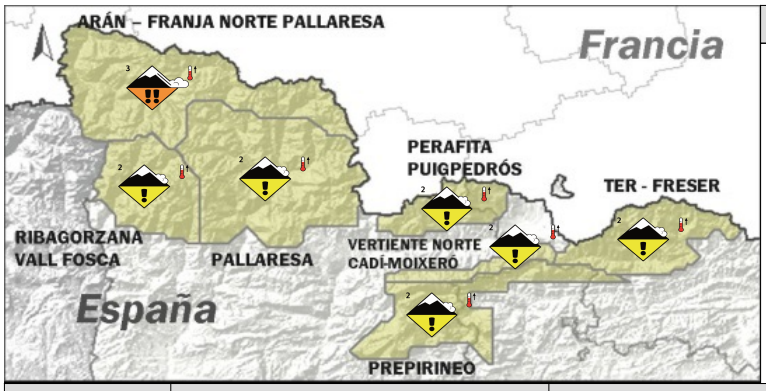

Problemas de aludes

- Placas de viento
- Nieve húmeda
- Capas débiles persistentes

Macizo	Peligro	Problemas de aludes, cota, orientación, tamaño	Innivación observada (m)
Arán - Franja norte Pallaresa	3 – Notable	**Capas débiles persistentes** – 2100 – N, E – 3 **Nieve húmeda** – S – 2	2026-04-04 N / S – Cota más baja caras N
Ribagorzana - Vall Fosca	2 – Limitado	**Placas de viento** – 2200 – N – 2 **Nieve húmeda** – N, E, S – 2	2026-04-04 N / S – Cota más baja caras N
Pallaresa	2 – Limitado	**Placas de viento** – 2200 – N – 2 **Nieve húmeda** – N, E, S – 2	2026-04-04 N / S – Cota más baja caras N

AEMET. Se autoriza la reproducción de su contenido citando la fuente.

Boletín de información nivológica y de peligro de aludes

Pirineo Catalán

Perafita - Puigpedrós	2 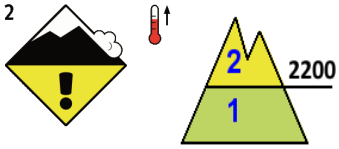 **Limitado**	**Placas de viento** 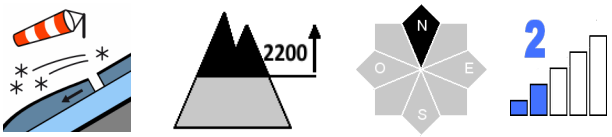 **Nieve húmeda** 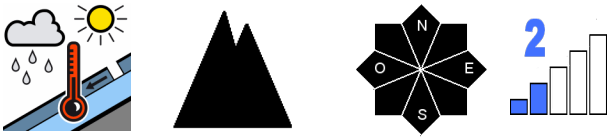	2026-04-04 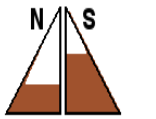 Cota más baja caras N
Ter - Freser	2 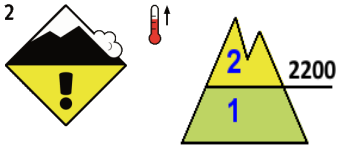 **Limitado**	**Placas de viento** **Nieve húmeda** 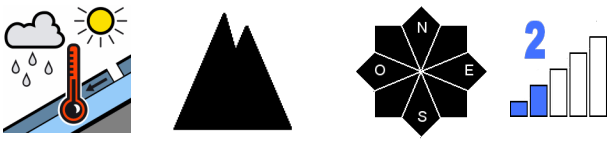	2026-04-04 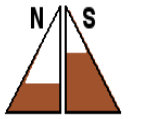 Cota más baja caras N
Vertiente norte Cadí - Moixeró	2 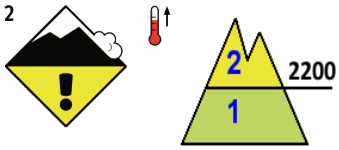 **Limitado**	**Placas de viento** **Nieve húmeda** 	2026-04-04 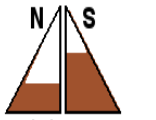 Cota más baja caras N
Prepirineo	2 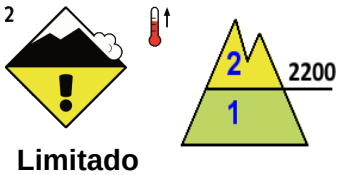 **Limitado**	**Nieve húmeda**	2026-04-04 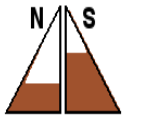 Cota más baja caras N

Estado del manto y observaciones recientes

Tras el fin del episodio de nevadas, ayer dominaron los cielos despejados y el ascenso de las temperaturas, que continuarán durante la jornada de hoy, propiciado la humidificación y el retroceso del manto, así como la estabilización progresiva de las placas de viento, especialmente en solanas.

La cubierta es más o menos continua a partir de unos 1700 en umbrías y 1900 metros en solanas aproximadamente, algo menos en el Arán y la Franja Norte Pallaresa donde las nevadas fueron más copiosas. A unos 2200-2400 metros se alcanzan los 150-250 cm en este macizo, y alrededor de los 80-150 cm en el resto. Son valores muy por encima de lo habitual para estas fechas, que se pueden superar ampliamente en ventisqueros y otras zonas propensas a la acumulación.

AEMET. Se autoriza la reproducción de su contenido citando la fuente.

Los vientos fuertes de componente norte que acompañaron a las nevadas han seguido soplando hasta esta madrugada, por lo que aún hay presencia de placas de viento en umbrías y en alguna solana de cotas altas, que en ciertos casos pueden descansar sobre estratos débiles de nieve reciente enterrada. En solanas de cotas medias y bajas el manto está humidificado y es de tipo primaveral. En general la distribución de la nieve nueva es muy irregular, con zonas discontinuas y erosionadas a barlovento donde aflora la costra de nieve vieja y con grandes acumulaciones en zonas protegidas del viento, especialmente en canales, cubetas y cordales. Asimismo, continúan presentes algunas capas débiles persistentes en el manto, de las cuales aquellas menos profundas podrían mostrar cierta reactividad.

Evolución del manto y peligro de aludes para el domingo, día 5

Problema de placas de viento. Problema de nieve húmeda y deslizamientos basales.

Mañana continuarán los cielos despejados y aún ascenderán algo más las temperaturas, que serán más cálidas que la media climática de esta época del año. Continuará la humidificación del manto y la estabilización progresiva de las placas de viento.

Con estas condiciones se esperan aludes naturales de nieve húmeda en toda la montaña, más probables en solanas y a partir de mediodía, que serán generalmente de tamaño pequeño (riesgo de caída) o mediano (capaz de enterrar a una persona). Asimismo, podrán darse también deslizamientos basales en terrenos herbosos o de roca lisa generalmente de tamaño mediano.

Las placas de viento formadas durante el episodio pasado aún podrán mantenerse frágiles en umbrías y ceder ante una sobrecarga débil (un esquiador). Podrán provocar aludes de tamaño mediano o raramente grande (capaz de enterrar un vehículo) en zonas de mayor acumulación o en caso de afectar a una capa débil enterrada o persistente.

Predicción meteorológica para el domingo, día 5

Poco nuboso o despejado, con algunos intervalos de nubes de evolución diurna por la tarde. Probables algunos chubascos vespertinos aislados, de nieve por encima de 2600-2800 metros. Temperaturas en ascenso. Heladas débiles en las cumbres de mayor altitud. Flojo de dirección variable aunque con predominio de la componente sur.

Datos en la atmósfera libre:

Altitud de la isoterma de 0 ºC: 3200 m
Altitud de la isoterma de -10 ºC: 4600 m

Viento a 1500 m: S 10 km/h
Viento a 3000 m: W 10 km/h

Evolución para el lunes día 6

Problema de placas de viento en ligero descenso. Problema de nieve húmeda y deslizamientos basales estacionario.

AEMET. Se autoriza la reproducción de su contenido citando la fuente.

Boletín de información nivológica y de peligro de aludes

Pirineo Catalán

Escala europea de peligro de aludes

Débil | Limitado | Notable | Fuerte | Muy Fuerte

Problemas de aludes

Nieve reciente | Placas de viento | Capas débiles persistentes | Nieve húmeda | Deslizamientos basales | Sin problema evidente

Nota1: Se recuerda que, siempre que haya nieve, la ausencia total de peligro no existe. Hay que tener presente que en circunstancias desfavorables, con aludes de tamaño 1 (alud pequeño o colada) y tamaño 2 (alud mediano), se pueden sufrir severos daños personales.

Nota2: Los BPA se elaboran en base a información meteorológica así como al estado del manto nivoso a través de sondeos puntuales. Se advierte a los usuarios de la variabilidad de esta información al extrapolarla a zonas extensas de montaña. Por ello, AEMET no se hace responsable de su uso para la toma de decisiones que conciernen a la seguridad personal, ni de los riesgos físicos o materiales de ellas derivadas.

AEMET. Se autoriza la reproducción de su contenido citando la fuente.