GOBIERNO DE ESPAÑA
VICEPRESIDENCIA TERCERA DEL GOBIERNO
MINISTERIO PARA LA TRANSICIÓN ECOLÓGICA Y EL RETO DEMOGRÁFICO

Boletín de información nivológica y de peligro de aludes

Pirineo Navarro y Aragonés

aemet Agencia Estatal de Meteorología

sábado, 4 de abril de 2026

Pronóstico hasta las 24 horas del domingo, día 5 de abril

(Válido fuera de pistas de esquí balizadas y abiertas)

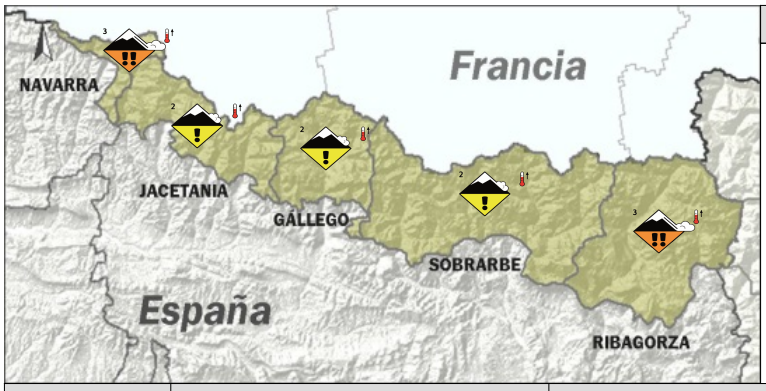

Problemas de aludes

Placas de viento

Nieve húmeda

Macizo	Peligro	Problemas de aludes, cota, orientación, tamaño	Innivación observada (m)
Navarra	3 Notable (3 / 2, 2200)	Placas de viento: 2200, N O E S, 2 Nieve húmeda: N O E S, 2	2026-04-04 N S Cota más baja caras N
Jacetania	2 Limitado (2)	Placas de viento: 2200, N O E S, 2 Nieve húmeda: N O E S, 2	2026-04-04 N S Cota más baja caras N
Gállego	2 Limitado (2)	Placas de viento: 2200, N O E S, 2 Nieve húmeda: N O E S, 2	2026-04-04 N S Cota más baja caras N

AEMET. Se autoriza la reproducción de su contenido citando la fuente.

Boletín de información nivológica y de peligro de aludes

Pirineo Navarro y Aragonés

Sobrarbe	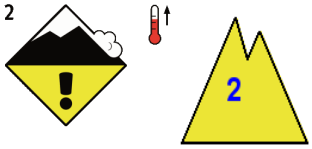 **Limitado**	**Placas de viento** **Nieve húmeda** 	2026-04-04 Cota más baja caras N
Ribagorza	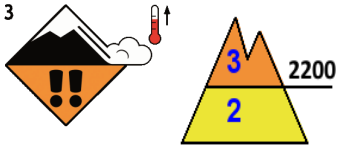 **Notable**	**Placas de viento** **Nieve húmeda** 	2026-04-04 Cota más baja caras N

Estado del manto y observaciones recientes

Tras el fin del episodio de nevadas, ayer dominaron los cielos despejados y el ascenso de las temperaturas, que continuarán durante la jornada de hoy, propiciado la humidificación y el retroceso del manto, así como la estabilización progresiva de las placas de viento, especialmente en solanas.

La cubierta es continua a partir de unos 1600-1700 metros en umbrías aproximadamente, y algo más arriba en solanas. Sin embargo, puede haber presencia de nieve discontinua a partir de unos 1400 metros con espesores de unos pocos centímetros en Navarra, la Ribagorza y en zonas próximas a la divisoria fronteriza del resto de macizos. A unos 2000-2200 metros los grosores rondan los 100-180 cm, valores por encima de lo habitual en estas fechas, que se pueden superar ampliamente en ventisqueros y otras zonas propensas a la acumulación.

Los vientos fuertes de componente norte que acompañaron a las nevadas han seguido soplando hasta esta madrugada, por lo que aún hay presencia de placas de viento en umbrías y en alguna solana de cotas altas, que en ciertos casos pueden descansar sobre estratos débiles de nieve reciente enterrada. En solanas de cotas medias y bajas el manto está humidificado y es de tipo primaveral. En general la distribución de la nieve nueva es muy irregular, con zonas discontinuas y erosionadas a barlovento donde aflora la costra de nieve vieja y con grandes acumulaciones en zonas protegidas del viento, especialmente en canales, cubetas y cordales. Asimismo, continúan presentes algunas capas débiles persistentes en el manto, de las cuales aquellas menos profundas podrían mostrar cierta reactividad.

Evolución del manto y peligro de aludes para el domingo, día 5

Problema de placas de viento. Problema de nieve húmeda y deslizamientos basales.

AEMET. Se autoriza la reproducción de su contenido citando la fuente.

Mañana continuarán los cielos despejados y aún ascenderán algo más las temperaturas, que serán más cálidas que la media climática de esta época del año. Continuará la humidificación del manto y la estabilización progresiva de las placas de viento.

Con estas condiciones se esperan aludes naturales de nieve húmeda en toda la montaña, más probables en solanas y a partir de mediodía, que serán generalmente de tamaño pequeño (riesgo de caída) o mediano (capaz de enterrar a una persona). Asimismo, podrán darse también deslizamientos basales en terrenos herbosos o de roca lisa generalmente de tamaño mediano.

Las placas de viento formadas durante el episodio pasado aún podrán mantenerse frágiles en umbrías y ceder ante una sobrecarga débil (un esquiador). Podrán provocar aludes de tamaño mediano o raramente grande (capaz de enterrar un vehículo) en zonas de mayor acumulación o en caso de afectar a una capa débil enterrada o persistente.

Predicción meteorológica para el domingo, día 5

Poco nuboso o despejado, con velos de nubes altas. Por la tarde crecerán algunas nubes de evolución diurna. No se descarta algún chubasco vespertino en los macizos aragoneses orientales, de nieve por encima de 2600-2800 metros. Temperaturas mínimas en ascenso en la mitad occidental y con pocos cambios en la oriental. Máximas en ligero ascenso. Heladas débiles en las cumbres de mayor altitud. Viento flojo de componentes sur y oeste, con intervalos moderados en cotas altas.

Datos en la atmósfera libre:

Altitud de la isoterma de 0 ºC: 3200 m
Altitud de la isoterma de -10 ºC: 4600 m

Viento a 1500 m: SW 10 km/h
Viento a 3000 m: SW 10 km/h

Evolución para el lunes día 6

Problema de placas de viento en ligero descenso. Problema de nieve húmeda y deslizamientos basales estacionario.

(Información elaborada a partir de los datos recibidos de los refugios de Linza, Lizara, Panticosa, Bachimaña, Góriz, Pineta, Estós, Angel Orús y La Renclusa, de las estaciones de esquí de Candanchú, Astún, Formigal y Panticosa (lagos), de la estación de esquí de fondo de Llanos del Hospital y de Ordesa Pradera)

Escala europea de peligro de aludes

Débil | Limitado | Notable | Fuerte | Muy Fuerte

Problemas de aludes

Nieve reciente | Placas de viento | Capas débiles persistentes | Nieve húmeda | Deslizamientos basales | Sin problema evidente

Nota1: Se recuerda que, siempre que haya nieve, la ausencia total de peligro no existe. Hay que tener presente que en circunstancias desfavorables, con aludes de tamaño 1 (alud pequeño o colada) y tamaño 2 (alud mediano), se pueden sufrir severos daños personales.

Nota2: Los BPA se elaboran en base a información meteorológica así como al estado del manto nivoso a través de sondeos puntuales. Se advierte a los usuarios de la variabilidad de esta información al extrapolarla a zonas extensas de montaña. Por ello, AEMET no se hace responsable de su uso para la toma de decisiones que conciernen a la seguridad personal, ni de los riesgos físicos o materiales de ellas derivadas.

AEMET. Se autoriza la reproducción de su contenido citando la fuente.