Samstag 04.04.2026

Aktualisiert am 04.04.2026 um 08:00

Vormittag

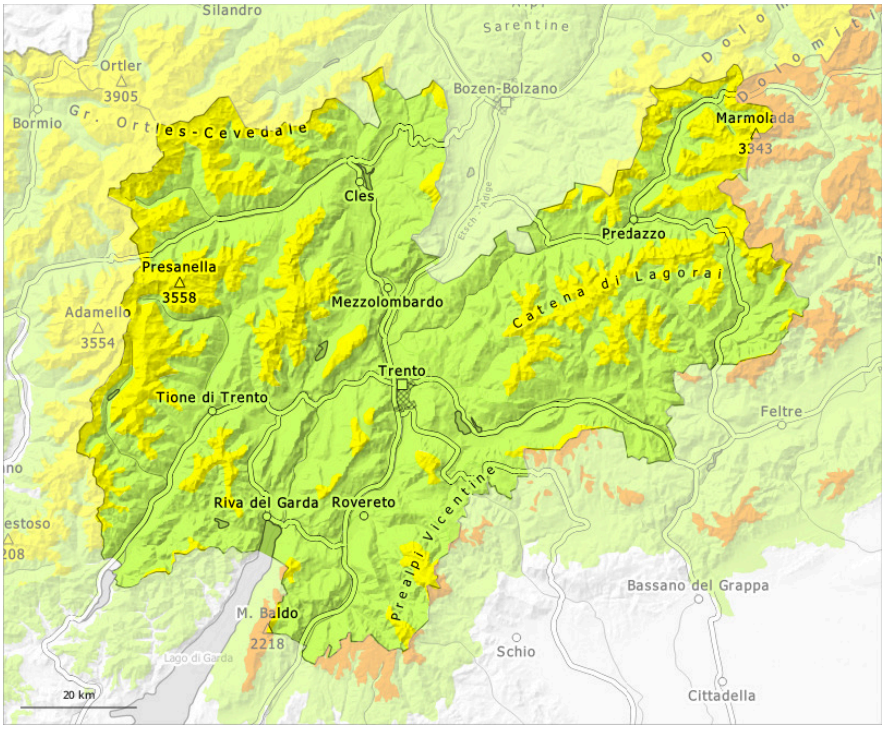

Nachmittag

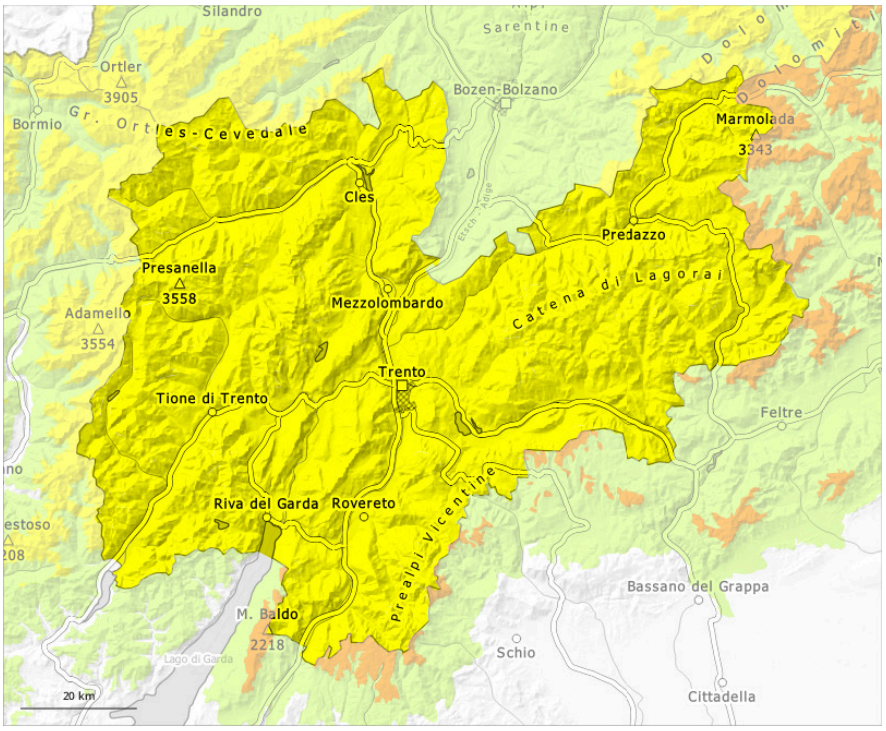

1	2	3	4	5
gering	mäßig	erheblich	groß	sehr groß

Samstag 04.04.2026

Aktualisiert am 04.04.2026 um 08:00

Gefahrenstufe 2 - Mäßig

AM:

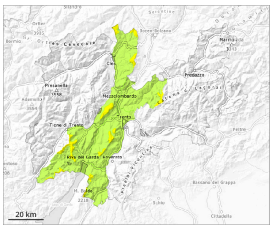

Waldgrenze

Tendenz: Lawinengefahr bleibt gleich
am Sonntag, den 05.04.2026

Triebschnee

Waldgrenze

PM:

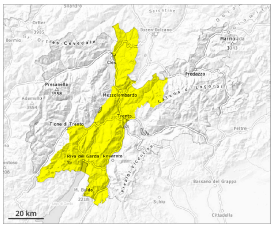

Tendenz: Lawinengefahr bleibt gleich
am Sonntag, den 05.04.2026

Triebschnee

Waldgrenze

Nassschnee

2500m

Triebschnee ist die Hauptgefahr.

Die frischeren Triebschneeansammlungen bilden die Hauptgefahr. Lawinen können bis auf den Boden durchreißen und mittlere Größe erreichen. Anstieg der Gefahr von feuchten und nassen Rutschen mit der tageszeitlichen Erwärmung und der Sonneneinstrahlung.

Schneedecke

Gefahrenmuster gm.6: lockerer schnee und wind | gm.1: bodennahe schwachschicht

Mit starkem bis stürmischem Wind aus nördlichen Richtungen entstanden in den letzten Tagen v.a. in Rinnen, Mulden und hinter Geländekanten teils große Triebschneeansammlungen. Die frischen Triebschneeansammlungen liegen an allen Expositionen und allgemein oberhalb der Waldgrenze auf einer ungünstigen Altschneeoberfläche.
Sonne und Wärme führen im Tagesverlauf unterhalb von rund 2500 m zu einer Anfeuchtung der Schneedecke.

Tendenz

Samstag: Die Lawinengefahr bleibt bestehen.

Gefahrenstufe 2 - Mäßig

AM:

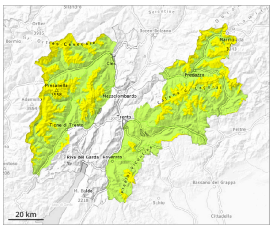

Waldgrenze

Tendenz: Lawinengefahr bleibt gleich
am Sonntag, den 05.04.2026

Triebschnee

Waldgrenze

Altschnee

Waldgrenze

PM:

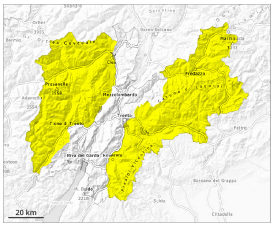

Tendenz: Lawinengefahr bleibt gleich
am Sonntag, den 05.04.2026

Triebschnee

Waldgrenze

Altschnee

Waldgrenze

Nassschnee

2500m

Vorsicht vor Triebschnee und schwachem Altschnee.

Lawinen können vor allem mit großer Belastung ausgelöst werden. Dies vor allem oberhalb der Waldgrenze sowie an Übergängen von wenig zu viel Schnee wie z.B. bei der Einfahrt in Rinnen und Mulden. In der Altschneedecke sind an sehr steilen Schattenhängen heikle Schwachschichten vorhanden. Diese Gefahrenstellen liegen vor allem an den Expositionen Ost über Nord bis West. Besonders in Kammlagen, Rinnen und Mulden sind mittlere und vereinzelt große Lawinen möglich.
Anstieg der Gefahr von feuchten und nassen Rutschen mit der tageszeitlichen Erwärmung und der Sonneneinstrahlung.

Schneedecke

Gefahrenmuster gm.6: lockerer schnee und wind | gm.1: bodennahe schwachschicht

Der teilweise stürmische Wind hat Schnee verfrachtet. Mit starkem bis stürmischem Wind aus nördlichen Richtungen entstanden in den letzten Tagen v.a. in Rinnen, Mulden und hinter Geländekanten teils große Triebschneeansammlungen. Die frischen Triebschneeansammlungen liegen vor allem an den Expositionen

Ost über Nord bis West und allgemein oberhalb der Waldgrenze auf einer ungünstigen Altschneeoberfläche.
Die Sonneneinstrahlung führt im Tagesverlauf unterhalb von rund 2500 m zu einer Anfeuchtung der Schneedecke.

Tendenz

Samstag: Die Lawinengefahr bleibt bestehen.