Samedi 04.04.2026

Update du 04 04 2026, 08:00

Matin

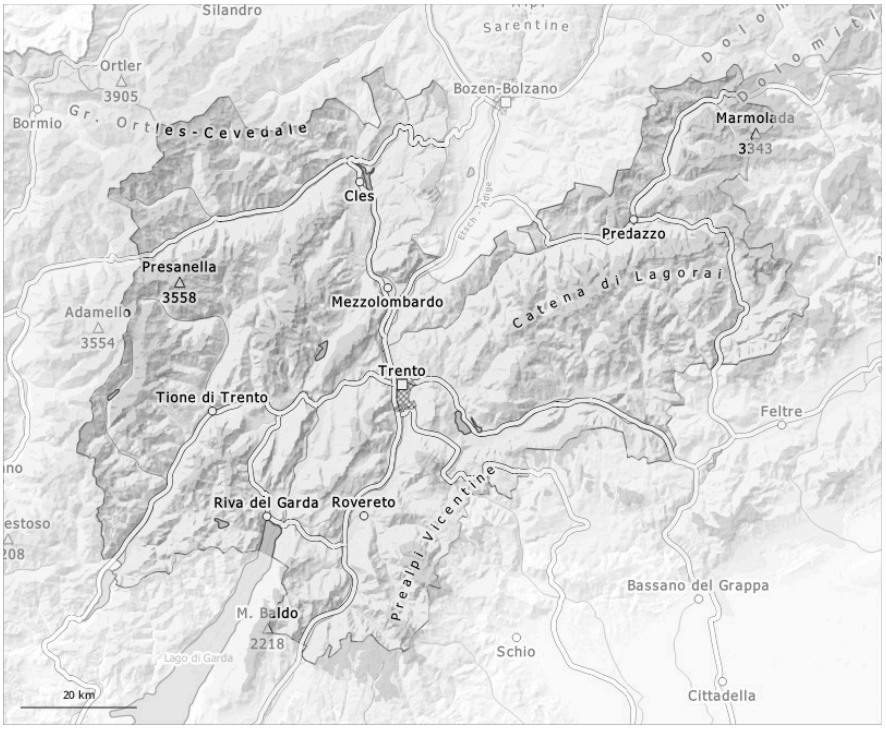

Après-midi

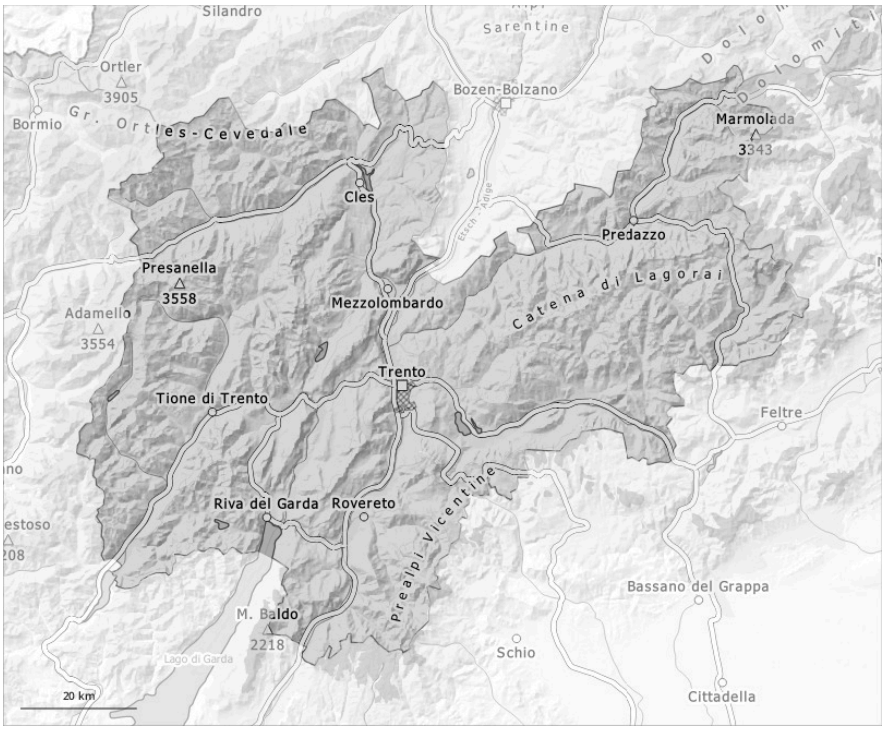

1	2	3	4	5
faible	limité	marqué	fort	très fort

Degré de danger 2 - Limité

AM:

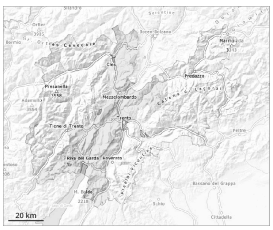

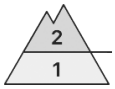

Limite de la forêt

Tendance: danger d'avalanche constant
leDimanche 05 04 2026

Neige soufflée
(Neige ventée)

Limite de la forêt

PM:

Tendance: danger d'avalanche constant
leDimanche 05 04 2026

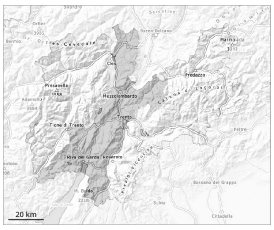

Neige soufflée
(Neige ventée)

Limite de la forêt

Avalanches
mouillées
(Neige
humide)

2500m

Neige soufflée constituant le danger principal.

Les accumulations plus récentes de neige soufflée constituent le danger principal. Des avalanches peuvent entraîner le manteau jusqu'au sol et atteindre une taille moyenne. Augmentation du danger de coulées humides et mouillées avec le réchauffement diurne et le rayonnement solaire.

Manteau neigeux

Modèles de danger md.6: froid, neige légère et vent | md.1: sous-couche fragile persistante

Des accumulations de neige soufflée en partie grandes se sont formées avec le vent de secteur nord fort à tempétueux dans les derniers jours surtout dans les combes, couloirs et derrière les ruptures de terrain. Les accumulations récentes de neige soufflée reposent sur une surface de neige ancienne défavorable à toutes les expositions et en général au-dessus de la limite de la forêt.
Le soleil et la chaleur entraînent en cours de journée en dessous d'environ 2500 m une humidification du manteau neigeux.

Tendance

Samedi: Le danger d'avalanches subsiste.

Degré de danger 2 - Limité

AM:

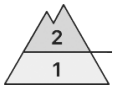

Limite de la forêt

Tendance: danger d'avalanche constant
leDimanche 05 04 2026

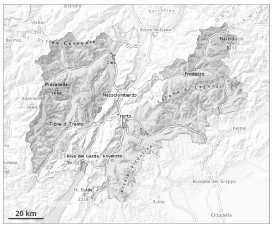

Neige soufflée (Neige ventée)

Limite de la forêt

Neige ancienne (Sous-couche fragile persistante)

Limite de la forêt

PM:

Tendance: danger d'avalanche constant
leDimanche 05 04 2026

Neige soufflée (Neige ventée)

Limite de la forêt

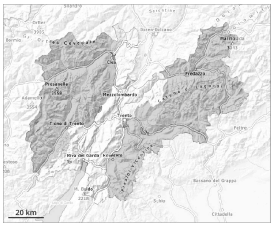

Neige ancienne (Sous-couche fragile persistante)

Limite de la forêt

Avalanches mouillées (Neige humide)

2500m

Attention à la neige soufflée et neige ancienne fragile.

Des avalanches peuvent être déclenchées surtout avec une surcharge importante. Ceci surtout au-dessus de la limite de la forêt comme aux transitions entre les endroits peu enneigés et les endroits très enneigés, notamment à l'entrée des combes et des couloirs.
Dans le manteau neigeux ancien des couches fragiles délicates sont présentes sur les pentes très raides à

l'ombre. Ces endroits dangereux se trouvent surtout aux expositions est à ouest en passant par le nord.
Des avalanches de moyenne et rarement grande taille sont possibles spécialement à proximité des crêtes, dans les combes et couloirs.
Augmentation du danger de coulées humides et mouillées avec le réchauffement diurne et le rayonnement solaire.

Manteau neigeux

Modèles de danger md.6: froid, neige légère et vent md.1: sous-couche fragile persistante

Le vent parfois tempétueux a transporté de la neige. Des accumulations de neige soufflée en partie grandes se sont formées avec le vent de secteur nord fort à tempétueux dans les derniers jours surtout dans les combes, couloirs et derrière les ruptures de terrain. Les accumulations récentes de neige soufflée reposent sur une surface de neige ancienne défavorable surtout sur les pentes exposées à l'est à ouest en passant par le nord et en général au-dessus de la limite de la forêt.
Le rayonnement solaire en cours de journée entraîne en dessous d'environ 2500 m une humidification du manteau neigeux.

Tendance

Samedi: Le danger d'avalanches subsiste.