ICGC Institut Cartogràfic i Geològic de Catalunya

Servei Meteorològic de Catalunya meteo.cat

Boletín de peligro de aludes para el Pirineo de Catalunya
Del 04/04/2026 al 07/04/2026

(Válido fuera pistas de esquí y zonas no controladas)

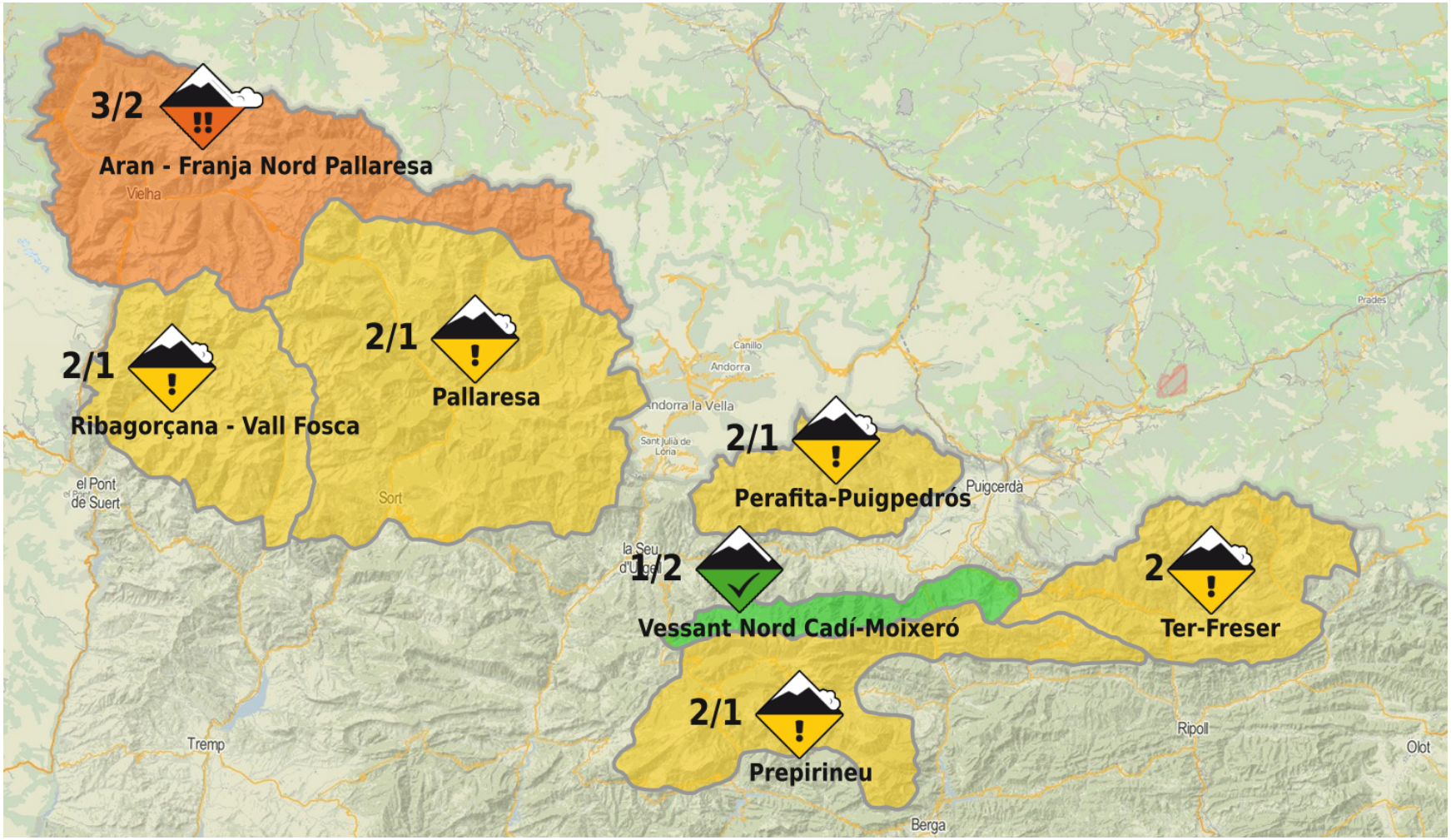

5 MUY FUERTE	4 FUERTE	3 NOTABLE	2 LIMITADO	1 DÉBIL

ICGC Institut Cartogràfic i Geològic de Catalunya

Servei Meteorològic de Catalunya meteo.cat

Boletín de peligro de aludes Aran - Franja Nord Pallaresa Del 04/04/2026 al 07/04/2026

(Válido fuera pistas de esquí y zonas no controladas)

NOTABLE (3) por encima de 2.200 m.
LIMITADO (2) por debajo.

Situación primaria

Capas débiles persistentes

Distribución

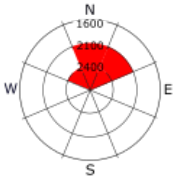

Tamaño

Origen

Tendencia

Situación secundaria

Nieve húmeda

Distribución

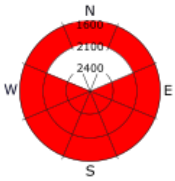

Tamaño

Origen

Tendencia

Estado del manto nivoso

En los últimos días ha habido varios aludes accidentales, de tamaños 2 y 3 (suficiente para enterrar a un grupo de personas) en forma de placas blandas por encima de niveles débiles persistentes. Los aludes accidentales siguen siendo probables por encima de 2.200 m en terreno umbrío, incluso por sobrecarga débil. Allí donde encontramos la nieve ligeramente placada, aunque superficialmente haya humedecido ligeramente, los desencadenamientos serán todavía posibles, en especial en Aran. Además se espera que el manto humedece superficialmente y, a lo largo de la jornada, haya aludes de nieve húmeda de tamaños 1 y 2 (suficiente para enterrar a una persona). Serán más frecuentes en las cotas más bajas y en el terreno más soleado, cerca de puntos oscuros como rocas y árboles. También se espera la caída natural de deslizamientos basales de tamaño 2 en terreno propicio.

Distribución del manto nivoso

Los espesores a unos 2.200 m son ligeramente superiores a los normales en la Franja Norte de la Pallaresa y en la mitad sur de Arán, donde rondan los 200-240 cm. En la mitad norte de Arán son los normales por estas fechas con unos 150-170 cm de espesor total.

Tendencia para las próximas 48-72h

Continuará predominando el problema de nieve húmeda, así como los deslizamientos basales, que en terreno propicio irán tomando protagonismo. Peligro ESTACIONARIO.

El próximo boletín será emitido el día 2026-04-07

5 MUY FUERTE	4 FUERTE	3 NOTABLE	2 LIMITADO	1 DÉBIL

EAWS EUROPEAN AVALANCHE WARNING SERVICES

ICGC Institut Cartogràfic i Geològic de Catalunya

Servei Meteorològic de Catalunya

Boletín de peligro de aludes Ribagorçana - Vall Fosca Del 04/04/2026 al 07/04/2026

(Válido fuera pistas de esquí y zonas no controladas)

LIMITADO (2) por encima de 2.200 m y durante las horas de sol. DÉBIL (1) el resto.

Situación primaria

Nieve húmeda

Distribución

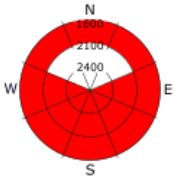

Tamaño

Origen

Tendencia

Situación secundaria

Nieve venteada

Distribución

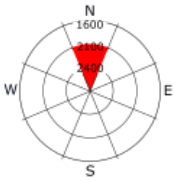

Tamaño

Origen

Tendencia

Estado del manto nivoso

En gran parte del terreno la nieve presenta un comportamiento primaveral. A primera hora se encuentra encostrado, pero irá transformando por la insolación y las temperaturas elevadas. Se esperan purgas de nieve húmeda en terreno inclinado, especialmente alrededor de puntos oscuros y afectando a las capas de nieve más superficiales. En terreno muy umbrío los aludes de nieve húmeda no serán probables. Además, en el norte del sector actualmente existen placas de viento en lugares resguardados de todas las orientaciones. Se trata de acumulaciones locales y que pueden desprenderse al paso de personas. Las más sensibles se encuentran entre 2.200 y 2.500 m, aproximadamente, en terreno umbrío y en los sectores más cercanos a la divisoria. En caso de caer, los aludes podrán alcanzar tamaño 2 (suficiente para enterrar a una persona) en lugares resguardados del viento. El lunes y el martes los desencadenamientos serán menos probables.

Distribución del manto nivoso

La nieve se continúa a partir de 1.700 ma terreno umbrío y de 1.900 ma solanas. Los grosores alcanzan los 100-120 cm a unos 2.200 m, con frecuentes deflaciones y acumulaciones por encima del nivel del bosque. Estos valores se acercan a los normales para la época.

Tendencia para las próximas 48-72h

Se espera que el problema de nieve húmeda sea el más importante. Peligro EN DESCENSO.

El próximo boletín será emitido el día 2026-04-07

5 MUY FUERTE	4 FUERTE	3 NOTABLE	2 LIMITADO	1 DÉBIL

EAWS EUROPEAN AVALANCHE WARNING SERVICES

ICGC Institut Cartogràfic i Geològic de Catalunya

Servei Meteorològic de Catalunya

Boletín de peligro de aludes Pallaresa
Del 04/04/2026 al 07/04/2026

(Válido fuera pistas de esquí y zonas no controladas)

LIMITADO (2) por encima de 2.200 m y durante las horas de sol. DÉBIL (1) el resto.

Situación primaria

Nieve húmeda

Distribución

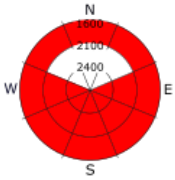

Tamaño

Origen

Tendencia

Situación secundaria

Nieve venteada

Distribución

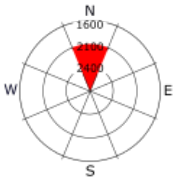

Tamaño

Origen

Tendencia

Estado del manto nivoso

En gran parte del terreno la nieve presenta un comportamiento primaveral. A primera hora se encuentra encostrado, pero irá transformando por la insolación y las temperaturas elevadas. Se esperan purgas de nieve húmeda en terreno inclinado, especialmente alrededor de puntos oscuros y afectando a las capas de nieve más superficiales. En terreno muy umbrío los aludes de nieve húmeda no serán probables. Además, en el norte del sector actualmente existen placas de viento en lugares resguardados de todas las orientaciones. Se trata de acumulaciones locales y que pueden desprenderse al paso de personas. Las más sensibles se encuentran entre 2.200 y 2.500 m, aproximadamente, en terreno umbrío y en los sectores más cercanos a la divisoria. En caso de caer, los aludes podrán alcanzar tamaño 2 (suficiente para enterrar a una persona) en lugares resguardados del viento. El lunes y el martes los desencadenamientos serán menos probables.

Distribución del manto nivoso

La nieve presenta cierta continuidad por encima de 1.700 ma terreno umbrío y de 1.900 ma solanas. Los espesores alcanzan los 110-150 cm en cotas medias, con frecuentes acumulaciones y deflaciones por encima del nivel del bosque.

Tendencia para las próximas 48-72h

Se espera que el problema de nieve húmeda sea el más importante. Peligro EN DESCENSO.

El próximo boletín será emitido el día 2026-04-07

5 MUY FUERTE	4 FUERTE	3 NOTABLE	2 LIMITADO	1 DÉBIL

EAWS EUROPEAN AVALANCHE WARNING SERVICES

ICGC Institut Cartogràfic i Geològic de Catalunya

Servei Meteorològic de Catalunya meteo.cat

Boletín de peligro de aludes Perafita-Puigpedrós Del 04/04/2026 al 07/04/2026

(Válido fuera pistas de esquí y zonas no controladas)

LIMITADO (2) por encima de 2.200 m y durante las horas de sol. DÉBIL (1) el resto.

Situación primaria

Nieve húmeda

Distribución

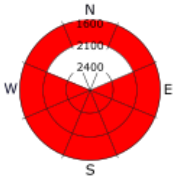

Tamaño

Origen

Tendencia

Situación secundaria

Nieve venteada

Distribución

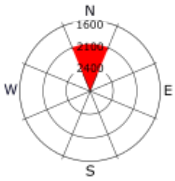

Tamaño

Origen

Tendencia

Estado del manto nivoso

El manto se presenta húmedo durante las horas diurnas y se enfría y regela a lo largo de la noche. Podrán caer purgas de nieve húmeda en terreno inclinado, especialmente alrededor de puntos oscuros y afectando principalmente a la nieve de los últimos episodios. El terreno elevado y umbría será el menos afectado por estos aludes. Hay que evitar el terreno donde la penetración de la bota o el esquí sean profundas, o el similar en el que encontramos actividad de aludes presente. Además, actualmente existen placas de viento en lugares protegidos de todas las orientaciones. Se trata de acumulaciones locales, y que se pueden desprender al paso de un grupo de personas en terreno umbrío entre unos 2.200 y 2.500 m. En caso de caer, los aludes podrán alcanzar tamaño 2 (suficiente para enterrar a una persona).

Distribución del manto nivoso

Hay nieve en el suelo con cierta continuidad por encima de unos 1.900 m en terreno umbrío, y de 2.200 m en solanas. Es esquiable a partir de unos 2.000 m en N. Los espesores, aunque irregulares, rondan los 80-120 cm en umbrías, a 2.300 m; existen frecuentes deflaciones y acumulaciones por encima del nivel del bosque. Son grosores por encima de los habituales en esta época.

Tendencia para las próximas 48-72h

El humedecimiento durante las horas de máxima insolación seguirán siendo el principal elemento a tener en cuenta. Peligro EN DESCENSO.

El próximo boletín será emitido el día 2026-04-07

5 MUY FUERTE	4 FUERTE	3 NOTABLE	2 LIMITADO	1 DÉBIL

EAWS EUROPEAN AVALANCHE WARNING SERVICES

ICGC Institut Cartogràfic i Geològic de Catalunya

meteo.cat Servei Meteorològic de Catalunya

Boletín de peligro de aludes
Vessant Nord Cadí-Moixeró
Del 04/04/2026 al 07/04/2026

(Válido fuera pistas de esquí y zonas no controladas)

DÉBIL (1). LIMITADO (2) en momentos de máxima insolación.

Situación primaria

Nieve húmeda

Distribución

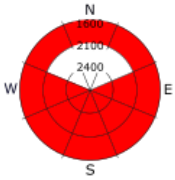

Tamaño

Origen

Tendencia

Situación secundaria

Capas débiles persistentes

Distribución

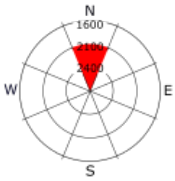

Tamaño

Origen

Tendencia

Estado del manto nivoso

Además, se espera que el sábado continúe el humedecimiento del manto debido a la insolación y al incremento de temperaturas. Podría haber aludes que afectarán sobre todo a la nieve más reciente, blanda y superficial, proveniente del episodio entre el martes y el miércoles. Los posibles aludes tendrán lugar en el terreno más soleado y serán por lo general de tamaño 1, suficiente para producir caídas y lesiones. Actualmente hay placas de viento, principalmente en el Moixeró, ya que en el Cadí las nevadas han sido muy escasas. Son placas que se pueden desencadenar al paso de un grupo de personas allí donde la nieve no haya humedecido suficientemente, es decir, a las umbrías más elevadas. En caso de desprenderse se tratará de aludes de tamaño 1, en su conjunto.

Distribución del manto nivoso

Podemos encontrar una delgada capa de nieve a 1.700 m por el último episodio de nevadas, pero en solanas el manto no es continuo hasta unos 1.900 m. Los grosores están alrededor de 160-180 cm a 2.200 m, con algunas acumulaciones y deflaciones por encima del nivel del bosque. Estos valores son muy excedentarios para la época del año.

Tendencia para las próximas 48-72h

Continuará el comportamiento primaveral del manto, con algunos aludes de fusión en momentos de insolación. Peligro EN DESCENSO.

El próximo boletín será emitido el día 2026-04-07

5 MUY FUERTE	4 FUERTE	3 NOTABLE	2 LIMITADO	1 DÉBIL

EAWS EUROPEAN AVALANCHE WARNING SERVICES

ICGC Institut Cartogràfic i Geològic de Catalunya

meteo.cat Servei Meteorològic de Catalunya

Boletín de peligro de aludes Prepirineu
Del 04/04/2026 al 07/04/2026

(Válido fuera pistas de esquí y zonas no controladas)

LIMITADO (2) por encima de 2.200 m durante las horas de sol. DÉBIL (1) el resto.

Situación primaria

Nieve húmeda

Distribución

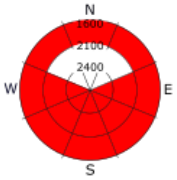

Tamaño

Origen

Tendencia

Estado del manto nivoso

Las condiciones son de primavera avanzada en el sector. El manto se presenta húmedo durante las horas diurnas y se enfría y regela a lo largo de la noche. Podrán caer purgas de nieve húmeda en terreno inclinado, especialmente alrededor de puntos oscuros y afectando principalmente a la nieve de los últimos episodios. El terreno elevado y umbría será el menos afectado por estos aludes. Internamente el manto se presenta todavía endurecido fuera del terreno más soleado, por lo que los aludes esperados son de tamaño 1 (suficiente para generar caídas y lesiones). Hay que evitar el terreno donde la penetración de la bota o el esquí sean profundas, o el similar en el que encontramos actividad de aludes presente.

Distribución del manto nivoso

Aunque podemos encontrar nieve en cotas más bajas por último episodio de nevadas, el manto es continuo por encima de unos 1.700 ma terreno umbrío y de unos 1.900 ma solanas. Los espesores, aunque irregulares, rondan los 90-120 cm a 2.300 m.

Tendencia para las próximas 48-72h

El humedecimiento durante las horas de máxima insolación seguirán siendo el principal elemento a tener en cuenta. Peligro EN DESCENSO.

El próximo boletín será emitido el día 2026-04-07

5 MUY FUERTE	4 FUERTE	3 NOTABLE	2 LIMITADO	1 DÉBIL

EAWS EUROPEAN AVALANCHE WARNING SERVICES

ICGC Institut Cartogràfic i Geològic de Catalunya

Servei Meteorològic de Catalunya

Boletín de peligro de aludes Ter-Freser
Del 04/04/2026 al 07/04/2026

(Válido fuera pistas de esquí y zonas no controladas)

LIMITADO (2) por encima de 2.200 m y durante las horas de sol. DÉBIL (1) el resto.

Situación primaria

Nieve húmeda

Distribución

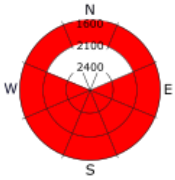

Tamaño

Origen

Tendencia

Situación secundaria

Capas débiles persistentes

Distribución

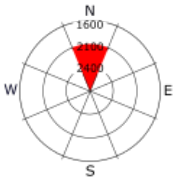

Tamaño

Origen

Tendencia

Estado del manto nivoso

El manto se presenta húmedo durante las horas diurnas y se enfría y regela a lo largo de la noche. Podrán caer purgas de nieve húmeda en terreno inclinado, especialmente alrededor de puntos oscuros y afectando principalmente a la nieve de los últimos episodios. El terreno elevado y umbría será el menos afectado por estos aludes. Hay que evitar el terreno donde la penetración de la bota o el esquí sean profundas, o el similar en el que encontramos actividad de aludes presente. En terreno muy umbrío la nieve de caída esta semana reposa a menudo sobre niveles de nieve granulada. Al paso de un grupo de personas se podrían desencadenar aludes de placa de hasta tamaño 2 (suficiente para enterrar a una persona). El manto es todavía sensible a estos desencadenamientos donde la nieve se encuentre seca y no encostrada, y serán improbables a partir del lunes.

Distribución del manto nivoso

El manto es esquiable a umbrías a partir de unos 1.800 m en umbrías. Los grosores son muy excedentarios para la época del año y en lugares no afectados por el viento oscilan entre 70-100 cm a unos 2.000 m, y más de 150 cm por encima de 2.400 m, muy variable por los efectos del viento.

Tendencia para las próximas 48-72h

El humedecimiento durante las horas de máxima insolación seguirán siendo el principal elemento a tener en cuenta. Peligro EN DESCENSO.

El próximo boletín será emitido el día 2026-04-07

5 MUY FUERTE	4 FUERTE	3 NOTABLE	2 LIMITADO	1 DÉBIL

EAWS EUROPEAN AVALANCHE WARNING SERVICES