BUTLLETÍ DEL PERILL D'ALLAUS DEL PRINCIPAT D'ANDORRA

Servei meteorològic nacional
Principat d'Andorra

Elaborat el 04/04/2026 16:00
Propera actualització 05/04/2026 a les 16h

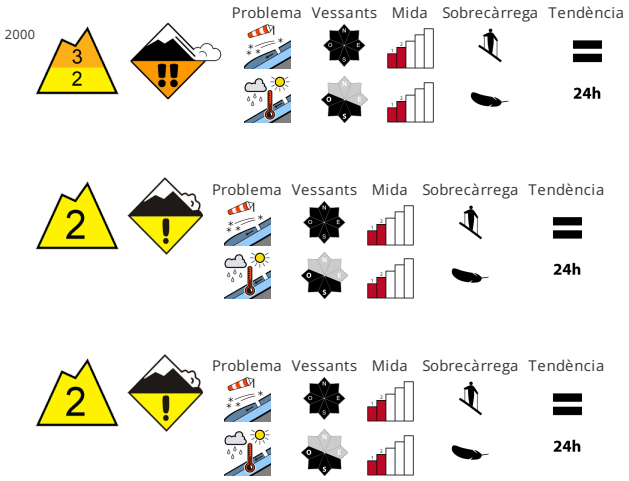

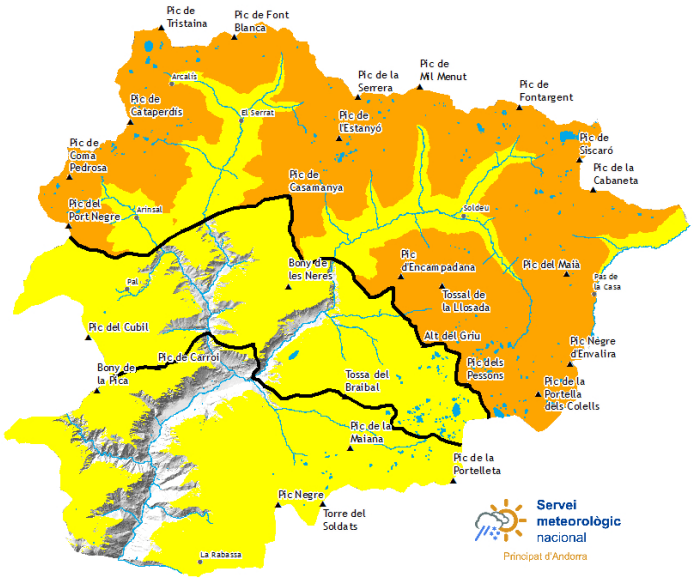

ESTABILITAT DEL MANTELL NIVAL

La neu recent abundant i les plaques de vent poden fàcilment desencadenar-se de manera natural o accidental. Les allaus són sovint de mida mitjana. Els indrets perillosos són força freqüents i difícils de reconèixer. A conseqüència de l'augment de la temperatura diürna i la radiació solar, en el transcurs de la jornada són possibles allaus de neu seca i humida, fins i tot de mida mitjana. Les excursions de muntanya i les activitats forapista requereixen experiència en l'avaluació del perill d'allaus i precaució.

QUALITAT DE LA NEU

Les noves acumulacions de neu ventada descansen a sobre de capes toves. El mantell de neu roman extremadament variable en pocs metres de manera generalitzada. Prop de les carenes els gruixos de neu varien molt per la influència del vent. El temps serà assolellat. Amb la pujada de temperatures la radiació solar, durant els propers dies el mantell de neu s'assentarà.

GRUIXOS DEL MANTELL NIVAL FORA DE PISTA

Zona nord		Gruix neu		
Mantell Nival		1500m	2000m	2500m
N	1300 m	20 cm	180 cm	250 cm
S	1300 m	10 cm	150 cm	200 cm

Zona centre		Gruix neu		
Mantell Nival		1500m	2000m	2500m
N	1300 m	10 cm	150 cm	200 cm
S	1500 m	5 cm	100 cm	150 cm

Zona sud		Gruix neu		
Mantell Nival		1500m	2000m	2500m
N	1300 m	10 cm	120 cm	160 cm
S	1500 m	5 cm	60 cm	120 cm

Govern d'Andorra

EAWS EUROPEAN AVALANCHE WARNING SERVICES

Aquest butlletí ha estat elaborat seguint les normes i recomanacions de l'**European Avalanche Warning Services**, del qual el **Servei meteorològic Nacional** n'és membre

BUTLLETÍ DEL PERILL D'ALLAUS DEL PRINCIPAT D'ANDORRA

Servei meteorològic nacional
Principat d'Andorra

Informació detallada per espais naturals protegits

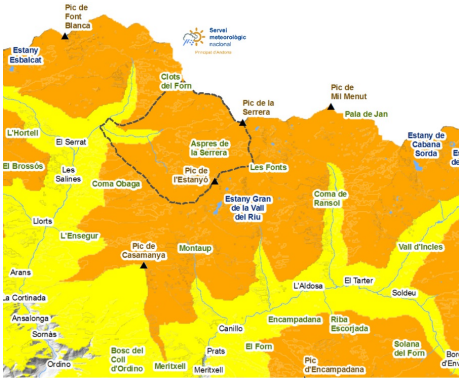

SORTENY

A causa de les nevades successives que sobretot han afectat el nord d´Andorra trobem condicions hivernals. A l´interior del bosc la possibilitat de desencadenament d´allaus és baixa, però a les parets verticals dels circs podem desencadenar allaus de placa. Haurem de fer una elecció acurada de l´itinerari.

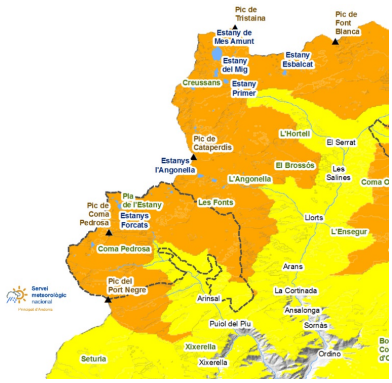

COMAPEDROSA

A la part superficial dem mantell trobem plaques de vent, ocultes sota la neu recent de mitja setmana i difícilment identificables. Atès que bona part del terreny del Parc és complex o exigent, les condicions són delicades per les excursions amb esquís i raquetes de neu.

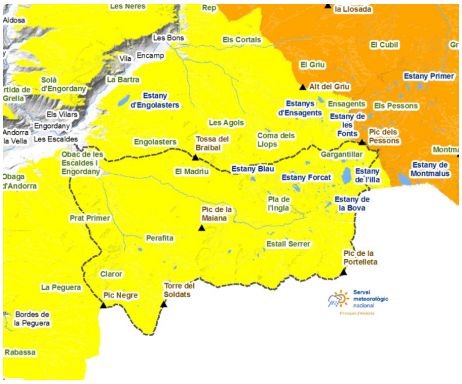

MADRIU-PERAFITA-CLAROR

La neu ha tornat a totes les cotes de la vall, però recularà ràpid de les cotes baixes. A cotes altes l´ambient encara és hivernal. Haurem de circular amb molta precaució, mantenint la distància de seguretat.

Govern d'Andorra

EAWS
EUROPEAN AVALANCHE WARNING SERVICES

Aquest butlletí ha estat elaborat seguint les normes i recomanacions de l'**European Avalanche Warning Services**, del qual el **Servei meteorològic Nacional** n'és membre

BUTLLETÍ DEL PERILL D'ALLAUS DEL PRINCIPAT D'ANDORRA

Servei meteorològic nacional
Principat d'Andorra

Gruixos de neu nova dels darrers dies (de les últimes 24h mesurat a les 06:00h UTC)

	31/03/2026	01/04/2026	02/04/2026	03/04/2026
FEDA (Central)	0 cm	0 cm	0 cm	0 cm
Engolasters - FEDA	0 cm	7 cm	0 cm	0 cm
Bony de les Neres	3 cm	22 cm	0 cm	0 cm
Les Fonts d'Arinsal	1 cm	22 cm	0 cm	0 cm
Perafita	6 cm	17 cm	30 cm	0 cm
Tossa Espiolets	0 cm	12 cm	27 cm	0 cm
Grau Roig - FEDA	7 cm	34 cm	0 cm	0 cm
Fontverd	0 cm	27 cm	0 cm	0 cm
Coll Ordino	4 cm	18 cm	0 cm	0 cm
Ransol - FEDA	6 cm	20 cm	3 cm	0 cm
Setúria	0 cm	12 cm	4 cm	0 cm
Caborreu	1 cm	21 cm	1 cm	0 cm
La Solana	11 cm	44 cm	4 cm	0 cm
Coll Pa	7 cm	8 cm	7 cm	0 cm
Vall del Riu FEDA	5 cm	48 cm	13 cm	0 cm