BUTLLETÍ DEL PERILL D'ALLAUS DEL PRINCIPAT D'ANDORRA

Elaborado el 04/04/2026 16:00
Proxima actualización 05/04/2026 a las 16h

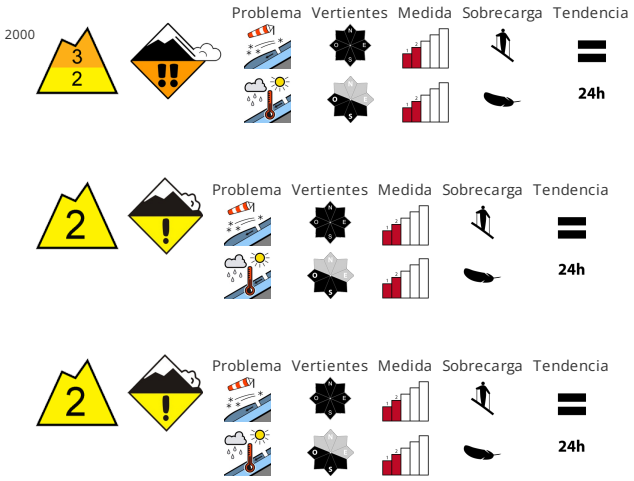

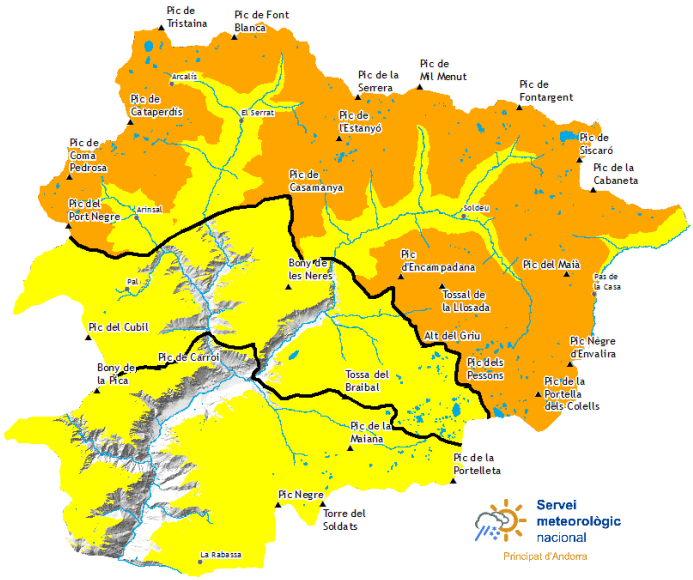

CALIDAD DE LA NIEVE

La nieve reciente abundante y las placas de viento pueden fácilmente desencadenarse de manera natural o accidental. Los aludes son a menudo de tamaño mediano. Los lugares peligrosos son bastante frecuentes y resultan difíciles de reconocer. A consecuencia del aumento de la temperatura diurna y la radiación solar, en el transcurso de la jornada son posibles avalanchas de nieve seca y húmeda, incluso de tamaño mediano. Las excursiones de montaña y las actividades fuera pista requieren experiencia en la evaluación del peligro de aludes y precaución.

ESTABILIDAD DEL MANTO NIVOSO

Las nuevas acumulaciones de nieve venteada descansan encima de capas blandas. El manto de nieve permanece extremadamente variable en pocos metros en general. Cerca de los cordales los espesores de nieve varían mucho por la influencia del viento. El tiempo será soleado. Con la subida de temperaturas la radiación solar, durante los próximos días el manto de nieve se asentará.

ESPESORES DEL MANTO NIVOSO FUERA DE PISTA

Zona norte		Espesor nieve		
Manto Nival		1500m	2000m	2500m
N	1300 m	20 cm	180 cm	250 cm
S	1300 m	10 cm	150 cm	200 cm

zona centro		Espesor nieve		
Manto Nival		1500m	2000m	2500m
N	1300 m	10 cm	150 cm	200 cm
S	1500 m	5 cm	100 cm	150 cm

Zona sur		Espesor nieve		
Manto Nival		1500m	2000m	2500m
N	1300 m	10 cm	120 cm	160 cm
S	1500 m	5 cm	60 cm	120 cm

Govern d'Andorra

Aquest butlletí ha estat elaborat seguint les normes i recomanacions de l'**European Avalanche Warning Services**, del qual el **Servei meteorològic Nacional** n'és membre

BUTLLETÍ DEL PERILL D'ALLAUS DEL PRINCIPAT D'ANDORRA

Servei meteorològic nacional
Principat d'Andorra

Información detallada por espacios naturales protegidos

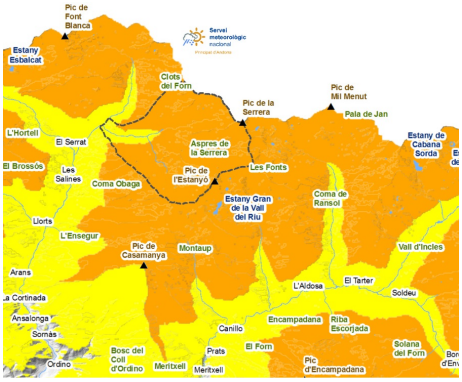

SORTENY

Debido a las sucesivas nevadas que sobre todo han afectado al norte de Andorra encontramos condiciones invernales. En el interior del bosque la posibilidad de desencadenamiento de aludes es baja, pero en las paredes verticales de los circos podemos desencadenar aludes de placa. Deberemos hacer una elección cuidadosa del itinerario.

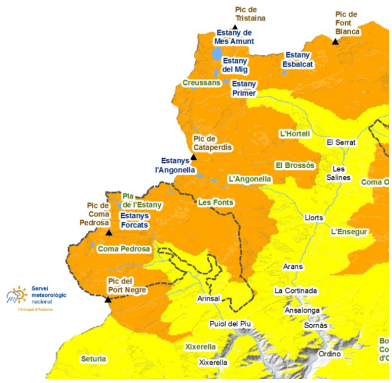

COMAPEDROSA

En la parte superficial del manto encontramos placas de viento, ocultas bajo la nieve reciente de media semana y difícilmente identificables. Dado que buena parte del terreno del Parque es complejo o exigente, las condiciones son delicadas por las excursiones en esquís y raquetas de nieve.

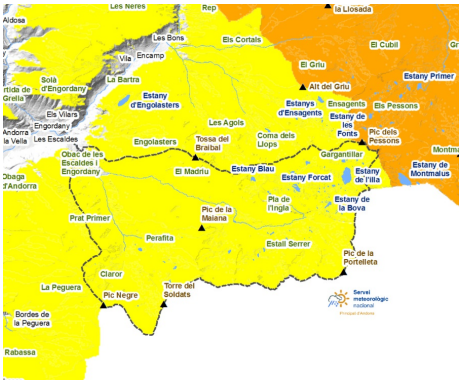

MADRIU-PERAFITA-CLAROR

La nieve ha vuelto a todas las cotas del valle, pero retrocederá rápido de las cotas bajas. En cotas altas el ambiente es aún invernal. Deberemos circular con mucha precaución, manteniendo la distancia de seguridad.

Govern d'Andorra

EAWS
EUROPEAN AVALANCHE WARNING SERVICES

Aquest butlletí ha estat elaborat seguint les normes i recomanacions de l'**European Avalanche Warning Services**, del qual el **Servei meteorològic Nacional** n'és membre

BUTLLETÍ DEL PERILL D'ALLAUS DEL PRINCIPAT D'ANDORRA

Servei meteorològic nacional
Principat d'Andorra

Espesores de nieve nueva de los últimos días (de las ultimas 24h mesurado a las 06:00h UTC)

	31/03/2026	01/04/2026	02/04/2026	03/04/2026
FEDA (Central)	0 cm	0 cm	0 cm	0 cm
Engolasters - FEDA	0 cm	7 cm	0 cm	0 cm
Bony de les Neres	3 cm	22 cm	0 cm	0 cm
Les Fonts d'Arinsal	1 cm	22 cm	0 cm	0 cm
Perafita	6 cm	17 cm	30 cm	0 cm
Tossa Espiolets	0 cm	12 cm	27 cm	0 cm
Grau Roig - FEDA	7 cm	34 cm	0 cm	0 cm
Fontverd	0 cm	27 cm	0 cm	0 cm
Coll Ordino	4 cm	18 cm	0 cm	0 cm
Ransol - FEDA	6 cm	20 cm	3 cm	0 cm
Setúria	0 cm	12 cm	4 cm	0 cm
Caborreu	1 cm	21 cm	1 cm	0 cm
La Solana	11 cm	44 cm	4 cm	0 cm
Coll Pa	7 cm	8 cm	7 cm	0 cm
Vall del Riu FEDA	5 cm	48 cm	13 cm	0 cm