BUTLLETÍ DEL PERILL D'ALLAUS DEL PRINCIPAT D'ANDORRA

Préparé le 04/04/2026 16:00
Prochaine mise à jour le 05/04/2026 à 16h

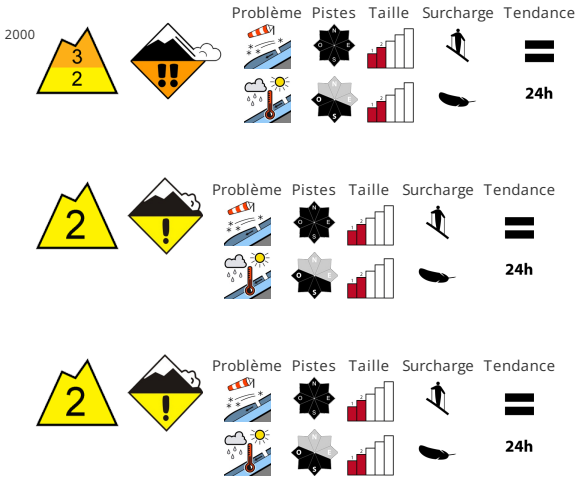

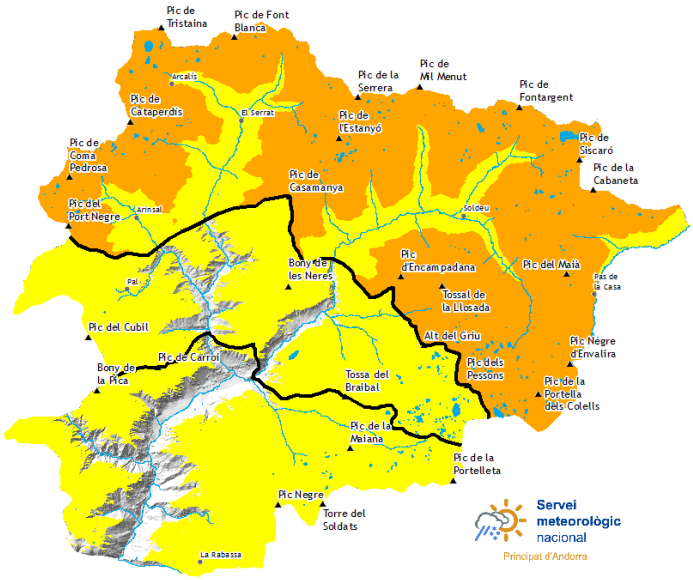

STABILITÉ DU MANTEAU NEIGEUX

La neige fraîche très abondante et les accumulations de neige soufflée peuvent être déclenchées facilement ou glisser spontanément. Les avalanches sont souvent de taille moyenne. Les endroits dangereux sont assez fréquents et difficilement identifiables.. Avec le réchauffement diurne et le rayonnement solaire en cours de journée des avalanches sèches et humides sont possibles ils sont , également de taille moyenne. Les randonnées et descentes hors-piste demandent de l' expérience dans l'évaluation du danger d'avalanche et de la retenue.

QUALITÈ DE LA NEIGE

Les accumulations récentes de neige soufflée reposent sur des couches meubles. De manière généralisée le manteau neigeux reste très variable à petite échelle.. À proximité des crêtes on trouve suivant l'influence du vent des hauteurs de neiges très différentes. Il fait un temps ensoleillé. Avec le réchauffement le rayonnement solaire le manteau neigeux se tasse dans les prochains jours.

EPAISSEUR DE NEIGE HORS PISTE

Zone nord		Epaisseur de neige		
Nival manteau		1500m	2000m	2500m
N	1300 m	20 cm	180 cm	250 cm
S	1300 m	10 cm	150 cm	200 cm

Zone centre		Epaisseur de neige		
Nival manteau		1500m	2000m	2500m
N	1300 m	10 cm	150 cm	200 cm
S	1500 m	5 cm	100 cm	150 cm

Zone sud		Epaisseur de neige		
Nival manteau		1500m	2000m	2500m
N	1300 m	10 cm	120 cm	160 cm
S	1500 m	5 cm	60 cm	120 cm

BUTLLETÍ DEL PERILL D'ALLAUS DEL PRINCIPAT D'ANDORRA

Servei meteorològic nacional
Principat d'Andorra

Des informations détaillées par espace naturel protégé

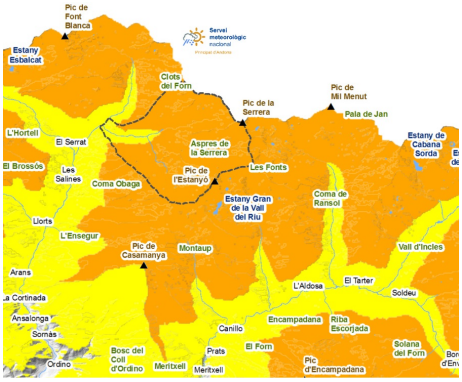

SORTENY

En raison des chutes de neige successives qui ont principalement touché le nord d'Andorre, nous retrouvons des conditions hivernales. A l'intérieur de la forêt, la possibilité de déclenchement d'avalanches est faible, mais sur les parois verticales des cirques, des avalanches de plaques peuvent se déclencher. Nous devrons faire un choix judicieux de l'itinéraire. , , , , ,

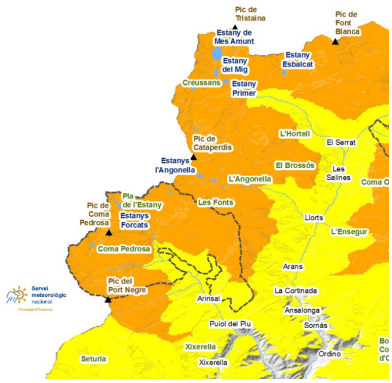

COMAPEDROSA

Dans la partie superficielle du manteau on trouve des plaques de vent, cachées sous la neige récente de milieu de semaine et difficiles à identifier. Étant donné qu'une grande partie du terrain du parc est complexe ou exigeant, les conditions sont délicates pour les excursions en ski et en raquettes. , , ,

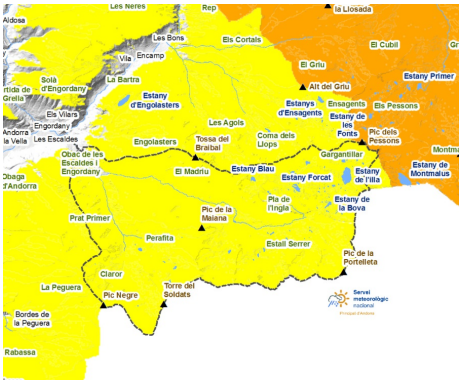

MADRIU-PERAFITA-CLAROR

La neige est revenue à toutes les altitudes de la vallée, mais reculera rapidement des altitudes inférieures. À haute altitude, l'atmosphère est encore hivernale. Nous devrons conduire très prudemment, en gardant une distance de sécurité. , , , , ,

Govern d'Andorra

EAWS
EUROPEAN AVALANCHE WARNING SERVICES

Aquest butlletí ha estat elaborat seguint les normes i recomanacions de l'**European Avalanche Warning Services**, del qual el **Servei meteorològic Nacional** n'és membre

BUTLLETÍ DEL PERILL D'ALLAUS DEL PRINCIPAT D'ANDORRA

Servei meteorològic nacional
Principat d'Andorra

Couche de neige fraiche des derniers jours (De 24 h mesurée à 06:00 h UTC)

	31/03/2026	01/04/2026	02/04/2026	03/04/2026
FEDA (Central)	0 cm	0 cm	0 cm	0 cm
Engolasters - FEDA	0 cm	7 cm	0 cm	0 cm
Bony de les Neres	3 cm	22 cm	0 cm	0 cm
Les Fonts d'Arinsal	1 cm	22 cm	0 cm	0 cm
Perafita	6 cm	17 cm	30 cm	0 cm
Tossa Espiolets	0 cm	12 cm	27 cm	0 cm
Grau Roig - FEDA	7 cm	34 cm	0 cm	0 cm
Fontverd	0 cm	27 cm	0 cm	0 cm
Coll Ordino	4 cm	18 cm	0 cm	0 cm
Ransol - FEDA	6 cm	20 cm	3 cm	0 cm
Setúria	0 cm	12 cm	4 cm	0 cm
Caborreu	1 cm	21 cm	1 cm	0 cm
La Solana	11 cm	44 cm	4 cm	0 cm
Coll Pa	7 cm	8 cm	7 cm	0 cm
Vall del Riu FEDA	5 cm	48 cm	13 cm	0 cm