Bulletin d'estimation du risque d'avalanche

(valable en dehors des pistes balisées et ouvertes)

MASSIF : Aravis

Rédigé le samedi 4 avril 2026 à 16h

Estimation des risques pour le : DIMANCHE 05 AVRIL

NEIGE HUMIDE DANS LES VERSANTS ENSOLEILLÉS ET DE RARES INSTABILITÉS (RARES PLAQUES À VENT) EN SECTEURS FROIDS

2

1 → 2

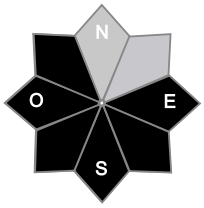

Indice de risque faible évoluant en limité.

Départs spontanés : Coulées humides au soleil, avalanches de fond

Déclenchements provoqués : Coulées de neige sous les skis, de rares plaques à vent dans les secteurs froids.

Indices de risque : 5 très fort - 4 fort - 3 marqué - 2 limité - 1 faible -- En noir : les pentes les plus dangereuses

Stabilité du manteau neigeux

Situation avalancheuse typique : neige humide — neige ventée

Départs spontanés :
* Coulées de neige humide en journée sous le soleil au fil de l'humidification. Les orientations concernées évoluent au fil de l'ensoleillement. Les pentes raides réagissent un peu plus rapidement. Taille 1 à 2.(petite à moyenne).
* À toute heure du jour et de la nuit, des fissures de reptations peuvent s'ouvrir et des avalanches de fond sont possibles sur les terrains lisses (pentes herbeuses, dalles rocheuses, ...). Taille 1 à 2.

Déclenchements provoqués :
* Coulées de neige humide sous les skis. Taille 1, 2.
* Au fil de l'humidification, ces plaques sont temporairement plus réactives, mais ne sont pas plus épaisses ni larges. Taille 1 voir 2.
* Rares plaques à vent encore présentes dans la neige récente et froide en altitude, elles sont peu réactives. Elles se sont formées sous la Bise des derniers jours. Ces plaques sont présentes principalement près des arêtes/crêtes, mais dans les secteurs les plus exposés, on peut en retrouver plus bas. Cassure de 20/40 cm, localement un peu plus. Taille 1 à 2.

Autre :
* Le redoux peut occasionner des chutes de corniches.

Qualité de la neige

Enneigement :
Bon pour un début avril. On peut chausser skis ou raquettes dès 1200/1300 m en versants N, et 1400/1600 m en versants S.

Qualité de la neige ce dimanche:
* Regel plutôt bon en matinée. En cours de journée, la neige s'humidifie dans un large sud/ouest.
* En nord, légère humidification en surface puis neige froide/ventée au-dessus de 2300 m environ. Encore des accumulations de neige plus importantes, ou au contraire, des zones dures voire ravagées par le vent. Les crêtes et sommets sont les plus ravagées par le vent.
* Nombreuses corniches et accumulations/congères.

Aperçu météo pour le dimanche 05 avril

Quelques nuages d'altitude dans la nuit et qui se poursuivent en journée. Le ciel se couvre en soirée. Chaud, 10°C à 2000 m.

	nuit	matin	après-midi	soir
Pluie-Neige				2 600 m
Iso 0 °C	3 100 m	2 900 m	2 800 m	2 800 m
Vent 2000 m	↑ 15 km/h	↗ 20 km/h	↗ 20 km/h	↗ 35 km/h
Vent 2500 m	↗ 20 km/h	↗ 30 km/h	↗ 30 km/h	↗ 45 km/h

Épaisseur de neige hors-piste

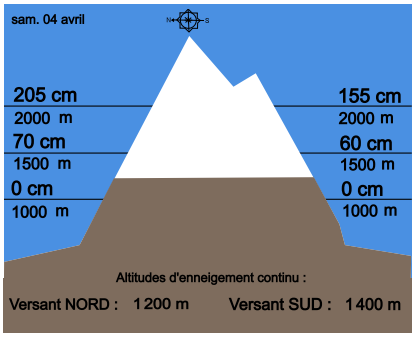

Précipitations à 1800 m

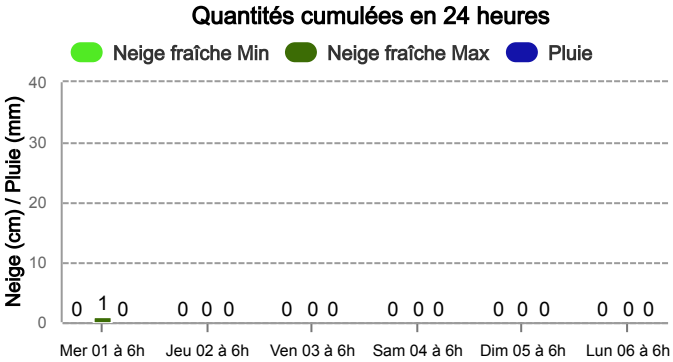

Tendance du lundi 06 avril

2

Indice de risque limité

L'humidification se poursuit et le mauvais regel en nuit de dimanche à lundi pourrait occasionner plus de coulées en neige humide.

Pour consulter la vigilance en cours, veuillez vous rendre sur le site https://vigilance.meteofrance.fr/fr

Météo-France - 73 avenue de Paris, 94165 Saint-Mandé cedex - Contact : contact@meteo.fr

Rédigé par Météo-France avec la contribution des observateurs du réseau nivo-météorologiques. Partenariat : ANMSM (Maires de Stations de Montagne), DSF (Domaines Skiables de France), ADSP (Directeurs de Pistes et de la Sécurité des Stations de Sports d'Hiver) et autres acteurs de la montagne.

Bulletin neige & avalanches par téléphone au 0 892 68 10 20 Service 0,35 € / min + prix appel

RÉPUBLIQUE FRANÇAISE
Liberté Égalité Fraternité

METEO FRANCE
À VOS CÔTÉS, DANS UN CLIMAT QUI CHANGE

Bulletin d'estimation du risque d'avalanche

(valable en dehors des pistes balisées et ouvertes)

MASSIF : Aravis

Rédigé le samedi 4 avril 2026 à 16h

Conditions nivo-météo des 7 derniers jours

	dim. 29/03				lun. 30/03				mar. 31/03				mer. 01/04				jeu. 02/04				ven. 03/04				sam. 04/04			
	03h	09h	15h	21h	03h	09h	15h	21h	03h	09h	15h	21h	03h	09h	15h	21h	03h	09h	15h	21h	03h	09h	15h	21h	03h	09h	15h	21h
Météo																												
Vent (km/h)	60	50	30	30	25	35	45	65	65	65	60	60	70	70	50	40	30	40	40	50	50	30	20	15	25	15	5	10
à 2500m																												
Vent (km/h)	50	30	20	20	10	20	35	40	45	40	45	40	40	35	35	20	20	20	30	30	20	20	15	5	15	10	0	5
à 2000m																												

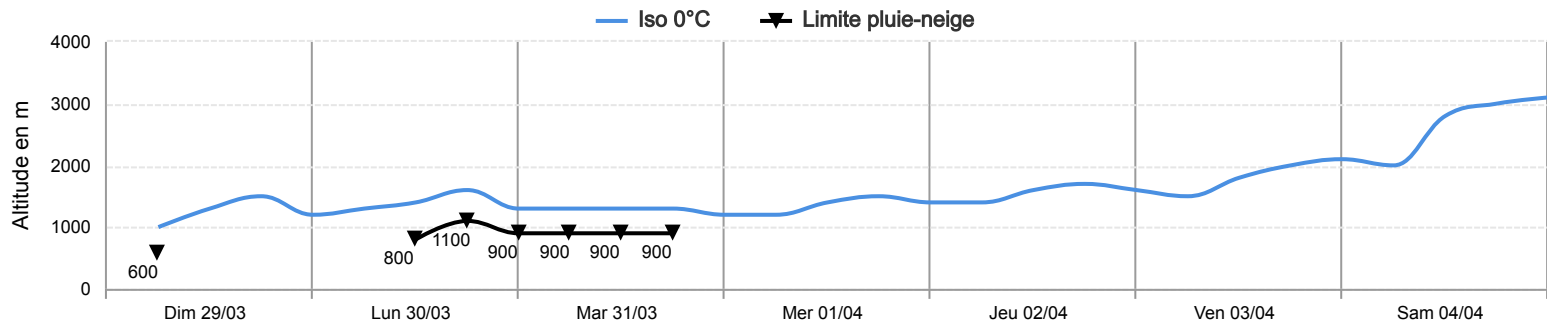

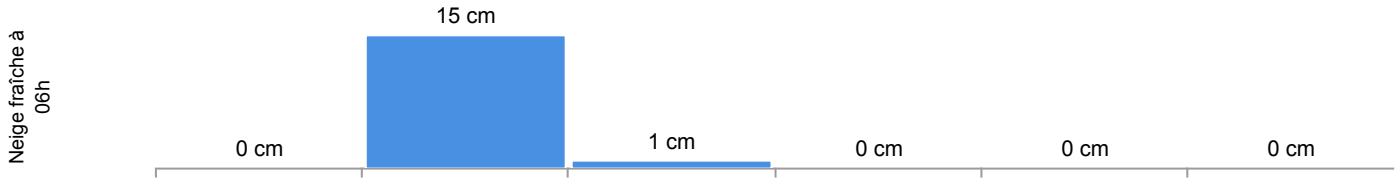

Risque d'avalanche	dim. 29/03	lun. 30/03	mar. 31/03	mer. 01/04	jeu. 02/04	ven. 03/04	sam. 04/04
	2	2	3	3	2	2	2

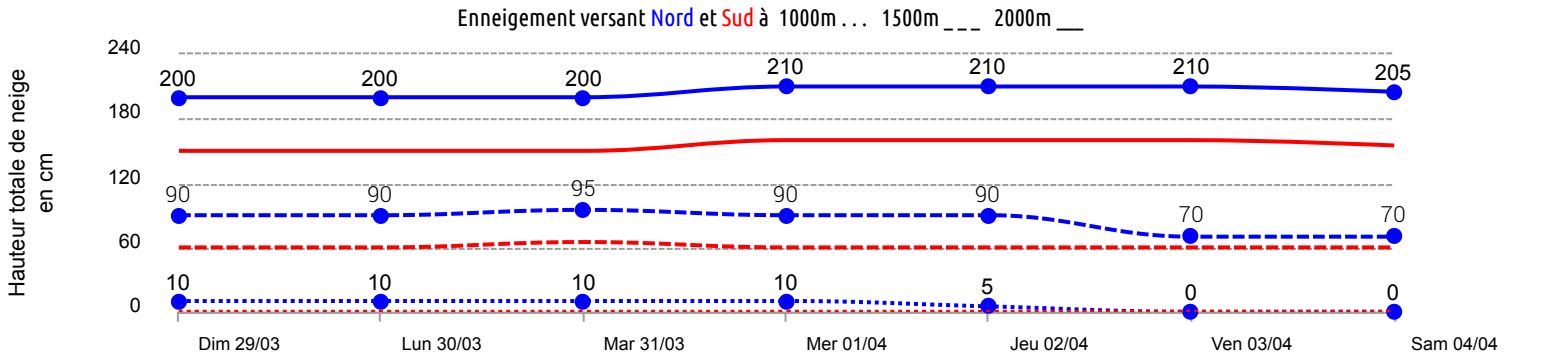

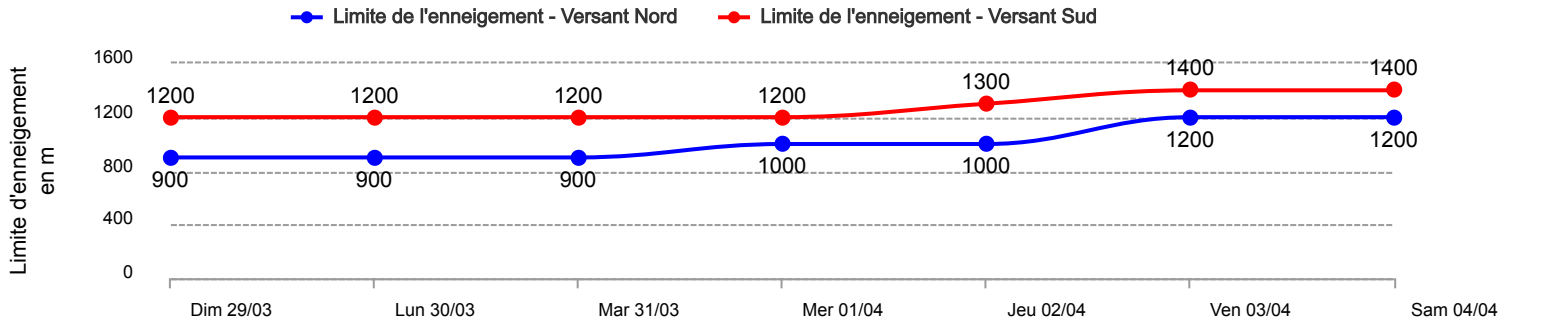

Pour consulter la vigilance en cours, veuillez vous rendre sur le site https://vigilance.meteofrance.fr/fr

Météo-France - 73 avenue de Paris, 94165 Saint-Mandé cedex - Contact : contact@meteo.fr

Rédigé par Météo-France avec la contribution des observateurs du réseau nivo-météorologiques. Partenariat : ANMSM (Maires de Stations de Montagne), DSF (Domaines Skiables de France), ADSP (Directeurs de Pistes et de la Sécurité des Stations de Sports d'Hiver) et autres acteurs de la montagne.

Bulletin neige & avalanches par téléphone au

0 892 68 10 20 Service 0,35 € / min + prix appel