Bulletin d'estimation du risque d'avalanche
(valable en dehors des pistes balisées et ouvertes)
MASSIF : Belledonne

Rédigé le samedi 4 avril 2026 à 16h

Estimation des risques pour le : DIMANCHE 05 AVRIL

REDOUX RAPIDE AU SOLEIL, QUELQUES NOUVELLES COULEES POSSIBLES, PARFOIS UNE AVALANCHE...

2

1 → 2

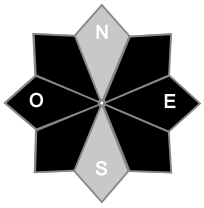

Humides/altitude

Indice de risque faible évoluant en limité.

Départs spontanés : Suivant la course du soleil, quelques nouvelles coulées/boules, parfois une avalanche en pentes raides/humidifiées (près des rochers), de taille 1 à 2. Dans un rare cas possible avalanche de fond, au terrain (taille 2 à 3) ?

Déclenchements provoqués : Rare plaque de surface en versant Nord-Ouest d'altitude. En pente bien humide, possible coulée ponctuelle sous les skis...

Indices de risque : 5 très fort - 4 fort - 3 marqué - 2 limité - 1 faible -- En noir : les pentes les plus dangereuses

Stabilité du manteau neigeux

Situation avalancheuse typique : neige humide — avalanches de fond

Un peu d'activité printanière suivant la course du soleil, et plus en altitude. En faces Nord de rares plaques. Attention aux surfaces durcies/regelées.

Départs spontanés :

Regel nocturne puis samedi le redoux sera net en versants ensoleillés et se produit davantage en altitude. Au fil de la journée et notamment près des rochers on peut s'attendre à quelques nouvelles coulées humides. En longue pente raide possible avalanche plus conséquente.

Une rupture spontanée de corniche n'est pas exclue, notamment sous 2500m environ...

Déclenchements provoqués :

En faces Nord d'altitude, la neige récente a été soufflée (bise de Nord-Est). Risque très résiduel de plaque de surface, parfois dure. Le travail du vent est les accumulations seraient assez visibles, prendre des distances...

En pentes soutenues et bien humidifiées (suivant la course du soleil), le skieur se méfiera d'un risque de coulée humide ponctuelle sous un virage, la neige plus récente pouvant glisser sur les sous-couches denses...

Autres : A l'ombre neige durcie par le regel, anciennes traces parfois lustrées. En pentes où le soleil est plus rasant des secteurs temporairement croutés et ski délicat....

Qualité de la neige

Qualification de l'enneigement : L'enneigement est très bon dès la moyenne montagne peu ensoleillée, et dans les combes d'altitude (ce qui est plus classique)... Fonte en bas du massif et en plein Sud...

Limites skiables : Vers 1100/1300m en plein Nord (hors sapins), 1500/1800m au soleil...

Qualité de la neige dimanche : En large Sud et sous 1800m, neige de plus en plus transformée, printanière... Regel nocturne modéré puis rapide humidification suivant la course du soleil. Humidification plus conséquente par rapport aux jours précédents...

Neige encore sèche en plein Nord au dessus de 2200m environ. Neige poudreuse dense (15/30 cm) ou bien cartonnée/durcie par la bise du début de semaine...

Aperçu météo pour le dimanche 05 avril

	nuit	matin	après-midi	soir

Ciel voilé durant la nuit de samedi à dimanche, regel modéré le matin. En journée soleil et nette douceur, digne d'un mois de mai !

Pluie-Neige				
Iso 0 °C	3 200 m	3 000 m	3 000 m	2 900 m
Vent 2000 m	← 10 km/h	↗ 10 km/h	↗ 25 km/h	↗ 15 km/h
Vent 3000 m	→ 15 km/h	↗ 20 km/h	→ 30 km/h	→ 25 km/h

Épaisseur de neige hors-piste

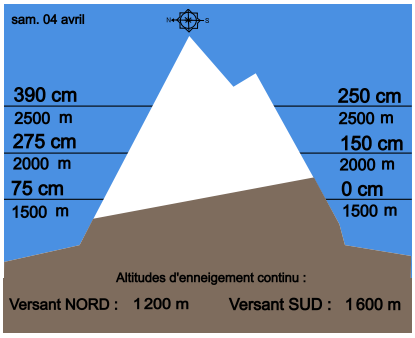

Précipitations à 1800 m

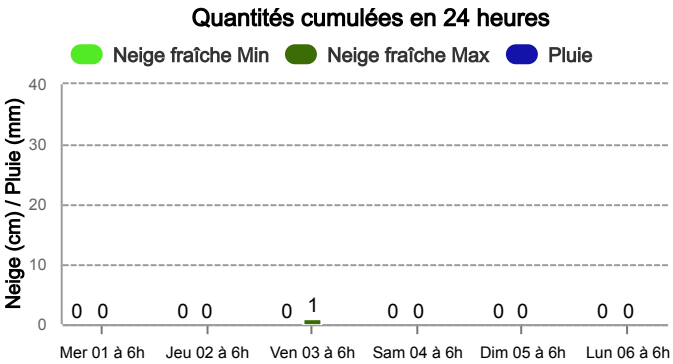

Tendance du lundi 06 avril

3

Indice de risque marqué

Risque d'avalanches humides plutôt en hausse lundi, notamment en faces Nord sous 2200 voire 2400m : Nuit de dimanche à lundi nuageuse, guère de regel a priori

Pour consulter la vigilance en cours, veuillez vous rendre sur le site https://vigilance.meteofrance.fr/fr

Météo-France - 73 avenue de Paris, 94165 Saint-Mandé cedex - Contact : contact@meteo.fr

Rédigé par Météo-France avec la contribution des observateurs du réseau nivo-météorologiques. Partenariat : ANMSM (Maires de Stations de Montagne), DSF (Domaines Skiables de France), ADSP (Directeurs de Pistes et de la Sécurité des Stations de Sports d'Hiver) et autres acteurs de la montagne.

Bulletin neige & avalanches par téléphone au 0 892 68 10 20 Service 0,35 € / min + prix appel

RÉPUBLIQUE FRANÇAISE
Liberté Égalité Fraternité

METEO FRANCE
À VOS CÔTÉS, DANS UN CLIMAT QUI CHANGE

Bulletin d'estimation du risque d'avalanche

(valable en dehors des pistes balisées et ouvertes)

MASSIF : Belledonne

Rédigé le samedi 4 avril 2026 à 16h

Conditions nivo-météo des 7 derniers jours

	dim. 29/03				lun. 30/03				mar. 31/03				mer. 01/04				jeu. 02/04				ven. 03/04				sam. 04/04			
	03h	09h	15h	21h	03h	09h	15h	21h	03h	09h	15h	21h	03h	09h	15h	21h	03h	09h	15h	21h	03h	09h	15h	21h	03h	09h	15h	21h
Météo																												
Vent (km/h)	45	35	20	25	40	60	70	85	90	100	100	70	65	55	25	30	35	55	55	55	50	45	40	30	35	25	10	5
à 3000m																												
Vent (km/h)	40	25	15	20	30	50	60	65	60	60	60	35	25	15	30	10	15	25	30	20	25	30	15	15	15	15	10	10
à 2000m																												

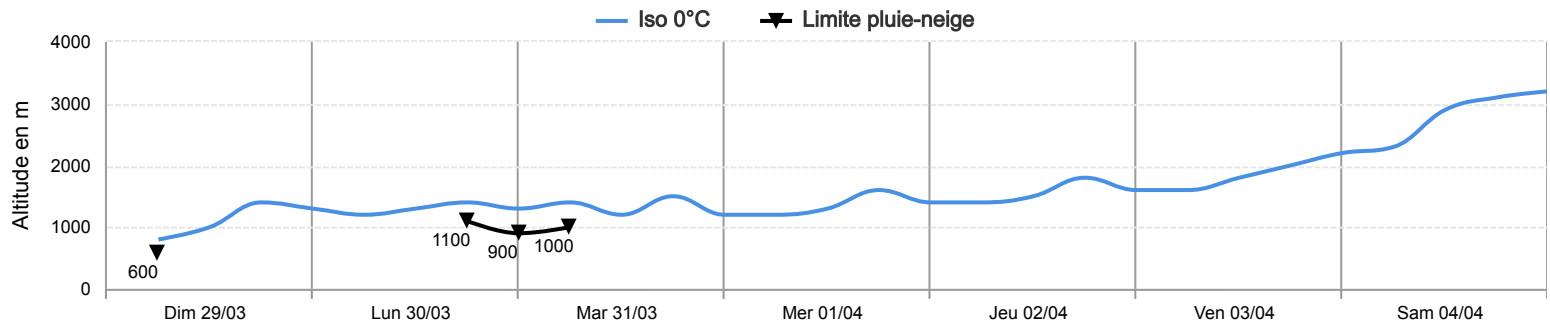

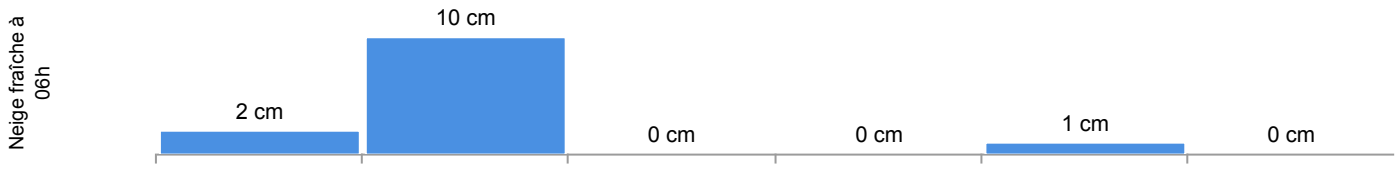

Risque d'avalanche	dim. 29/03	lun. 30/03	mar. 31/03	mer. 01/04	jeu. 02/04	ven. 03/04	sam. 04/04
	2	2	3	3	2	2	2



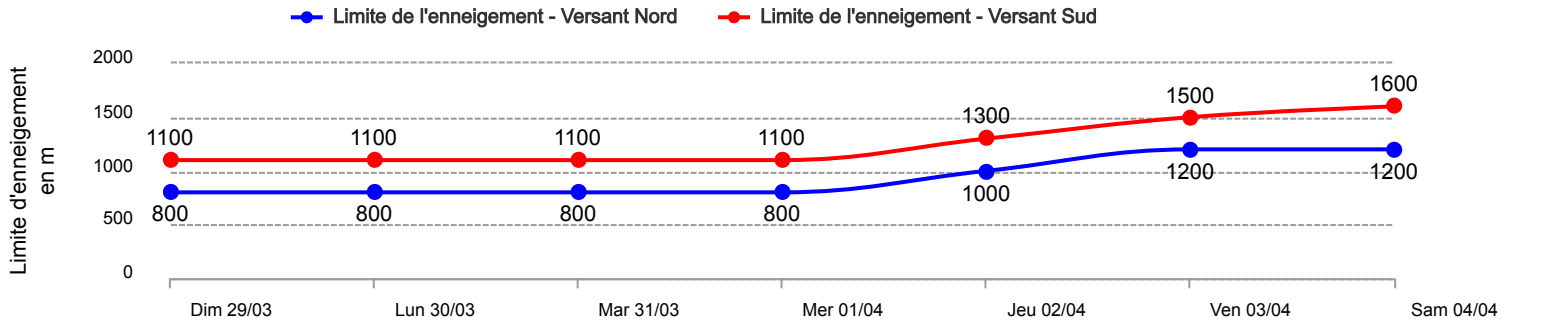

Pour consulter la vigilance en cours, veuillez vous rendre sur le site https://vigilance.meteofrance.fr/fr

Météo-France - 73 avenue de Paris, 94165 Saint-Mandé cedex - Contact : contact@meteo.fr

Bulletin neige & avalanches par téléphone au

0 892 68 10 20 Service 0,35 € / min + prix appel

Rédigé par Météo-France avec la contribution des observateurs du réseau nivo-météorologiques. Partenariat : ANMSM (Maires de Stations de Montagne), DSF (Domaines Skiables de France), ADSP (Directeurs de Pistes et de la Sécurité des Stations de Sports d'Hiver) et autres acteurs de la montagne.