RÉPUBLIQUE FRANÇAISE
Liberté Égalité Fraternité

METEO FRANCE
À VOS CÔTÉS, DANS UN CLIMAT QUI CHANGE

Bulletin d'estimation du risque d'avalanche
(valable en dehors des pistes balisées et ouvertes)

MASSIF : Capcir Puymorens

Rédigé le samedi 4 avril 2026 à 16h

Estimation des risques pour le : DIMANCHE 05 AVRIL

POURSUITE DE L'HUMIDIFICATION, QUELQUES PLAQUES ENCORE PRÉSENTES EN ALTITUDE

2

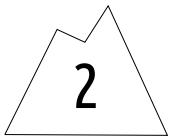

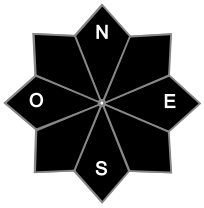

Indice de risque limité.

Départs spontanés : En neige humide au fil de l'ensoleillement

Déclenchements provoqués : En versants froids d'altitude, de moins en moins probables

Indices de risque : 5 très fort - 4 fort - 3 marqué - 2 limité - 1 faible -- En noir : les pentes les plus dangereuses

Stabilité du manteau neigeux

Situation avalancheuse typique : neige humide neige ventée

Départs spontanés :
- Des départs ponctuels d'avalanches de taille petite à moyenne sont attendus dans les pentes raides au fil de l'ensoleillement, quasiment en toutes orientations. Seules les faces nord d'altitude peuvent encore y échapper. Ces départs emporteront la neige tombée depuis lundi. Les plus gros volumes sont attendus principalement dans les versants nord-est à sud, plus chargés par le vent qui a soufflé cette semaine.

Observables : neige humide sans cohésion

- En dessous de 2000m, des avalanches de fond sont aussi possibles dans les pentes herbeuses ou sur des dalles rocheuses lisses récemment recouvertes par les chutes de la semaine. Elles seront de taille petite à moyenne.

Observables : fissures, reptations récentes

Déclenchements provoqués :
-Quelques structures de plaques peuvent encore subsister dans la neige récente des versants Nord-Ouest à Est d'altitude. En cours de stabilisation, elles deviennent plus difficilement déclenchables. Elles peuvent néanmoins occasionner des avalanches petites à moyennes, voir grandes plus rarement.

Observables : Avalanches récentes, aspect ventée de la surface et accumulations locales, fissures éventuelles devant les skis.

- Ailleurs, le risque se limite à des départs ponctuels dans la neige humide en coupant une pente raide déjà bien humidifiée.

Autre : Corniches volumineuses proches des crêtes avec les chutes de neige ventée de cette semaine.

Qualité de la neige

Enneigement :
L'enneigement est excellent cette année pour un début avril avec des cumuls conséquents en altitude malgré des crêtes et sommets exposés au vent d'ouest à nord-ouest souvent dégarnis. On peut toujours chausser les skis vers 1500 m au mieux sur la neige récente mais plutôt à partir de 1600/1700 m avec de la neige plus ancienne.

Qualité de la neige :
Dimanche matin, on attend un regel efficace (en dehors de la forêt) avec de la neige dure et portante. On pourra encore trouver de la neige légère et poudreuse dans de rares combes d'altitude abritées du vent en secteurs nord-ouest à nord-est. Là où le vent a soufflé, la neige est plus dure et tassée.
En journée, l'humidification reprend en surface quasiment jusqu'en haut des massif, avec de la neige humide en profondeur et gorgée d'eau au soleil dans les versants Est à Ouest en passant par le Sud, au fil de l'ensoleillement, ainsi que dans les versants nord en dessous de 2200m environ.

Aperçu météo pour le dimanche 05 avril

	nuit	matin	après-midi	soir
Belle journée printanière				
Pluie-Neige				
Iso 0 °C	3 300 m	3 200 m	3 100 m	3 200 m
Vent 2000 m	10 km/h	5 km/h	10 km/h	5 km/h
Vent 3000 m	15 km/h	10 km/h	15 km/h	10 km/h

Pour consulter la vigilance en cours, veuillez vous rendre sur le site https://vigilance.meteofrance.fr/fr

Météo-France - 73 avenue de Paris, 94165 Saint-Mandé cedex - Contact : contact@meteo.fr

Rédigé par Météo-France avec la contribution des observateurs du réseau nivo-météorologiques. Partenariat : ANMSM (Maires de Stations de Montagne), DSF (Domaines Skiables de France), ADSP (Directeurs de Pistes et de la Sécurité des Stations de Sports d'Hiver) et autres acteurs de la montagne.

Bulletin neige & avalanches par téléphone au
0 892 68 10 20 Service 0,35 € / min + prix appel

Bulletin d'estimation du risque d'avalanche

(valable en dehors des pistes balisées et ouvertes)

MASSIF : Capcir Puymorens

Rédigé le samedi 4 avril 2026 à 16h

Épaisseur de neige hors-piste

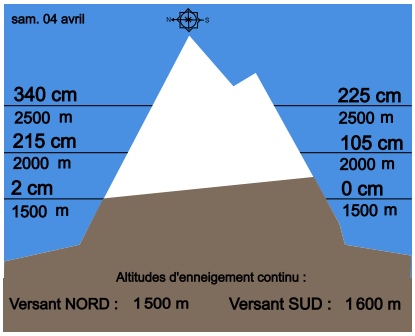

Précipitations à 1800 m

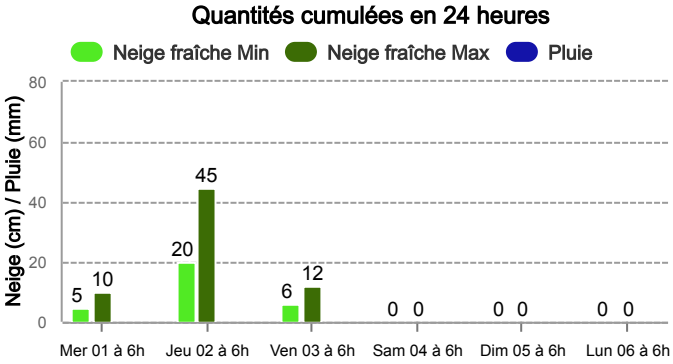

Tendance du lundi 06 avril

Indice de risque limité

Poursuite de l'humidification du manteau en journée, stabilisation des dernières plaques en altitude.

Pour consulter la vigilance en cours, veuillez vous rendre sur le site https://vigilance.meteofrance.fr/fr

Météo-France - 73 avenue de Paris, 94165 Saint-Mandé cedex - Contact : contact@meteo.fr

Rédigé par Météo-France avec la contribution des observateurs du réseau nivo-météorologiques. Partenariat : ANMSM (Maires de Stations de Montagne), DSF (Domaines Skiables de France), ADSP (Directeurs de Pistes et de la Sécurité des Stations de Sports d'Hiver) et autres acteurs de la montagne.

Bulletin neige & avalanches par téléphone au

0 892 68 10 20 Service 0,35 € / min + prix appel

RÉPUBLIQUE FRANÇAISE
Liberté Égalité Fraternité

METEO FRANCE
À VOS CÔTÉS, DANS UN CLIMAT QUI CHANGE

Bulletin d'estimation du risque d'avalanche

(valable en dehors des pistes balisées et ouvertes)

MASSIF : Capcir Puymorens

Rédigé le samedi 4 avril 2026 à 16h

Conditions nivo-météo des 7 derniers jours

	dim. 29/03				lun. 30/03				mar. 31/03				mer. 01/04				jeu. 02/04				ven. 03/04				sam. 04/04			
	03h	09h	15h	21h	03h	09h	15h	21h	03h	09h	15h	21h	03h	09h	15h	21h	03h	09h	15h	21h	03h	09h	15h	21h	03h	09h	15h	21h
Météo																												
Vent (km/h)	115	110	95	85	80	80	95	100	95	85	95	95	90	85	90	95	90	90	95	85	75	70	50	45	50	40	25	20
à 3000m	↓	↓	↘	↘	↘	↓	↘	↘	↘	↘	↘	↘	↘	↘	↘	↘	↘	↘	↘	↘	↘	↓	↘	↓	↘	↓	↙	↘
Vent (km/h)	90	90	80	65	70	70	80	85	80	80	80	80	80	75	85	85	75	75	80	75	60	55	40	35	40	30	10	5
à 2000m	↘	↓	↓	↓	↓	↓	↘	↓	↘	↘	↘	↓	↓	↘	↘	↓	↘	↘	→	↓	↘	↓	↘	↘	↓	↓	↙	→

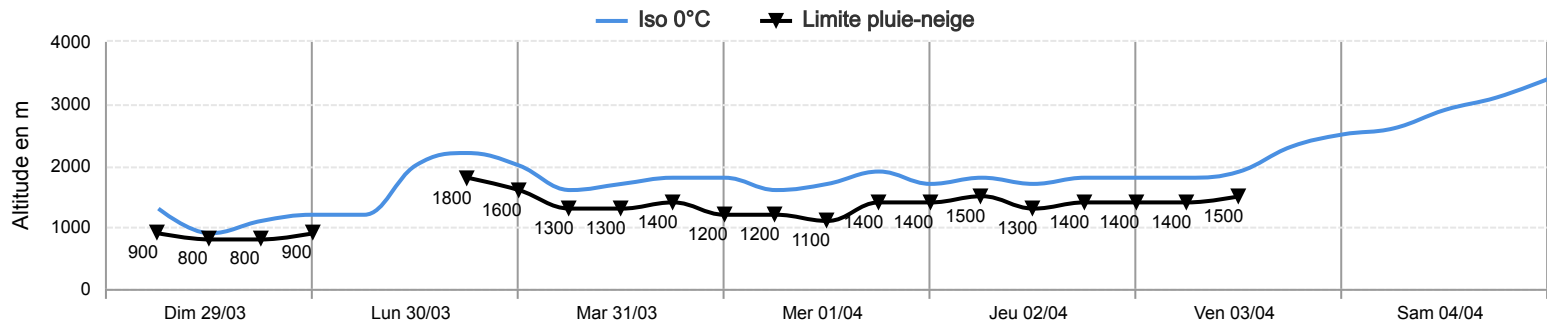

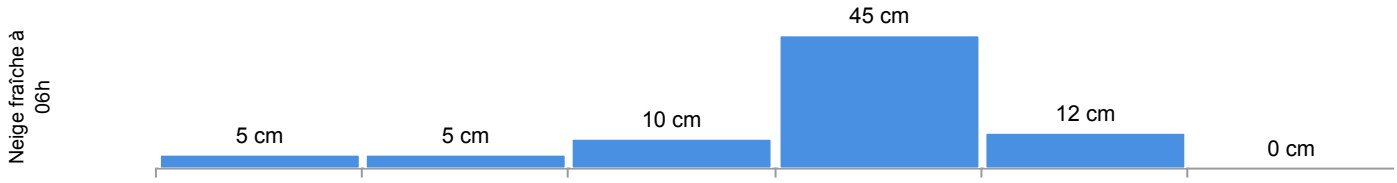

Risque d'avalanche	dim. 29/03	lun. 30/03	mar. 31/03	mer. 01/04	jeu. 02/04	ven. 03/04	sam. 04/04
	3	3	3	3	4	4	3

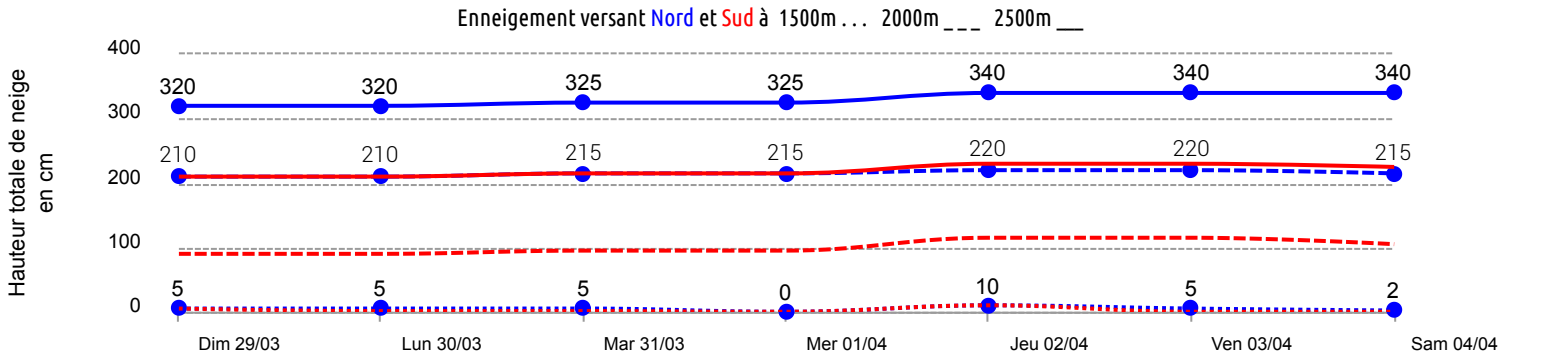

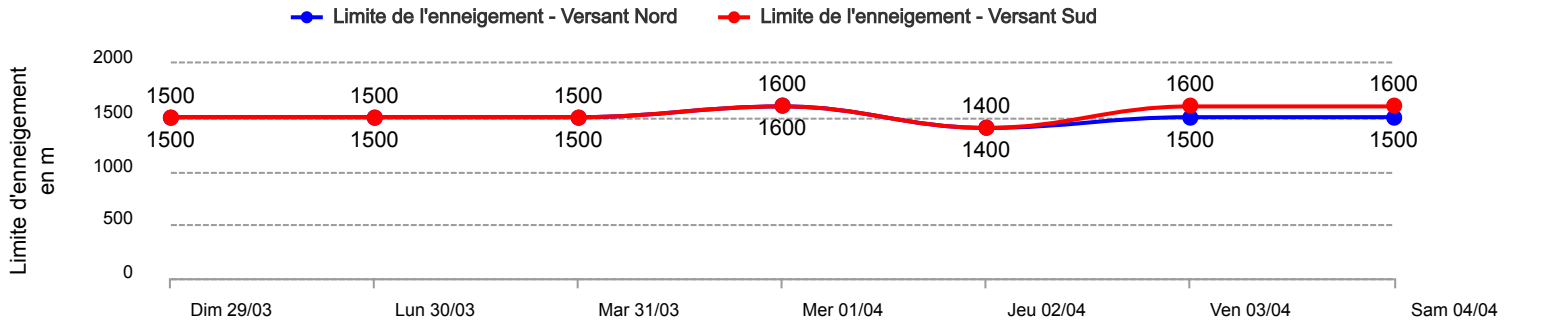

Pour consulter la vigilance en cours, veuillez vous rendre sur le site https://vigilance.meteofrance.fr/fr

Météo-France - 73 avenue de Paris, 94165 Saint-Mandé cedex - Contact : contact@meteo.fr

Rédigé par Météo-France avec la contribution des observateurs du réseau nivo-météorologiques. Partenariat : ANMSM (Maires de Stations de Montagne), DSF (Domaines Skiables de France), ADSP (Directeurs de Pistes et de la Sécurité des Stations de Sports d'Hiver) et autres acteurs de la montagne.

Bulletin neige & avalanches par téléphone au
0 892 68 10 20 Service 0,35 € / min + prix appel