Bulletin d'estimation du risque d'avalanche
(valable en dehors des pistes balisées et ouvertes)

MASSIF : Chartreuse

Rédigé le samedi 4 avril 2026 à 16h

Estimation des risques pour le : DIMANCHE 05 AVRIL

POSSIBLES COULEES DES LE MATIN, RARES AVALANCHES HUMIDES, Y COMPRIS EN FACES "FROIDES"...

2

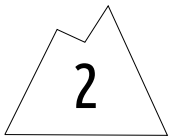

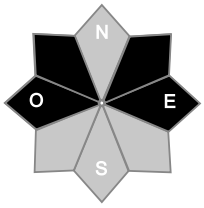

Pentes humidifiées

Indice de risque limité.

Départs spontanés : Assez tôt, possibles coulées en pentes raides/humidifiées, y compris en faces "froides" (de taille 1)... Attention aussi au soleil corniches fragilisées. Rare avalanche de fond en pente herbeuse peu ensoleillée ? (de taille 2 à 3).

Déclenchements provoqués : En pente bien humide, possible coulée ponctuelle sous les skis...

Indices de risque : 5 très fort - 4 fort - 3 marqué - 2 limité - 1 faible -- En noir : les pentes les plus dangereuses

Stabilité du manteau neigeux

Situation avalancheuse typique : neige humide avalanches de fond

Médiocre regel et neige s'humidifiant plus en profondeur, un peu d'activité printanière dans les pentes habituellement moins ensoleillées ...
Le pratiquant sera attentif aux surfaces temporairement durcies ou croutées par regel.

Départs spontanés :
Regel nocturne faible ou absent puis dimanche rapide redoux, y compris en versant peu ensoleillés. Dès la matinée, on peut s'attendre à quelques nouvelles coulées/ petites avalanches humides en pentes habituellement moins "chaudes". Dans un rare cas une avalanche de glissement plus conséquente, au terrain, n'est pas exclue (alpage raide). En plein Sud moins de neige ou neige dense, plutôt un risque de chute de corniche en haut de couloir ?

Déclenchements provoqués :
Pas de risque de plaque a priori. En pentes soutenues et bien humidifiées, le skieur se méfiera d'un risque de coulée humide ponctuelle sous un virage, la neige plus récente glissant sur les sous-couches denses...

Autres : A l'ombre (le matin surtout) neige durcie ou croutée par regel, surfaces temporairement glissantes...

Qualité de la neige

Qualification de l'enneigement : Malgré la récente fonte l'enneigement reste correct dès assez basse altitude, et même très bon vers les hauts de Chartreuse...
Limites skiables : Vers 1100/1300m en Nord, 1500/1700m au soleil...

Qualité de la neige dimanche : En Nord d'altitude, neige finement croutée/cassante le matin avec des restes de congères/effets du vent.. En pentes ensoleillées neige printanière, regel assez superficiel au petit matin... Très rapide humidification en journée.

Aperçu météo pour le dimanche 05 avril

	nuit	matin	après-midi	soir

Ciel voilé durant la nuit de samedi à dimanche, faible regel le matin. En journée soleil et nette douceur, digne d'un mois de mai !

Pluie-Neige				
Iso 0 °C	3 200 m	3 000 m	3 000 m	2 900 m
Vent 1500 m	↖ 15 km/h	↑ 15 km/h	↗ 20 km/h	↗ 20 km/h
Vent 2000 m	↗ 15 km/h	↗ 15 km/h	↗ 25 km/h	→ 25 km/h

Épaisseur de neige hors-piste

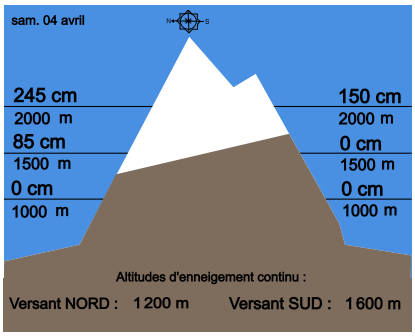

Précipitations à 1800 m

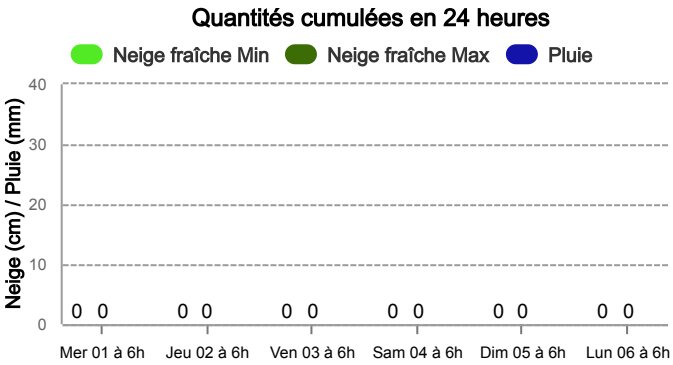

Tendance du lundi 06 avril

2

Indice de risque limité

Risque d'avalanches humides en hausse lundi, notamment en faces Nord : Nuit de dimanche à lundi nuageuse, pas de regel a priori

Pour consulter la vigilance en cours, veuillez vous rendre sur le site https://vigilance.meteofrance.fr/fr

Météo-France - 73 avenue de Paris, 94165 Saint-Mandé cedex - Contact : contact@meteo.fr

Rédigé par Météo-France avec la contribution des observateurs du réseau nivo-météorologiques. Partenariat : ANMSM (Maires de Stations de Montagne), DSF (Domaines Skiables de France), ADSP (Directeurs de Pistes et de la Sécurité des Stations de Sports d'Hiver) et autres acteurs de la montagne.

Bulletin neige & avalanches par téléphone au
0 892 68 10 20 Service 0,35 € / min + prix appel

RÉPUBLIQUE FRANÇAISE
Liberté Égalité Fraternité

METEO FRANCE
À VOS CÔTÉS, DANS UN CLIMAT QUI CHANGE

Bulletin d'estimation du risque d'avalanche

(valable en dehors des pistes balisées et ouvertes)

MASSIF : Chartreuse

Rédigé le samedi 4 avril 2026 à 16h

Conditions nivo-météo des 7 derniers jours

	dim. 29/03				lun. 30/03				mar. 31/03				mer. 01/04				jeu. 02/04				ven. 03/04				sam. 04/04			
	03h	09h	15h	21h	03h	09h	15h	21h	03h	09h	15h	21h	03h	09h	15h	21h	03h	09h	15h	21h	03h	09h	15h	21h	03h	09h	15h	21h
Météo																												
Vent (km/h)	60	50	35	40	45	40	60	65	75	65	65	60	50	35	40	25	25	35	45	40	40	30	20	20	35	30	15	15
à 2000m																												
Vent (km/h)	40	35	20	30	30	30	50	50	50	55	55	45	40	35	35	15	15	15	30	30	30	15	15	10	15	15	10	10
à 1500m																												

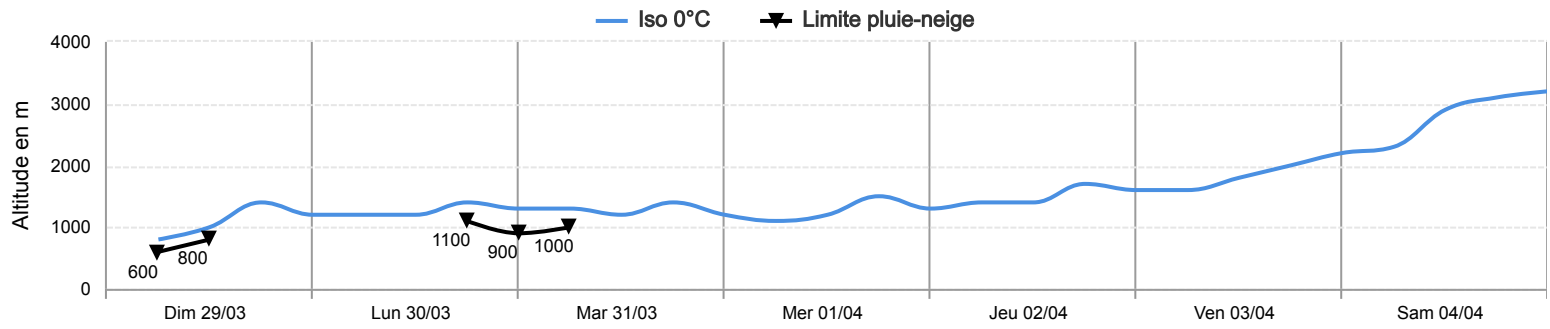

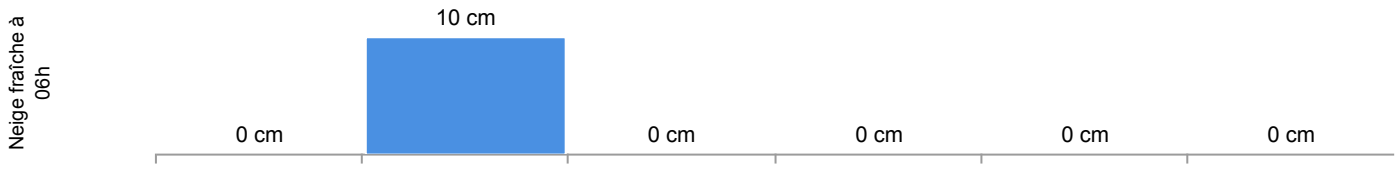

Risque d'avalanche	dim. 29/03	lun. 30/03	mar. 31/03	mer. 01/04	jeu. 02/04	ven. 03/04	sam. 04/04
	2	2	2	2	2	2	2

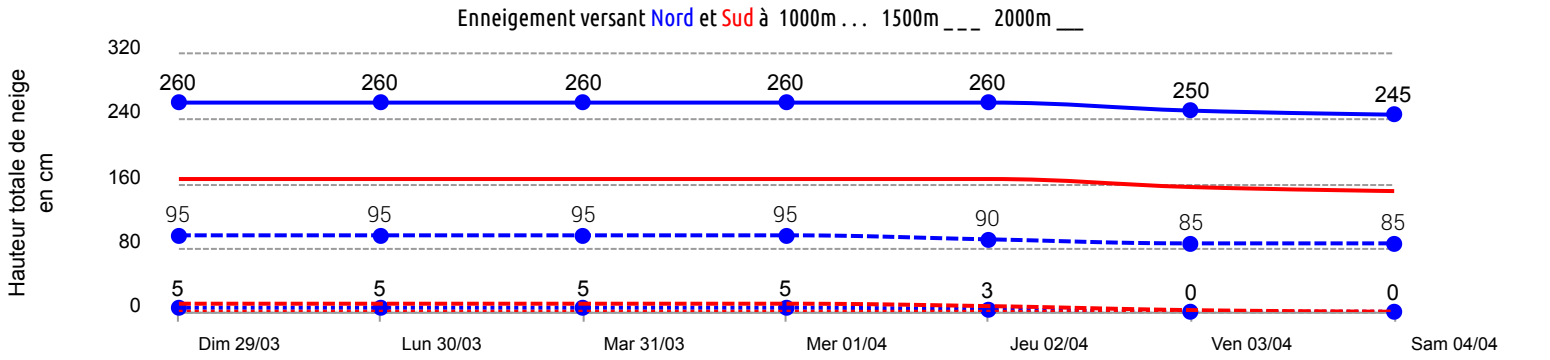

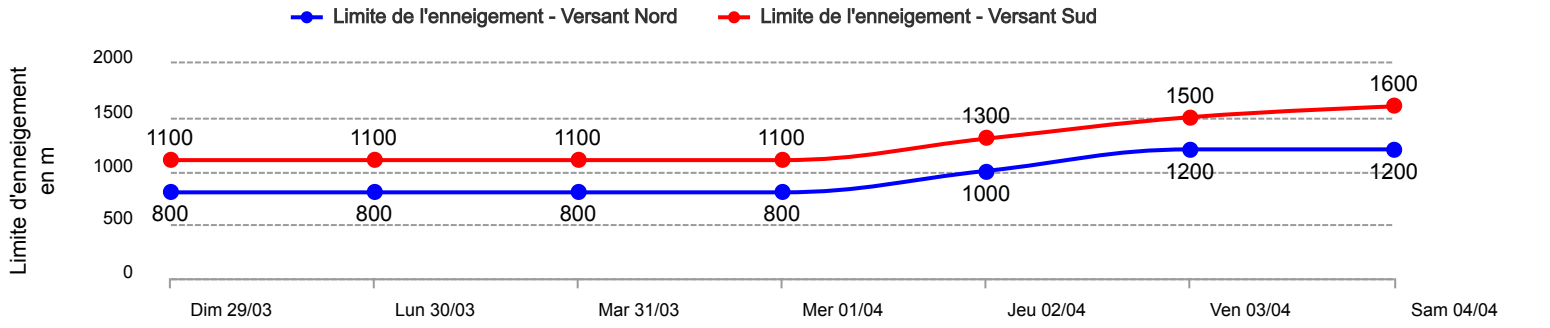

Pour consulter la vigilance en cours, veuillez vous rendre sur le site https://vigilance.meteofrance.fr/fr

Météo-France - 73 avenue de Paris, 94165 Saint-Mandé cedex - Contact : contact@meteo.fr

Bulletin neige & avalanches par téléphone au

0 892 68 10 20 Service 0,35 € / min + prix appel

Rédigé par Météo-France avec la contribution des observateurs du réseau nivo-météorologiques. Partenariat : ANMSM (Maires de Stations de Montagne), DSF (Domaines Skiables de France), ADSP (Directeurs de Pistes et de la Sécurité des Stations de Sports d'Hiver) et autres acteurs de la montagne.