Bulletin d'estimation du risque d'avalanche

(valable en dehors des pistes balisées et ouvertes)

MASSIF : Haute-Bigorre

Rédigé le samedi 4 avril 2026 à 16h

Estimation des risques pour le : DIMANCHE 05 AVRIL

NEIGE DE PRINTEMPS MAJORITAIRE, QUELQUES STRUCTURES DE PLAQUES ENCORE PRESENTES EN ALTITUDE.

2

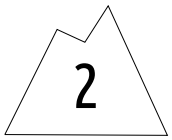

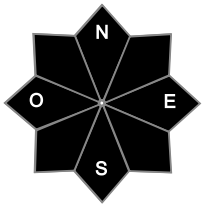

Indice de risque limité.

Départs spontanés : en neige humide au soleil.

Déclenchements provoqués : en neige humide au soleil, structures de plaques en Nord d'altitude.

Indices de risque : 5 très fort - 4 fort - 3 marqué - 2 limité - 1 faible -- En noir : les pentes les plus dangereuses

Stabilité du manteau neigeux

Situation avalancheuse typique : neige humide neige ventée

Déclenchements provoqués :
- au-dessus de 2400m, dans les expositions raides nord-ouest, nord et nord-est, des structures de plaques, souvent durcies juste en surface entre 2400 et 2600m, sont encore en place, formées lors des dernières chutes de neige (préférentiellement derrière crêtes, cols, et dans les combes déventées). Ces structures restent facilement déclenchables par un seul skieur ou randonneur, et peuvent donner lieu à des avalanches de taille petite à moyenne (accumulations en cours de tassement mais encore parfois importantes).
- en dessous de 2400m des versants décrits ci-dessus et dans tous les autres secteurs, déclenchement facile de neige humide par un skieur ou randonneur au soleil. Plutôt coulée ou petite avalanche attendue en matinée en est à sud-est, avalanche petite à parfois moyenne l'après-midi en sud à ouest, notamment à proximité des fissures.

Observables : travail du vent très visible en altitude, fissures ouvertes en est à sud-ouest sous 2200/2300m.

Déclenchements spontanés :
Rares et peu importants en début de matinée, plus nombreux et prenant de l'ampleur au cours de la journée. Généralement sous forme de coulée ou d'avalanche de petite taille près des rochers et à proximité des zones déjà déneigées, localement de taille moyenne dans l'après-midi avec départs linéaires de plaques de fond, encore possibles en partant d'une accumulation encore présente sur le haut du massif.

Autres : ponts de neige et corniches encore en place fragilisés au soleil.

Qualité de la neige

Enneigement : bon pour la saison, débutant vers 1500m en nord, plutôt 1600 à 1700m en sud.
État de la neige : neige de printemps dans une grande majorité des secteurs : regelée, dure et portante au petit matin, ramollissant vite au soleil. Humidification un peu plus lente en versants nord mais accentuée et se faisant plus en profondeur par rapport aux jours précédents. Dans les pentes nord raides, neige légèrement croûtée en surface entre 2400 et 2600m, encore sèche et assez meuble au-dessus, s'humidifiant lentement mais sûrement au cours de la journée dans la douceur.

Aperçu météo pour le dimanche 05 avril

	nuit	matin	après-midi	soir
Beau temps sec et doux après bon regel nocturne.				
Pluie-Neige				
Iso 0 °C	3 100 m	3 100 m	3 100 m	3 100 m
Vent 2000 m	5 km/h	0 km/h	5 km/h	10 km/h
Vent 3000 m	20 km/h	15 km/h	20 km/h	30 km/h

Épaisseur de neige hors-piste

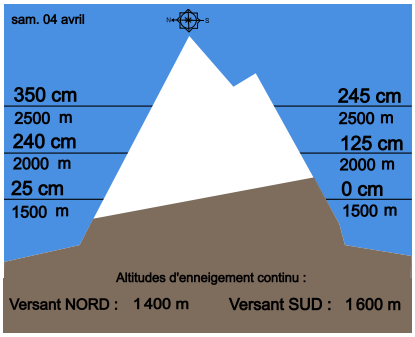

Précipitations à 1800 m

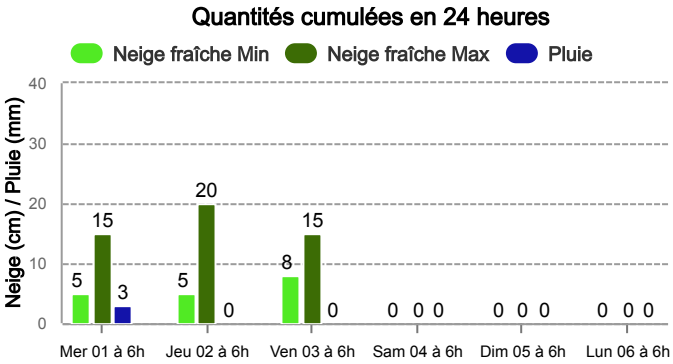

Tendance du lundi 06 avril

2

Indice de risque limité

Dans la majorité des pentes, on garde des conditions de neige de printemps : regel nocturne, humidification marquée en journée. Dans les versants raides nord au-dessus de 2400/2500m, humidification un peu plus lente mais en cours. Le risque restera au plus limité (2).

Pour consulter la vigilance en cours, veuillez vous rendre sur le site https://vigilance.meteofrance.fr/fr

Météo-France - 73 avenue de Paris, 94165 Saint-Mandé cedex - Contact : contact@meteo.fr

Rédigé par Météo-France avec la contribution des observateurs du réseau nivo-météorologiques. Partenariat : ANMSM (Maires de Stations de Montagne), DSF (Domaines Skiables de France), ADSP (Directeurs de Pistes et de la Sécurité des Stations de Sports d'Hiver) et autres acteurs de la montagne.

Bulletin neige & avalanches par téléphone au
0 892 68 10 20 Service 0,35 € / min + prix appel

RÉPUBLIQUE FRANÇAISE
Liberté Égalité Fraternité

METEO FRANCE
À VOS CÔTÉS, DANS UN CLIMAT QUI CHANGE

Bulletin d'estimation du risque d'avalanche
(valable en dehors des pistes balisées et ouvertes)
MASSIF : Haute-Bigorre

Rédigé le samedi 4 avril 2026 à 16h

Conditions nivo-météo des 7 derniers jours

	dim. 29/03				lun. 30/03				mar. 31/03				mer. 01/04				jeu. 02/04				ven. 03/04				sam. 04/04			
	03h	09h	15h	21h	03h	09h	15h	21h	03h	09h	15h	21h	03h	09h	15h	21h	03h	09h	15h	21h	03h	09h	15h	21h	03h	09h	15h	21h
Météo																												
Vent (km/h)	90	105	85	75	65	70	75	80	70	70	70	90	75	80	90	90	85	90	80	75	60	50	25	20	15	25	15	20
à 3000m																												
Vent (km/h)	65	70	60	40	25	25	35	40	35	35	35	45	40	40	45	60	50	50	50	45	35	15	20	15	15	10	5	5
à 2000m																												

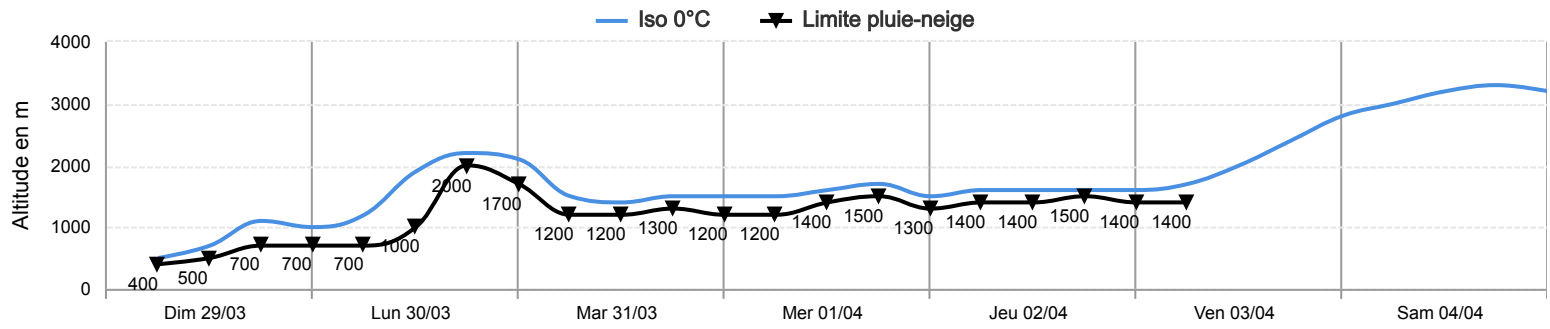

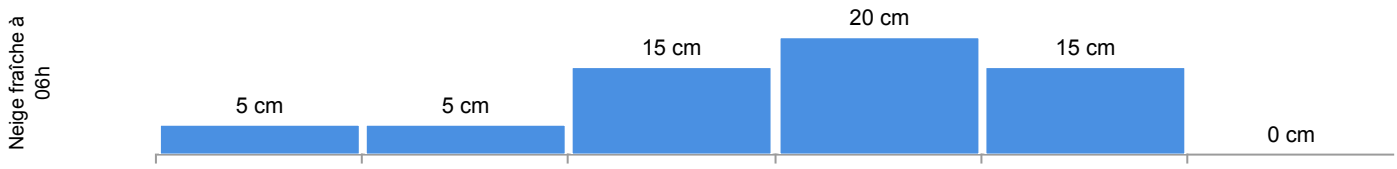

Risque d'avalanche	dim. 29/03	lun. 30/03	mar. 31/03	mer. 01/04	jeu. 02/04	ven. 03/04	sam. 04/04
	3	3	3	4	4	4	3

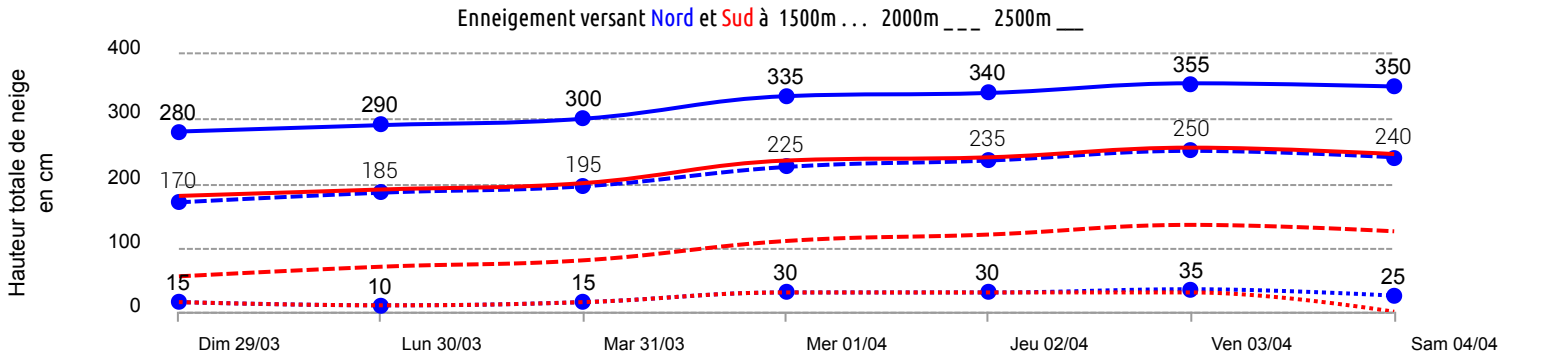

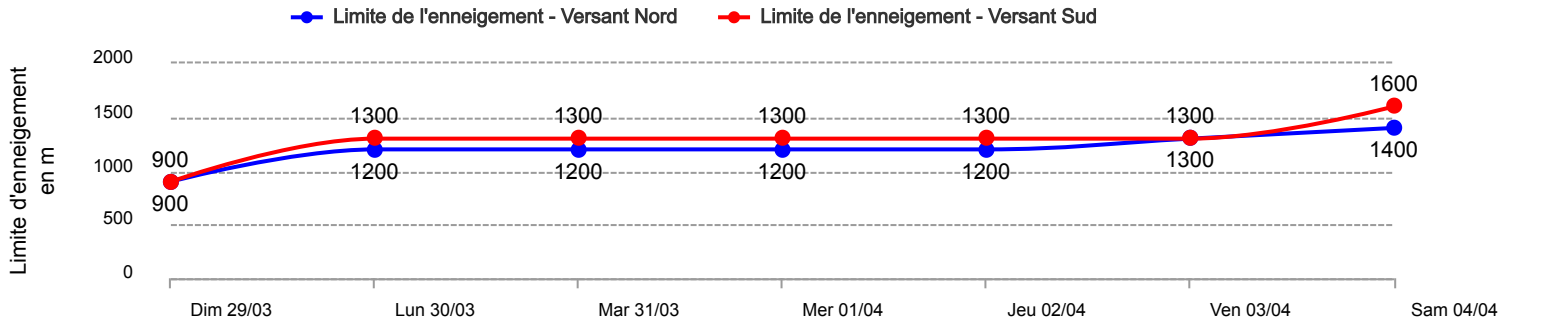

Pour consulter la vigilance en cours, veuillez vous rendre sur le site https://vigilance.meteofrance.fr/fr

Météo-France - 73 avenue de Paris, 94165 Saint-Mandé cedex - Contact : contact@meteo.fr

Bulletin neige & avalanches par téléphone au **0 892 68 10 20** Service 0,35 € / min + prix appel

Rédigé par Météo-France avec la contribution des observateurs du réseau nivo-météorologiques. Partenariat : ANMSM (Maires de Stations de Montagne), DSF (Domaines Skiables de France), ADSP (Directeurs de Pistes et de la Sécurité des Stations de Sports d'Hiver) et autres acteurs de la montagne.