Bulletin d'estimation du risque d'avalanche

(valable en dehors des pistes balisées et ouvertes)

MASSIF : Cinto Rotondo

Rédigé le samedi 4 avril 2026 à 17h

Estimation des risques pour le : DIMANCHE 05 AVRIL

PLAQUES EN ALTITUDE, EN COURS DE STABILISATION, ET QUELQUES DÉPARTS AU SOLEIL

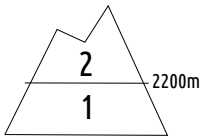

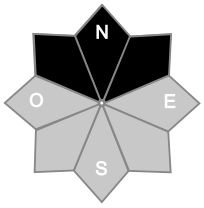

Au-dessus de 2200m indice de risque limité, plus bas indice faible.

Départs spontanés : rares départs de coulées de neige humide dans les pentes raides bien ensoleillées

Déclenchements provoqués : rares plaques à vent présentes en altitude au-dessus de 2200 m, en cours de stabilisation

Indices de risque : 5 très fort - 4 fort - 3 marqué - 2 limité - 1 faible -- En noir : les pentes les plus dangereuses

Stabilité du manteau neigeux

Situation avalancheuse typique : neige ventée

Déclenchements provoqués : De fines plaques à vent sont en place dans les pentes raides, généralement en neige dure bien identifiable, majoritairement au-dessus de 2200 m. Ces plaques, surtout présentes dans une large orientation nord, peuvent engendrer de petites avalanches, rarement moyennes (taille 1 à 2). La douceur et l'ensoleillement entament la consolidation de ces instabilités. Départ restant possible au passage d'un seul skieur, plutôt à distance des crêtes et à proximité des ruptures de pentes.
Départs spontanés : Avec la hausse des températures, des départs de neige humide sont possibles en versants raides ensoleillés l'après-midi. Ils restent rares et superficiels.
Autres : Nombreuses surfaces dures et glacées, pouvant être recouvertes de quelques centimètres de neige récente. Présence de corniches.

Qualité de la neige

Qualification de l'enneigement : L'enneigement est excellent pour la saison et même excédentaire au-dessus de 1700 m. Sur la Maniccia, à 2400 m d'altitude dans le massif du Rotondo, on relève 3m15 de hauteur de neige totale.
Limite d'enneigement skiable : 1500 à 1600m.
État de la neige : contrastée suivant les versants ; en Sud raide, neige de printemps : dure le matin, ramollissant en s'humidifiant avec l'air un peu plus doux et le soleil en cours de journée. En Nord, il reste des surfaces de neige sèche, souvent dure, parfois vitrifiée au petit matin, ramollissant lentement en cours de journée et juste en surface, restant dure au-dessus de 2000 à 2200 m avec un peu de neige récente.

Aperçu météo pour le dimanche 05 avril

	nuit	matin	après-midi	soir
Printanier.				
Pluie-Neige				
Iso 0 °C	2 900 m	3 000 m	3 000 m	3 100 m
Vent 1500 m	↓ 10 km/h	↓ 5 km/h	→ 10 km/h	→ 10 km/h
Vent 3000 m	↙ 20 km/h	↓ 20 km/h	↓ 5 km/h	↘ 15 km/h

Épaisseur de neige hors-piste

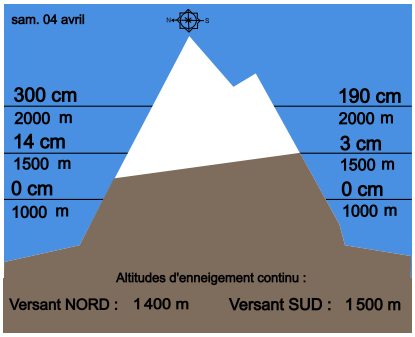

Précipitations à 1800 m

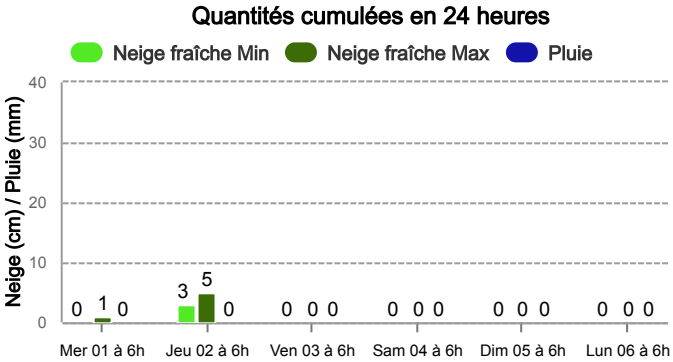

Tendance du lundi 06 avril

Indice de risque faible

La douceur favorise la stabilisation des rares plaques qui subsistent. Quelques départs en versants raides ensoleillés. Évolution vers un risque faible.

Pour consulter la vigilance en cours, veuillez vous rendre sur le site https://vigilance.meteofrance.fr/fr

Météo-France - 73 avenue de Paris, 94165 Saint-Mandé cedex - Contact : contact@meteo.fr

Rédigé par Météo-France avec la contribution des observateurs du réseau nivo-météorologiques. Partenariat : ANMSM (Maires de Stations de Montagne), DSF (Domaines Skiables de France), ADSP (Directeurs de Pistes et de la Sécurité des Stations de Sports d'Hiver) et autres acteurs de la montagne.

Bulletin neige & avalanches par téléphone au
0 892 68 10 20 Service 0,35 € / min + prix appel

RÉPUBLIQUE FRANÇAISE
Liberté Égalité Fraternité

METEO FRANCE
À VOS CÔTÉS, DANS UN CLIMAT QUI CHANGE

Bulletin d'estimation du risque d'avalanche

(valable en dehors des pistes balisées et ouvertes)

MASSIF : Cinto Rotondo

Rédigé le samedi 4 avril 2026 à 17h

Conditions nivo-météo des 7 derniers jours

	dim. 29/03				lun. 30/03				mar. 31/03				mer. 01/04				jeu. 02/04				ven. 03/04				sam. 04/04			
	03h	09h	15h	21h	03h	09h	15h	21h	03h	09h	15h	21h	03h	09h	15h	21h	03h	09h	15h	21h	03h	09h	15h	21h	03h	09h	15h	21h
Météo																												
Vent (km/h)	15	35	45	30	25	15	30	40	70	70	70	95	80	70	45	60	60	45	40	50	60	50	40	25	40	40	30	30
à 3000m																												
Vent (km/h)	10	35	45	30	25	15	30	30	40	60	30	70	95	100	50	55	50	40	40	35	35	30	25	15	10	15	15	15
à 1500m																												

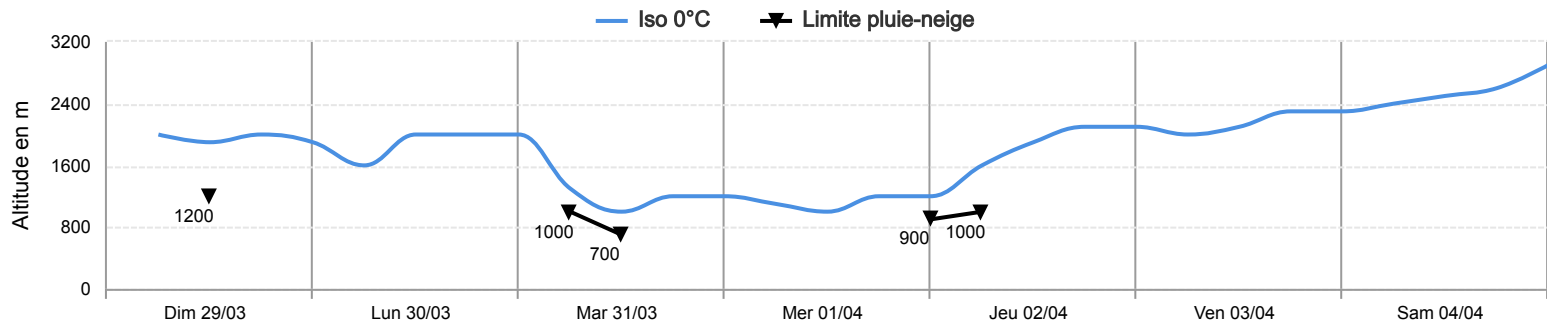

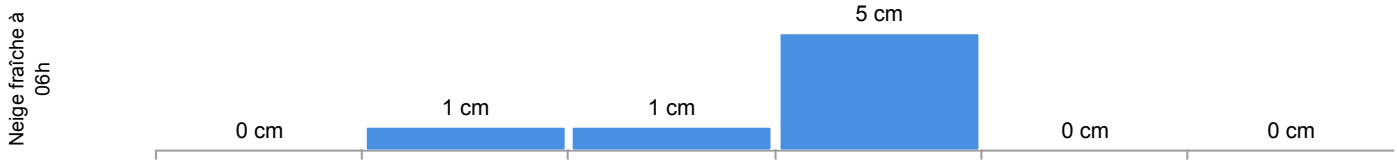

Risque d'avalanche	dim. 29/03	lun. 30/03	mar. 31/03	mer. 01/04	jeu. 02/04	ven. 03/04	sam. 04/04
	2	2	2	2	2	2	2

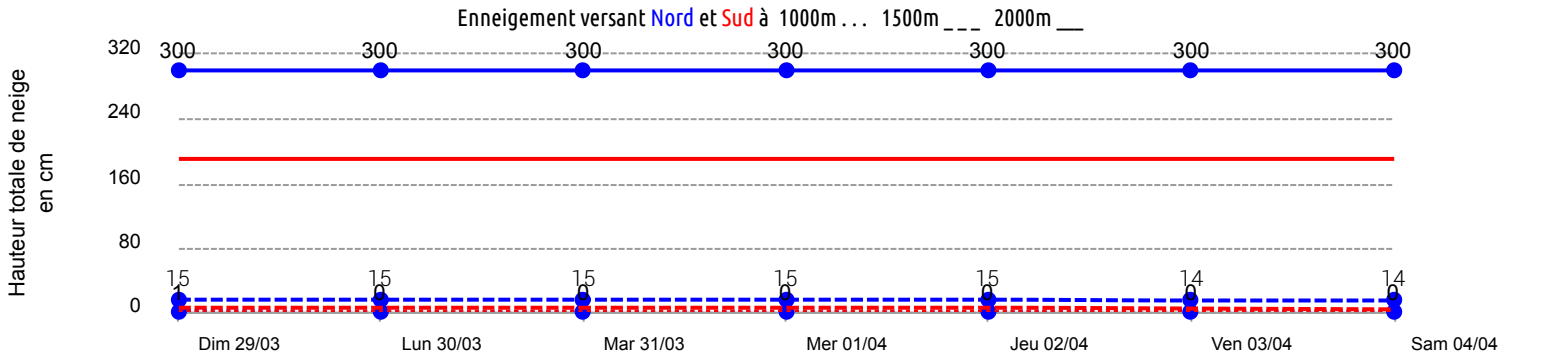

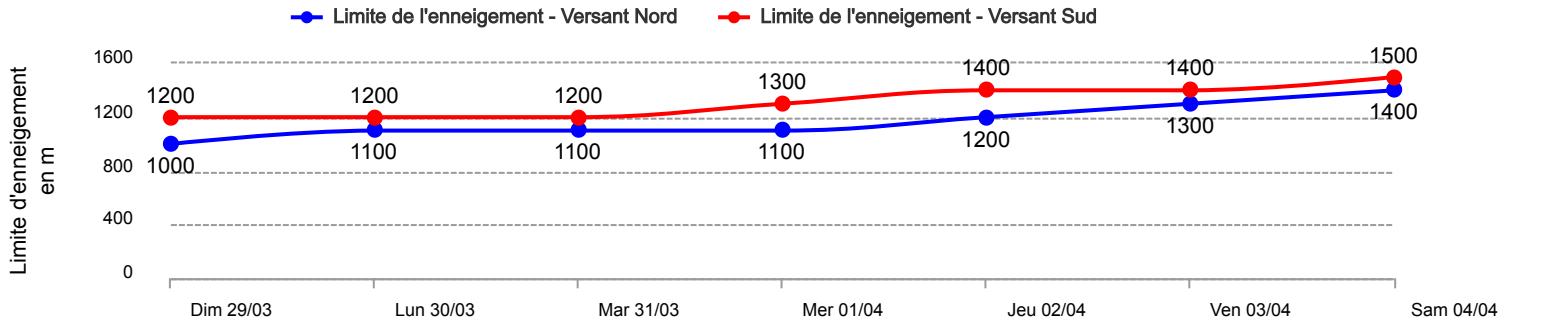

Pour consulter la vigilance en cours, veuillez vous rendre sur le site https://vigilance.meteofrance.fr/fr

Météo-France - 73 avenue de Paris, 94165 Saint-Mandé cedex - Contact : contact@meteo.fr

Bulletin neige & avalanches par téléphone au **0 892 68 10 20** Service 0,35 € / min + prix appel

Rédigé par Météo-France avec la contribution des observateurs du réseau nivo-météorologiques. Partenariat : ANMSM (Maires de Stations de Montagne), DSF (Domaines Skiables de France), ADSP (Directeurs de Pistes et de la Sécurité des Stations de Sports d'Hiver) et autres acteurs de la montagne.