GOBIERNO DE ESPAÑA
VICEPRESIDENCIA TERCERA DEL GOBIERNO
MINISTERIO PARA LA TRANSICIÓN ECOLÓGICA Y EL RETO DEMOGRÁFICO

Boletín de información nivológica y de peligro de aludes

Pirineo Catalán

aemet Agencia Estatal de Meteorología

domingo, 5 de abril de 2026

Pronóstico hasta las 24 horas del lunes, día 6 de abril

(Válido fuera de pistas de esquí balizadas y abiertas)

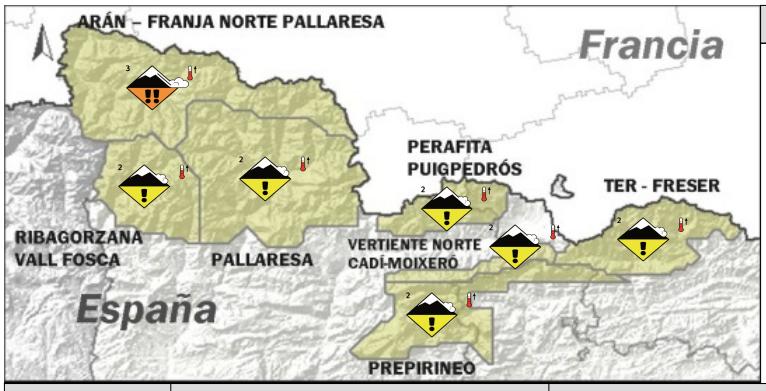

Problemas de aludes

Nieve húmeda

Placas de viento

Macizo	Peligro	Problemas de aludes, cota, orientación, tamaño	Innivación observada (m)
Arán - Franja norte Pallaresa	3 / 3 / 2 / 2200 **Notable**	**Nieve húmeda** 2 **Placas de viento** 2 / 2200	2026-04-05 N / S Cota más baja caras N
Ribagorzana - Vall Fosca	2 / 2 **Limitado**	**Nieve húmeda** 2 **Placas de viento** 2 / 2200	2026-04-05 N / S Cota más baja caras N
Pallaresa	2 / 2 **Limitado**	**Nieve húmeda** 2 **Placas de viento** 2 / 2200	2026-04-05 N / S Cota más baja caras N

AEMET. Se autoriza la reproducción de su contenido citando la fuente.

Boletín de información nivológica y de peligro de aludes

Pirineo Catalán

Perafita - Puigpedrós	2 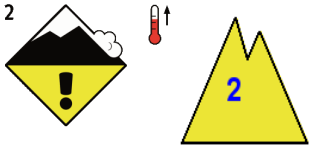 **Limitado**	**Nieve húmeda** 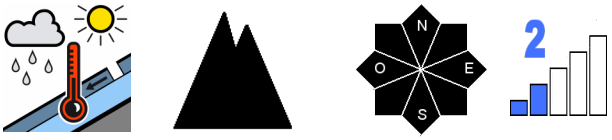 **Placas de viento** 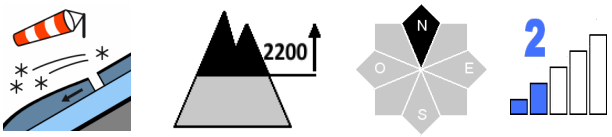	2026-04-05 Cota más baja caras N	
Ter - Freser	2 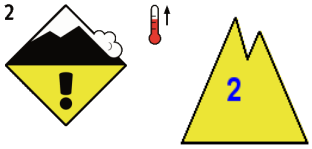 **Limitado**	**Nieve húmeda** **Placas de viento** 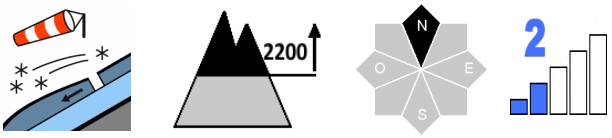	2026-04-05 Cota más baja caras N	
Vertiente norte Cadí - Moixeró	2 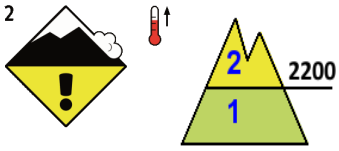 **Limitado**	**Nieve húmeda** **Placas de viento**	2026-04-05 Cota más baja caras N	
Prepirineo	2 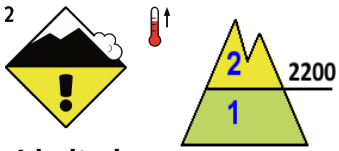 **Limitado**	**Nieve húmeda**	2026-04-05 Cota más baja caras N	

Estado del manto y observaciones recientes

Durante los dos últimos días han predominado los cielos despejados y las temperaturas han experimentado un acusado ascenso. Este ambiente cálido con abundante insolación va a continuar durante la jornada de hoy, intensificando la humidificación y compactación del manto, así como favoreciendo la progresiva estabilización de las placas de viento, especialmente en las solanas.

La cubierta nivosa ha ido retrocediendo a altitudes más elevadas, siendo continua a partir de unos 1700 en umbrías y 1900 metros en solanas, algo menos en el Arán y la Franja Norte Pallaresa donde las nevadas fueron más copiosas. A unos 2200-2400 metros se alcanzan los 120-220 cm en este macizo, y alrededor de los 80-150 cm en el resto, valores muy por encima de lo habitual para estas fechas, que se pueden superar ampliamente en ventisqueros y otras zonas propensas a la acumulación.

AEMET. Se autoriza la reproducción de su contenido citando la fuente.

Los fuertes vientos de componente norte que acompañaron a las nevadas formaron numerosas placas en muchas orientaciones, aunque con mayor frecuencia en vertientes sur. Parte de ellas se han ido estabilizando, pero todavía quedan activas en umbrías y en alguna solana de la alta montaña. En cotas medias y bajas el manto está húmedo y presenta perfil primaveral, sobre todo en solanas. No obstante, aún persisten algunas capas débiles en las altas umbrías, que podrían mostrar cierta reactividad.

Evolución del manto y peligro de aludes para el lunes, día 6

Problema de nieve húmeda y deslizamientos basales. Problema de placas de viento en umbrías de cotas altas.

Mañana, lunes, no se espera un rehielo muy efectivo, aunque a primeras horas aún podrían formarse algunas costras que sustentaran el manto. No obstante, generalmente la nieve se encontrará blanda, por lo que serán frecuentes los aludes de nieve húmeda, más probables en solanas y a partir del mediodía, de tamaño pequeño (riesgo de caída) o mediano (capaz de enterrar a una persona), incluso se podrán producir deslizamientos basales en terrenos herbosos o de roca lisa, sin descartar que alguno pudiera alcanzar un tamaño mayor.

Las placas de viento formadas durante el episodio pasado aún podrán mantenerse frágiles en umbrías y ceder ante una sobrecarga débil (paso de un esquiador), provocando aludes de tamaño mediano, o raramente grande (capaz de enterrar un vehículo) en las zonas de mayor acumulación o en el caso de afectar a una capa débil persistente situada a cierta profundidad.

Predicción meteorológica para el lunes, día 6

Poco nuboso o despejado, con algunas nubes altas. Por la tarde podrían crecer algunas nubes de evolución diurna. Temperaturas sin cambios o en ligero ascenso. Heladas débiles en las cumbres de mayor altitud, sin descartar alguna en fondos de valle. Viento flojo de dirección variable en cotas altas, tendiendo a flojo o moderado del sur por la tarde. En el resto soplará flojo de componente sur, con intervalos moderados en la segunda mitad del día.

Datos en la atmósfera libre:

Altitud de la isoterma de 0 ºC: 3300 m
Altitud de la isoterma de -10 ºC: 4600 m

Viento a 1500 m: S 20 km/h
Viento a 3000 m: S 20 km/h

Evolución para el martes día 7

Se mantendrán los problemas de nieve húmeda y deslizamientos basales. Las placas de viento tenderán a ir estabilizándose.

Escala europea de peligro de aludes

Débil | Limitado | Notable | Fuerte | Muy Fuerte

Problemas de aludes

Nieve reciente | Placas de viento | Capas débiles persistentes | Nieve húmeda | Deslizamientos basales | Sin problema evidente

AEMET. Se autoriza la reproducción de su contenido citando la fuente.

Nota1: Se recuerda que, siempre que haya nieve, la ausencia total de peligro no existe. Hay que tener presente que en circunstancias desfavorables, con aludes de tamaño 1 (alud pequeño o colada) y tamaño 2 (alud mediano), se pueden sufrir severos daños personales.

Nota2: Los BPA se elaboran en base a información meteorológica así como al estado del manto nivoso a través de sondeos puntuales. Se advierte a los usuarios de la variabilidad de esta información al extrapolarla a zonas extensas de montaña. Por ello, AEMET no se hace responsable de su uso para la toma de decisiones que conciernen a la seguridad personal, ni de los riesgos físicos o materiales de ellas derivadas.

AEMET. Se autoriza la reproducción de su contenido citando la fuente.