GOBIERNO DE ESPAÑA
VICEPRESIDENCIA TERCERA DEL GOBIERNO
MINISTERIO PARA LA TRANSICIÓN ECOLÓGICA Y EL RETO DEMOGRÁFICO

Boletín de información nivológica y de peligro de aludes

Pirineo Navarro y Aragonés

aemet Agencia Estatal de Meteorología

domingo, 5 de abril de 2026

Pronóstico hasta las 24 horas del lunes, día 6 de abril

(Válido fuera de pistas de esquí balizadas y abiertas)

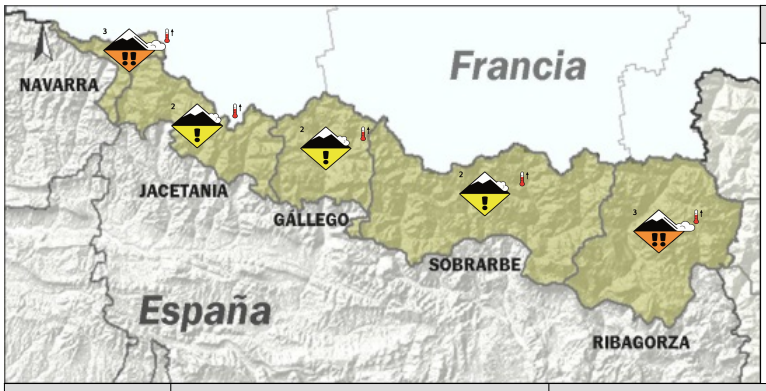

Problemas de aludes

Nieve húmeda

Placas de viento

Macizo	Peligro	Problemas de aludes, cota, orientación, tamaño	Innivación observada (m)
Navarra	3 (Notable) — 3 por 2200 m, 2 por debajo	Nieve húmeda: todas orientaciones, 2 — Placas de viento: por 2200 m, todas orientaciones, 2	2026-04-05 — N / S: Cota más baja caras N
Jacetania	2 (Limitado) — 2	Nieve húmeda: todas orientaciones, 2 — Placas de viento: por 2200 m, todas orientaciones, 2	2026-04-05 — N / S: Cota más baja caras N
Gállego	2 (Limitado) — 2	Nieve húmeda: todas orientaciones, 2 — Placas de viento: por 2200 m, todas orientaciones, 2	2026-04-05 — N / S: Cota más baja caras N

Boletín de información nivológica y de peligro de aludes

Pirineo Navarro y Aragonés

Sobrarbe	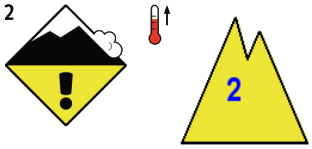 **Limitado**	**Nieve húmeda** 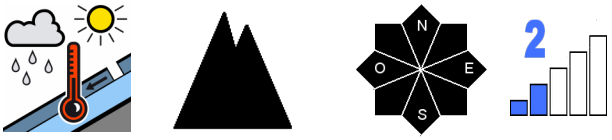 **Placas de viento** 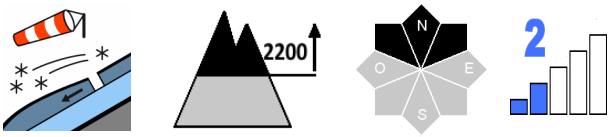	2026-04-05 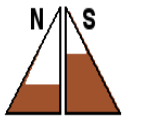 Cota más baja caras N
Ribagorza	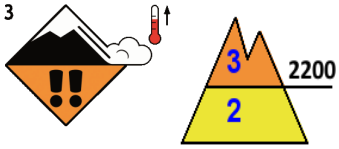 **Notable**	**Nieve húmeda** **Placas de viento**	2026-04-05 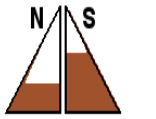 Cota más baja caras N

Estado del manto y observaciones recientes

Durante los dos últimos días han predominado los cielos despejados y las temperaturas han experimentado un acusado ascenso. Este ambiente cálido con abundante insolación va a continuar durante la jornada de hoy, intensificando la humidificación y compactación del manto, que pierde hasta 10 cm cada día, así como favoreciendo la progresiva estabilización de las placas de viento, especialmente en las solanas.

La cubierta nivosa ha ido retrocediendo a altitudes más elevadas, siendo continua a partir de unos 1700 metros en umbrías, algo más arriba en las zonas soleadas, si bien en cotas inferiores todavía se puede encontrar nieve en algunas áreas. A unos 2000-2200 metros los espesores rondan los 100-180 cm, valores por encima de lo habitual para estas fechas, que se pueden superar ampliamente en ventisqueros y otras zonas propensas a la acumulación.

Los fuertes vientos de componente norte que acompañaron a las nevadas formaron numerosas placas en muchas orientaciones, aunque con mayor frecuencia en vertientes sur. Parte de ellas se han ido estabilizando, pero todavía quedan activas en umbrías y en alguna solana de la alta montaña. En cotas medias y bajas el manto está húmedo y presenta perfil primaveral, sobre todo en solanas. No obstante, aún persisten algunas capas débiles en las altas umbrías, que podrían mostrar cierta reactividad.

Evolución del manto y peligro de aludes para el lunes, día 6

Problema de nieve húmeda y deslizamientos basales. Problema de placas de viento en umbrías de cotas altas.

Mañana, lunes, no se espera un rehielo muy efectivo, aunque a primeras horas aún podrían formarse algunas costras que sustentaran el manto. No obstante, generalmente la nieve se encontrará blanda, por lo que serán frecuentes los aludes de nieve húmeda, más probables en

AEMET. Se autoriza la reproducción de su contenido citando la fuente.

solanas y a partir del mediodía, de tamaño pequeño (riesgo de caída) o mediano (capaz de enterrar a una persona), incluso se podrán producir deslizamientos basales en terrenos herbosos o de roca lisa, sin descartar que alguno pudiera alcanzar un tamaño mayor.

Las placas de viento formadas durante el episodio pasado aún podrán mantenerse frágiles en umbrías y ceder ante una sobrecarga débil (paso de un esquiador), provocando aludes de tamaño mediano, o raramente grande (capaz de enterrar un vehículo) en las zonas de mayor acumulación o en el caso de afectar a una capa débil persistente situada a cierta profundidad.

Predicción meteorológica para el lunes, día 6

Poco nuboso o despejado, con algunas nubes altas. Por la tarde podría crecer alguna nube de evolución diurna en los macizos orientales. Temperaturas mínimas en ligero ascenso y máximas sin cambios, o algo más altas en el sector navarro. Heladas débiles en las cumbres de mayor altitud. Predominio del viento de componente sur, moderado aumentando a fuerte en Navarra, y flojo aumentando a moderado en los macizos aragoneses.

Datos en la atmósfera libre:

Altitud de la isoterma de 0 ºC: 3300 m
Altitud de la isoterma de -10 ºC: 4700 m

Viento a 1500 m: S de 20 km/h a 40 km/h
Viento a 3000 m: SE de 20 km/h a 30 km/h

Evolución para el martes día 7

Se mantendrán los problemas de nieve húmeda y deslizamientos basales. Las placas de viento tenderán a ir estabilizándose.

(Información elaborada a partir de los datos recibidos de los refugios de Lizara, Panticosa, Bachimaña, Góriz, Pineta, Estós, Angel Orús y Belagua, de las estaciones de esquí de Astún, Formigal y Panticosa (lagos), de la estación de esquí de fondo de Llanos del Hospital y de Ordesa Pradera)

Escala europea de peligro de aludes

Débil | Limitado | Notable | Fuerte | Muy Fuerte

Problemas de aludes

Nieve reciente | Placas de viento | Capas débiles persistentes | Nieve húmeda | Deslizamientos basales | Sin problema evidente

Nota1: Se recuerda que, siempre que haya nieve, la ausencia total de peligro no existe. Hay que tener presente que en circunstancias desfavorables, con aludes de tamaño 1 (alud pequeño o colada) y tamaño 2 (alud mediano), se pueden sufrir severos daños personales.

Nota2: Los BPA se elaboran en base a información meteorológica así como al estado del manto nivoso a través de sondeos puntuales. Se advierte a los usuarios de la variabilidad de esta información al extrapolarla a zonas extensas de montaña. Por ello, AEMET no se hace responsable de su uso para la toma de decisiones que conciernen a la seguridad personal, ni de los riesgos físicos o materiales de ellas derivadas.

AEMET. Se autoriza la reproducción de su contenido citando la fuente.