Bulletin d'estimation du risque d'avalanche

(valable en dehors des pistes balisées et ouvertes)

MASSIF : Aspe Ossau

Rédigé le dimanche 5 avril 2026 à 16h

Estimation des risques pour le : LUNDI 06 AVRIL

NEIGE DE PRINTEMPS MAJORITAIRE, QUELQUES STRUCTURES DE PLAQUES ENCORE PRESENTES NORD D'ALTITUDE.

2

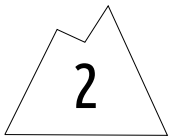

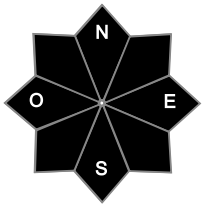

Indice de risque limité.

Départs spontanés : en neige humide au soleil.

Déclenchements provoqués : en neige humide au soleil, structures de plaques en Nord d'altitude.

Indices de risque : 5 très fort - 4 fort - 3 marqué - 2 limité - 1 faible -- En noir : les pentes les plus dangereuses

Stabilité du manteau neigeux

Situation avalancheuse typique : neige humide — neige ventée

Déclenchements spontanés :
Rares et peu importants en début de matinée, plus nombreux et prenant de l'ampleur au cours de la journée. Généralement sous forme de coulée ou d'avalanche de petite taille près des rochers et à proximité des zones déjà déneigées, de taille moyenne à rarement grande au plus chaud de l'après-midi. Départs linéaires de plaques de fond encore possibles en tous versants en partant d'une accumulation encore présente sur le haut du massif.

Déclenchements provoqués :
- au-dessus de 2500m, dans les expositions raides nord-ouest, nord et nord-est, des structures de plaques, souvent durcies juste en surface entre 2400 et 2600m, sont encore en place, formées lors des dernières chutes de neige (préférentiellement derrière crêtes, cols, et dans les combes déventées). Ces structures, une fois la neige ramollie en surface, restent facilement déclenchables par un seul skieur ou randonneur, et peuvent donner lieu à des avalanches de taille petite à moyenne (accumulations en cours de tassement mais encore parfois importantes). Une rare grande reste possible en déclenchant une telle structure au-dessus de 2600m entraînant par effet de cascade la neige encore mobilisable en contrebas.
- en dessous de 2500m des versants décrits ci-dessus et dans tous les autres secteurs, déclenchement facile de neige humide par un skieur ou randonneur au soleil et dans la douceur. Plutôt coulée ou petite avalanche attendue en matinée en est à sud-est, avalanche petite à parfois moyenne l'après-midi en sud à ouest, notamment à proximité des fissures.

Observables : travail du vent très visible en altitude, fissures ouvertes en est à sud-ouest sous 2200/2300m.

Autres : ponts de neige et corniches encore en place fragilisés au soleil.

Qualité de la neige

Enneigement : encore bon pour la saison, débutant encore vers 1500m en nord, 1700 à 1800m en sud même si les limites remontent progressivement en altitude.
État de la neige : neige de printemps dans une grande majorité des secteurs : à peine ressaisie sous 1800/1900m, plus ou moins bien regelée, dure et portante au-dessus au petit matin, ramollissant vite au soleil. Humidification un peu plus lente en versants nord mais accentuée et se faisant plus en profondeur par rapport aux jours précédents. Dans les pentes nord raides, neige légèrement croûtée en surface jusque 2500/2600m, encore sèche et un peu meuble au-dessus, s'humidifiant lentement mais sûrement au cours de la journée dans la douceur.

Aperçu météo pour le lundi 06 avril

	nuit	matin	après-midi	soir

Beau temps sec et doux, bon regel nocturne au-dessus de 1800/1900m.

Pluie-Neige				
Iso 0 °C	3 300 m	3 400 m	3 500 m	3 500 m
Vent 1500 m	10 km/h	10 km/h	10 km/h	15 km/h
Vent 3000 m	15 km/h	25 km/h	35 km/h	35 km/h

Épaisseur de neige hors-piste

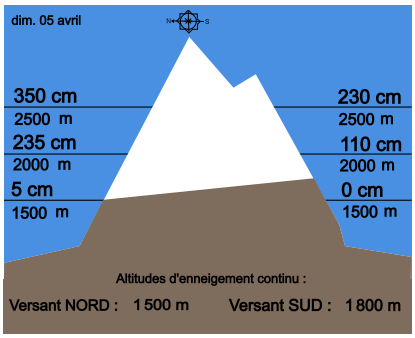

Précipitations à 1800 m

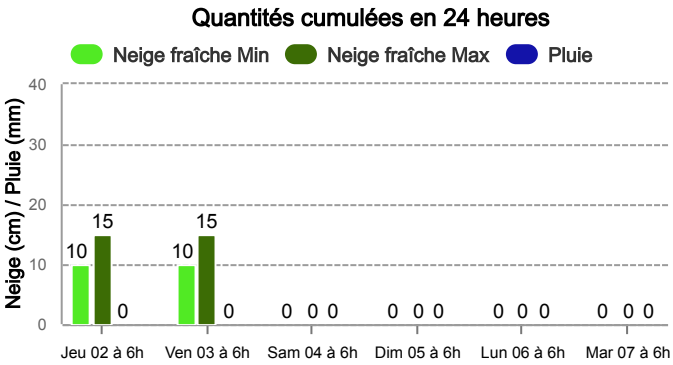

Tendance du mardi 07 avril

2

Indice de risque limité

On garde des conditions de neige de printemps : regel nocturne plus ou moins efficace, humidification marquée en journée au soleil et dans la douceur, encore un peu lente en Nord raides au-dessus de 2600m. Le risque restera limité (2).

Pour consulter la vigilance en cours, veuillez vous rendre sur le site https://vigilance.meteofrance.fr/fr

Météo-France - 73 avenue de Paris, 94165 Saint-Mandé cedex - Contact : contact@meteo.fr

Rédigé par Météo-France avec la contribution des observateurs du réseau nivo-météorologiques. Partenariat : ANMSM (Maires de Stations de Montagne), DSF (Domaines Skiables de France), ADSP (Directeurs de Pistes et de la Sécurité des Stations de Sports d'Hiver) et autres acteurs de la montagne.

Bulletin neige & avalanches par téléphone au 0 892 68 10 20 Service 0,35 € / min + prix appel

RÉPUBLIQUE FRANÇAISE
Liberté Égalité Fraternité

METEO FRANCE
À VOS CÔTÉS, DANS UN CLIMAT QUI CHANGE

Bulletin d'estimation du risque d'avalanche

(valable en dehors des pistes balisées et ouvertes)

MASSIF : Aspe Ossau

Rédigé le dimanche 5 avril 2026 à 16h

Conditions nivo-météo des 7 derniers jours

	lun. 30/03				mar. 31/03				mer. 01/04				jeu. 02/04				ven. 03/04				sam. 04/04				dim. 05/04			
	03h	09h	15h	21h	03h	09h	15h	21h	03h	09h	15h	21h	03h	09h	15h	21h	03h	09h	15h	21h	03h	09h	15h	21h	03h	09h	15h	21h
Météo																												
Vent (km/h)	50	50	55	50	55	50	50	60	70	80	85	80	75	75	70	60	35	35	25	20	15	25	25	30	30	20	20	20
à 3000m																												
Vent (km/h)	35	30	35	35	35	30	35	40	35	35	45	50	45	45	50	35	25	20	5	10	10	15	10	5	10	15	10	10
à 1500m																												

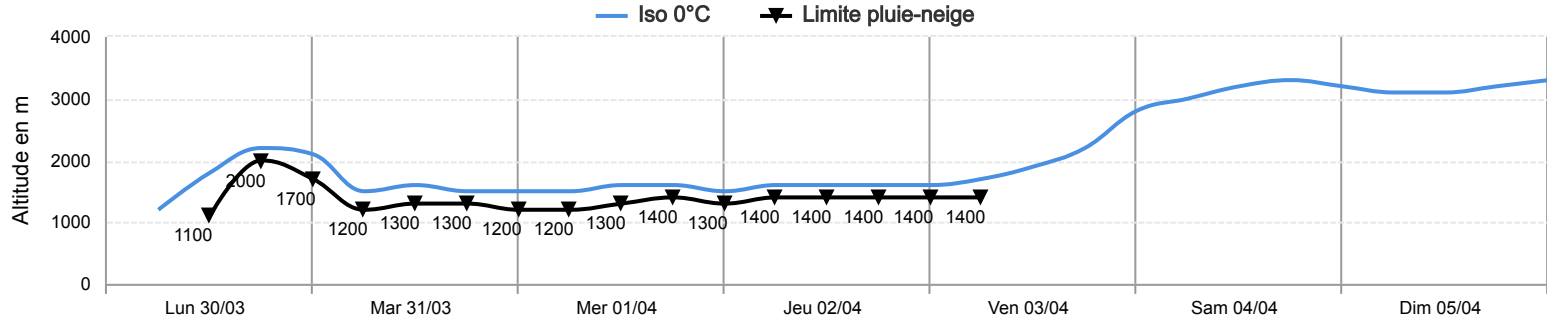

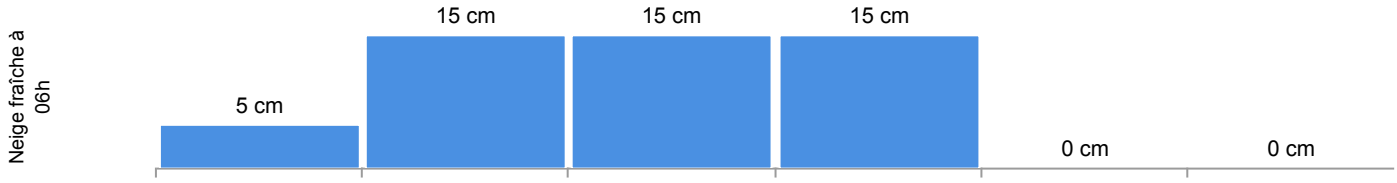

Risque d'avalanche	lun. 30/03	mar. 31/03	mer. 01/04	jeu. 02/04	ven. 03/04	sam. 04/04	dim. 05/04
	3	3	3	4	4	3	2

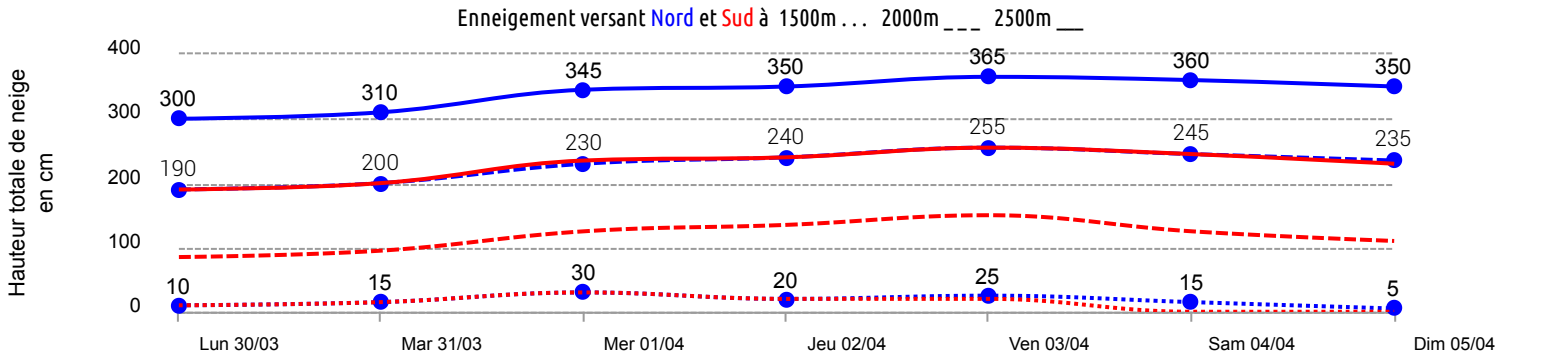

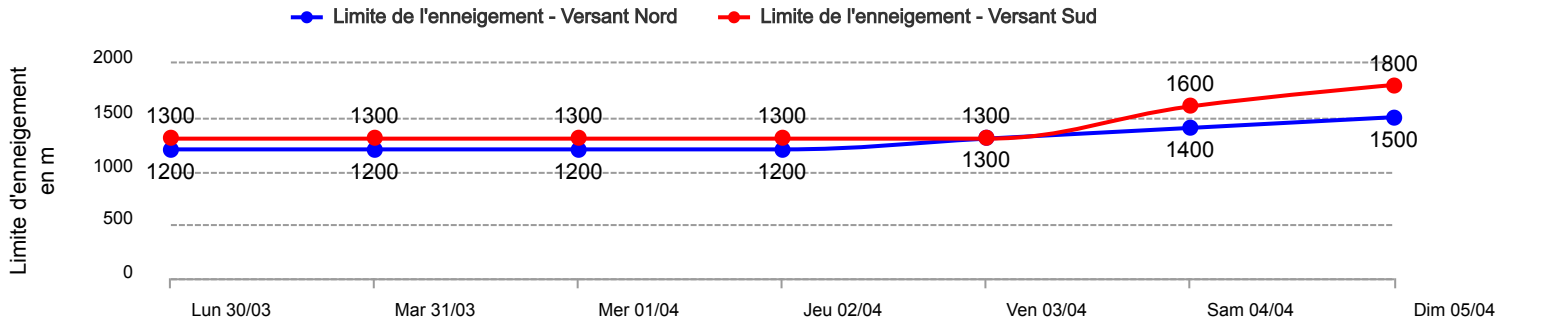

Pour consulter la vigilance en cours, veuillez vous rendre sur le site https://vigilance.meteofrance.fr/fr

Météo-France - 73 avenue de Paris, 94165 Saint-Mandé cedex - Contact : contact@meteo.fr

Bulletin neige & avalanches par téléphone au **0 892 68 10 20** Service 0,35 € / min + prix appel

Rédigé par Météo-France avec la contribution des observateurs du réseau nivo-météorologiques. Partenariat : ANMSM (Maires de Stations de Montagne), DSF (Domaines Skiables de France), ADSP (Directeurs de Pistes et de la Sécurité des Stations de Sports d'Hiver) et autres acteurs de la montagne.