RÉPUBLIQUE FRANÇAISE
Liberté Égalité Fraternité

METEO FRANCE
À VOS CÔTÉS, DANS UN CLIMAT QUI CHANGE

Bulletin d'estimation du risque d'avalanche
(valable en dehors des pistes balisées et ouvertes)

MASSIF : Bauges

Rédigé le dimanche 5 avril 2026 à 16h

Estimation des risques pour le : LUNDI 06 AVRIL

ACTIVITÉ HUMIDE EN HAUSSE, DÈS LE MATIN

2

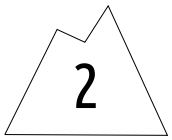

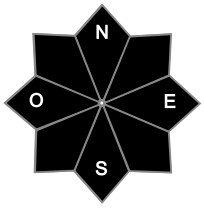

Indice de risque limité.

Départs spontanés : Coulées humides au soleil, avalanches de fond.

Déclenchements provoqués : Coulées de neige sous les skis.

Indices de risque : 5 très fort - 4 fort - 3 marqué - 2 limité - 1 faible -- En noir : les pentes les plus dangereuses

Stabilité du manteau neigeux

Situation avalancheuse typique : neige humide avalanches de fond

Départs spontanés :
* Quelques coulées de neige humide, tous versants ensoleillés. Dès les premiers rayons du soleil en versant est suite au mauvais regel de la nuit, les coulées suivent l'ensoleillement, même dans les versants NE/NO. Elles sont toutes altitudes et peuvent être plus épaisses en versant ouest, est et sud d'altitude. Généralement de taille 1, parfois 2 (petite à moyenne).
* À toute heure du jour et de la nuit, des fissures de reptations peuvent s'ouvrir et des avalanches de fond sont possibles sur les terrains lisses (pentes herbeuses, dalles rocheuses, etc). Taille 1 à 2.

Déclenchements provoqués :
* Coulées de neige humide sous les skis. Taille 1, 2.

Autre :
* Le redoux peut occasionner des chutes de corniches.

Qualité de la neige

Enneigement :
Bon pour un début avril. On peut chausser skis ou raquettes dès 1200/1300 m en versants N, et 1400/1600 m en versants S.

Qualité de la neige ce lundi :
* Regel médiocre, les pentes chauffent rapidement dans les versants ensoleillés.
* En nord, humidification en surface sous 2500 m voir plus haut sous les quelques nuages. Encore des accumulations de neige importantes, ou au contraire, des zones dures voire ravagées par le vent. Les crêtes et sommets sont les plus ravagées par le vent.
* Nombreuses corniches et accumulations/congères.

Aperçu météo pour le lundi 06 avril

nuit	matin	après-midi	soir

Couvert la nuit, de plus en plus ensoleillé en matinée. Encore chaud, 10°C à 2000 m.

Pluie-Neige				
Iso 0 °C	2 800 m	2 900 m	3 000 m	3 100 m
Vent 1500 m	15 km/h	10 km/h	10 km/h	5 km/h
Vent 2000 m	25 km/h	20 km/h	15 km/h	10 km/h

Épaisseur de neige hors-piste

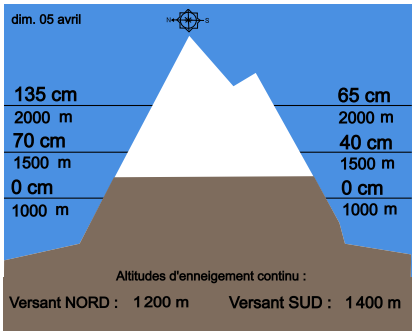

Précipitations à 1800 m

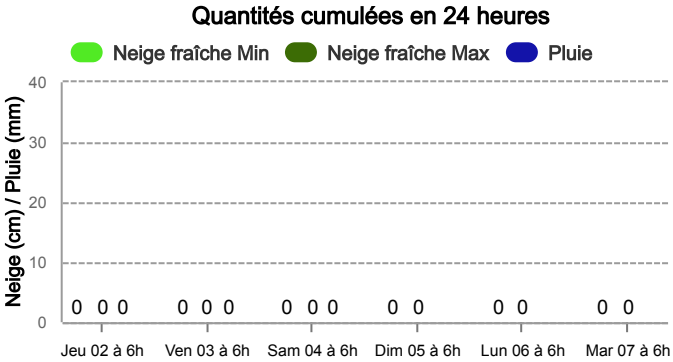

Tendance du mardi 07 avril

2

Indice de risque limité

Bon regel la nuit de lundi/mardi, mais l'isotherme 0°C grimpe à 3200 m en journée, les instabilités liées à la neige humide continuent.

Pour consulter la vigilance en cours, veuillez vous rendre sur le site https://vigilance.meteofrance.fr/fr

Météo-France - 73 avenue de Paris, 94165 Saint-Mandé cedex - Contact : contact@meteo.fr

Rédigé par Météo-France avec la contribution des observateurs du réseau nivo-météorologiques. Partenariat : ANMSM (Maires de Stations de Montagne), DSF (Domaines Skiables de France), ADSP (Directeurs de Pistes et de la Sécurité des Stations de Sports d'Hiver) et autres acteurs de la montagne.

Bulletin neige & avalanches par téléphone au
0 892 68 10 20 Service 0,35 € / min + prix appel

RÉPUBLIQUE FRANÇAISE
Liberté Égalité Fraternité

METEO FRANCE
À VOS CÔTÉS, DANS UN CLIMAT QUI CHANGE

Bulletin d'estimation du risque d'avalanche

(valable en dehors des pistes balisées et ouvertes)

MASSIF : Bauges

Rédigé le dimanche 5 avril 2026 à 16h

Conditions nivo-météo des 7 derniers jours

	lun. 30/03				mar. 31/03				mer. 01/04				jeu. 02/04				ven. 03/04				sam. 04/04				dim. 05/04			
	03h	09h	15h	21h	03h	09h	15h	21h	03h	09h	15h	21h	03h	09h	15h	21h	03h	09h	15h	21h	03h	09h	15h	21h	03h	09h	15h	21h
Météo																												
Vent (km/h)	30	25	35	30	45	50	60	50	50	50	50	40	40	50	50	50	40	30	20	15	20	20	10	15	15	20	35	25
à 2000m																												
Vent (km/h)	15	15	30	30	35	40	50	40	40	40	40	30	20	30	40	40	30	20	15	10	15	10	5	5	10	15	20	15
à 1500m																												

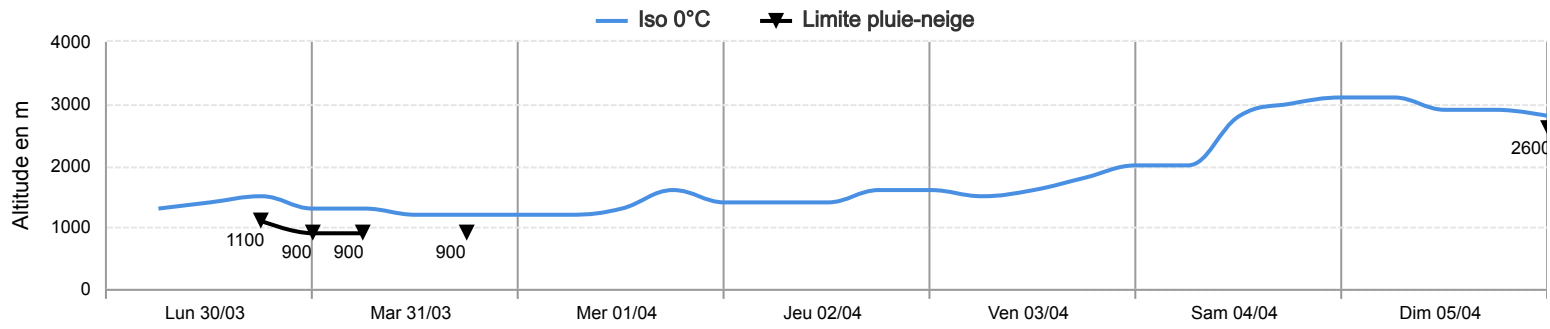

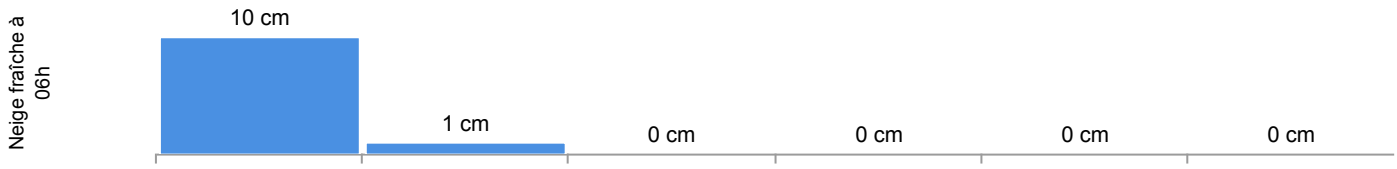

Risque d'avalanche	lun. 30/03	mar. 31/03	mer. 01/04	jeu. 02/04	ven. 03/04	sam. 04/04	dim. 05/04
	2	2	2	2	2	2	2

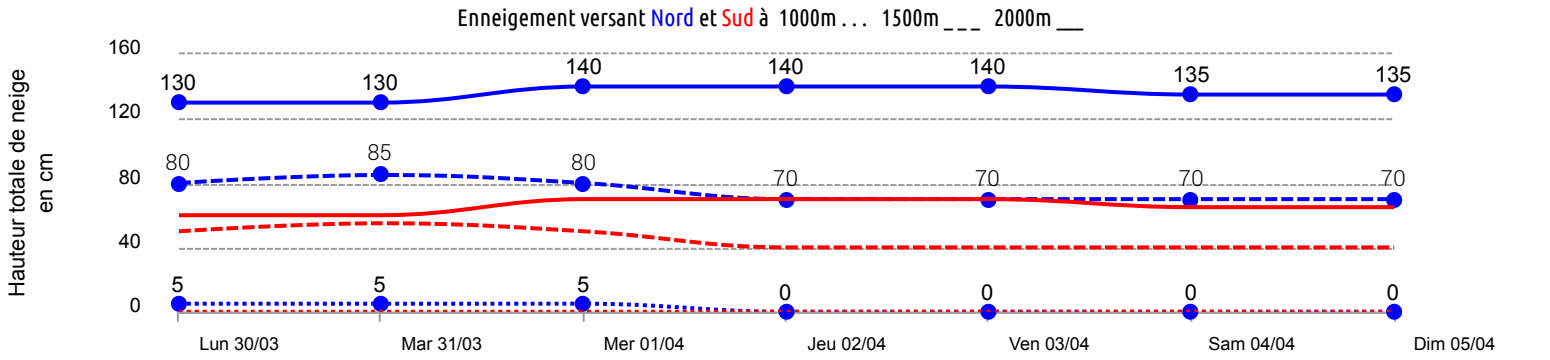

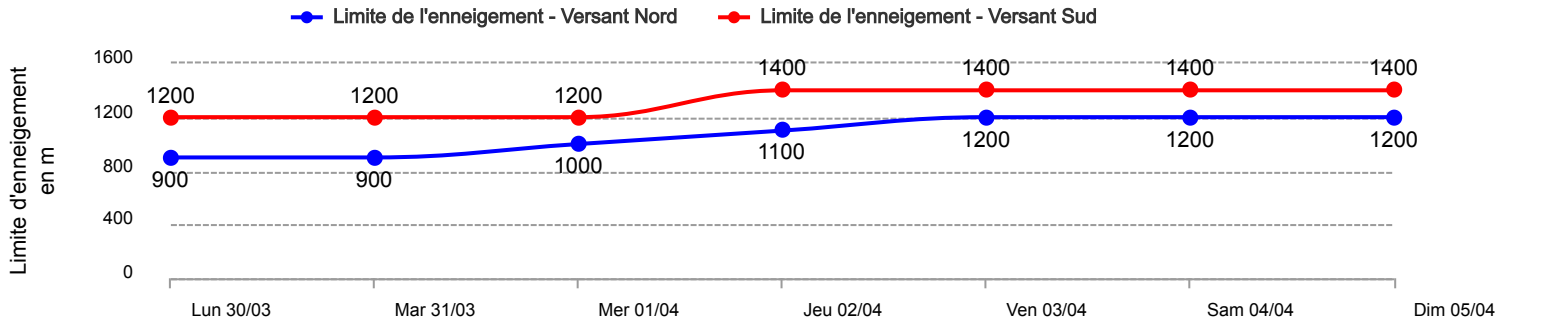

Pour consulter la vigilance en cours, veuillez vous rendre sur le site https://vigilance.meteofrance.fr/fr

Météo-France - 73 avenue de Paris, 94165 Saint-Mandé cedex - Contact : contact@meteo.fr

Rédigé par Météo-France avec la contribution des observateurs du réseau nivo-météorologiques. Partenariat : ANMSM (Maires de Stations de Montagne), DSF (Domaines Skiables de France), ADSP (Directeurs de Pistes et de la Sécurité des Stations de Sports d'Hiver) et autres acteurs de la montagne.

Bulletin neige & avalanches par téléphone au

0 892 68 10 20 Service 0,35 € / min + prix appel