Bulletin d'estimation du risque d'avalanche

(valable en dehors des pistes balisées et ouvertes)

MASSIF : Cinto Rotondo

Rédigé le dimanche 5 avril 2026 à 16h

Estimation des risques pour le : LUNDI 06 AVRIL

DÉPARTS EN NEIGE HUMIDE EN JOURNÉE

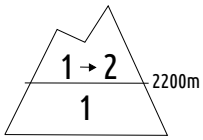

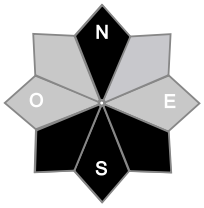

Au-dessus de 2200m indice de risque faible évoluant en limité, plus bas indice faible.

Départs spontanés : Coulées et avalanches de neige humide dans les pentes raides durant les heures les plus chaudes de la journée

Déclenchements provoqués : Très rares plaques à vent pouvant persister en altitude, difficiles à solliciter

Indices de risque : 5 très fort - 4 fort - 3 marqué - 2 limité - 1 faible -- En noir : les pentes les plus dangereuses

Stabilité du manteau neigeux

Situation avalancheuse typique : neige humide

Départs spontanés : Avec la hausse des températures et le généreux ensoleillement, des départs en neige humide sont attendus durant la journée, surtout en versants raides bien ensoleillés, au fil de la course du soleil. Au-dessus de 2200 m, l'humidification gagnant en profondeur dans la neige récente, des avalanches de taille moyenne sont à attendre, y compris dans les couloirs Nord bien chargés.

Déclenchements provoqués : Aux heures les plus chaudes de la journée, un skieur coupant une pente raide peut déclencher une coulée de neige humide. De fines plaques à vent peuvent aussi persister en versants ombragés en haute altitude, mais elles deviennent difficiles à solliciter.

Autres : Présence de corniches, susceptibles de rompre à cause des conditions printanières. Persistance de surfaces dures et glacées, pouvant être recouvertes de quelques centimètres de neige récente humide.

Qualité de la neige

Qualification de l'enneigement : L'enneigement est excellent pour la saison et même excédentaire au-dessus de 1700 m. Sur la Maniccia, à 2400 m d'altitude dans le massif du Rotondo, on relève 3m10 de hauteur de neige totale.

Limite d'enneigement skiable : 1500 à 1600m.

État de la neige : Évolution progressive vers une neige de printemps en toutes orientations. En Nord en haute altitude, il reste quelques surfaces de neige sèche, souvent dure, dans les rares pentes raides qui restent ombragées. Ailleurs, l'humidification gagne en profondeur tandis que le regel nocturne est moins efficace. Toutefois, les surfaces dures peuvent être fréquentes le matin en altitude. Dans les orientations Sud, le manteau neigeux est généralement humidifié sur toute son épaisseur, au moins jusqu'à 2200 m. En moyenne montagne, la croûte de regel est quasiment inexistante le matin, alors que la neige devient molle voire pourrie l'après-midi.

Aperçu météo pour le lundi 06 avril

	nuit	matin	après-midi	soir
Beau temps, printanier. Isotherme zéro degré au-dessus de 3000m, températures élevées.				
Pluie-Neige				
Iso 0 °C	3 100 m	3 100 m	3 200 m	3 300 m
Vent 1500 m	→ 20 km/h	→ 15 km/h	↗ 15 km/h	→ 20 km/h
Vent 3000 m	↘ 25 km/h	↘ 20 km/h	→ 20 km/h	→ 20 km/h

Épaisseur de neige hors-piste

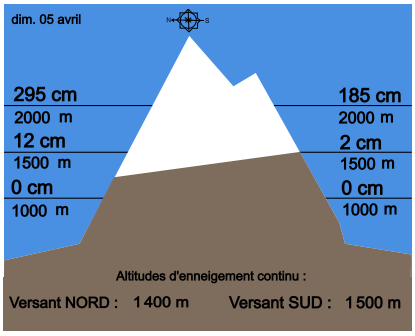

Précipitations à 1800 m

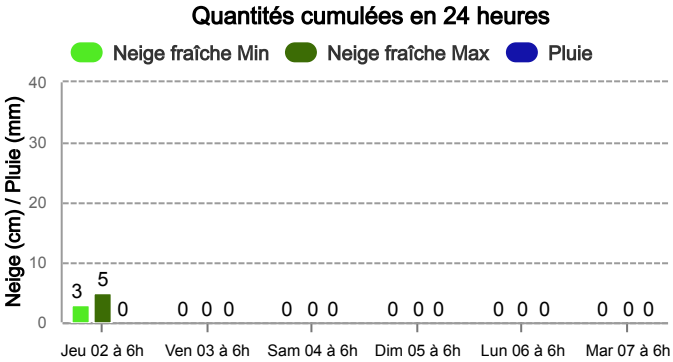

Tendance du mardi 07 avril

Indice de risque limité

Durant la journée, au-dessus de 2200 m, l'humidification gagnant en profondeur dans la neige récente, des avalanches de taille moyenne sont à attendre. Ailleurs, coulées de neige humide ou départs sous les skis dans les pentes raides. Maintien d'un risque limité.

Pour consulter la vigilance en cours, veuillez vous rendre sur le site https://vigilance.meteofrance.fr/fr

Météo-France - 73 avenue de Paris, 94165 Saint-Mandé cedex - Contact : contact@meteo.fr

Rédigé par Météo-France avec la contribution des observateurs du réseau nivo-météorologiques. Partenariat : ANMSM (Maires de Stations de Montagne), DSF (Domaines Skiables de France), ADSP (Directeurs de Pistes et de la Sécurité des Stations de Sports d'Hiver) et autres acteurs de la montagne.

Bulletin neige & avalanches par téléphone au
0 892 68 10 20 Service 0,35 € / min + prix appel

Bulletin d'estimation du risque d'avalanche

(valable en dehors des pistes balisées et ouvertes)

MASSIF : Cinto Rotondo

Rédigé le dimanche 5 avril 2026 à 16h

Conditions nivo-météo des 7 derniers jours

	lun. 30/03				mar. 31/03				mer. 01/04				jeu. 02/04				ven. 03/04				sam. 04/04				dim. 05/04			
	03h	09h	15h	21h	03h	09h	15h	21h	03h	09h	15h	21h	03h	09h	15h	21h	03h	09h	15h	21h	03h	09h	15h	21h	03h	09h	15h	21h
Météo																												
Vent (km/h)	25	15	30	40	70	70	70	95	80	70	45	60	60	45	40	50	60	50	40	25	40	40	30	40	25	15	10	15
à 3000m																												
Vent (km/h)	25	15	30	30	40	60	30	70	95	100	50	55	50	40	40	35	35	30	25	15	10	15	15	15	15	5	10	10
à 1500m																												

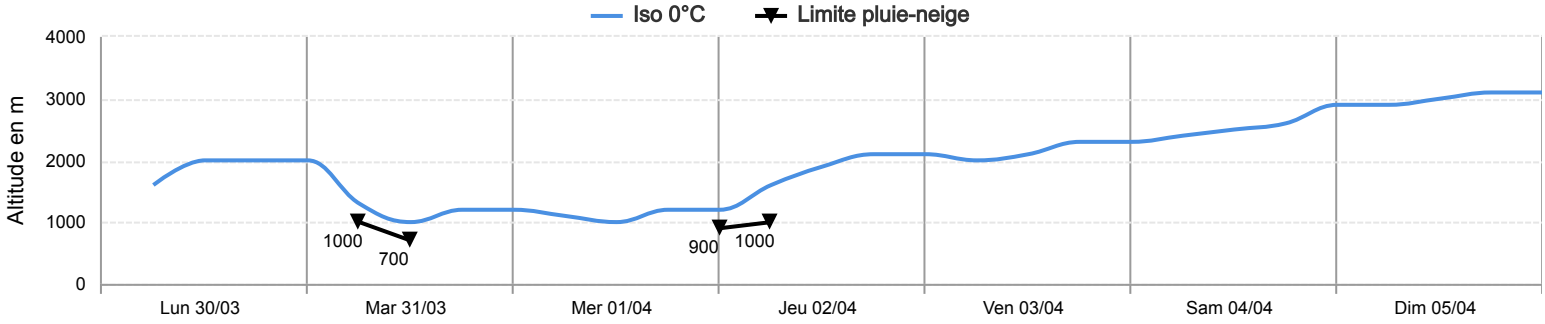

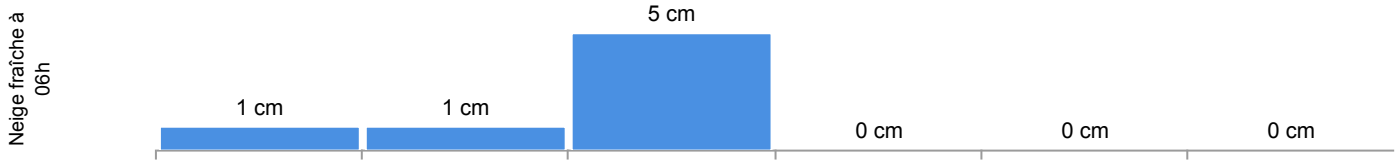

Risque d'avalanche	lun. 30/03	mar. 31/03	mer. 01/04	jeu. 02/04	ven. 03/04	sam. 04/04	dim. 05/04
	2	2	2	2	2	2	2

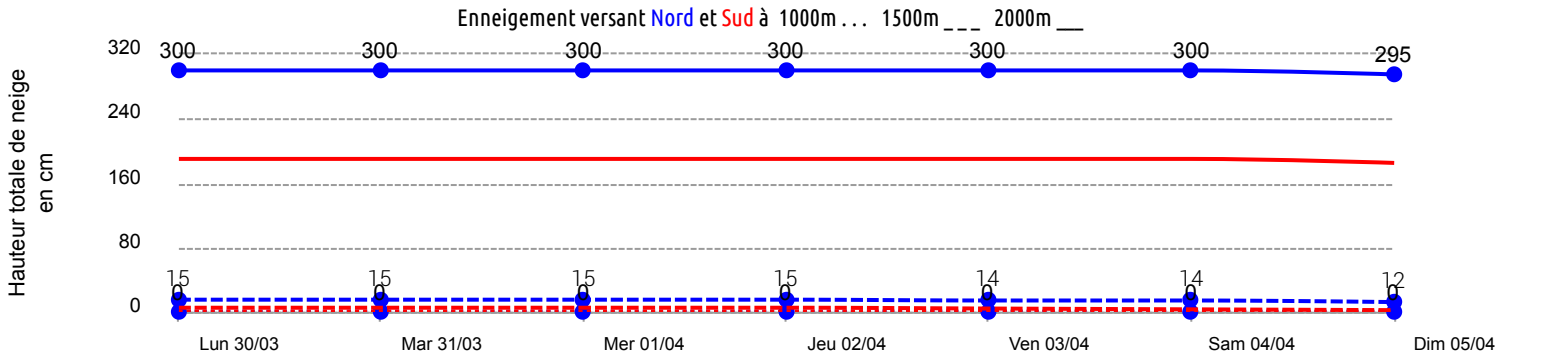

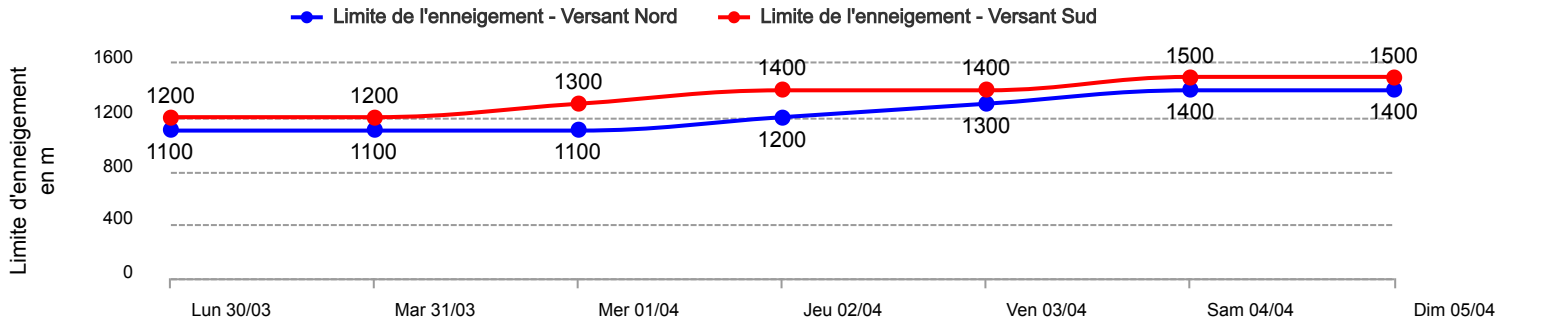

Pour consulter la vigilance en cours, veuillez vous rendre sur le site https://vigilance.meteofrance.fr/fr

Météo-France - 73 avenue de Paris, 94165 Saint-Mandé cedex - Contact : contact@meteo.fr

Rédigé par Météo-France avec la contribution des observateurs du réseau nivo-météorologiques. Partenariat : ANMSM (Maires de Stations de Montagne), DSF (Domaines Skiables de France), ADSP (Directeurs de Pistes et de la Sécurité des Stations de Sports d'Hiver) et autres acteurs de la montagne.

Bulletin neige & avalanches par téléphone au

0 892 68 10 20 Service 0,35 € / min + prix appel