RÉPUBLIQUE FRANÇAISE
Liberté Égalité Fraternité

METEO FRANCE
À VOS CÔTÉS, DANS UN CLIMAT QUI CHANGE

Bulletin d'estimation du risque d'avalanche

(valable en dehors des pistes balisées et ouvertes)

MASSIF : Couserans

Rédigé le dimanche 5 avril 2026 à 16h

Estimation des risques pour le : LUNDI 06 AVRIL

POURSUITE DE L'HUMIDIFICATION ; QUELQUES PLAQUES ENCORE PRÉSENTES EN VERSANTS FROIDS D'ALTITUDE

2

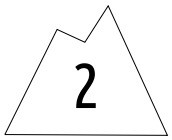

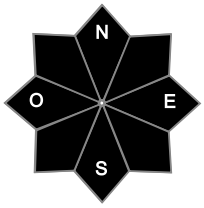

Indice de risque limité.

Départs spontanés : En neige humide au fil de l'ensoleillement

Déclenchements provoqués : En versants froids d'altitude, de moins en moins probables

Indices de risque : 5 très fort - 4 fort - 3 marqué - 2 limité - 1 faible -- En noir : les pentes les plus dangereuses

Stabilité du manteau neigeux

Situation avalancheuse typique : neige humide neige ventée

Départs spontanés :
- Au cours de la journée, dans les pentes raides, des départs ponctuels en neige humide de taille petite à moyenne sont de plus en plus probables au fil de l'ensoleillement, quasiment en toutes orientations et gagnant de plus en plus en altitude. Seules les faces nord raides d'altitude sont susceptibles encore d'y échapper. Ces départs emporteront la neige tombée depuis cette semaine. Les plus gros volumes sont attendus principalement dans les versants nord-est à sud, plus chargés.
Observables : neige humide sans cohésion

- En dessous de 2000m, des avalanches de fond sont aussi possibles dans les pentes herbeuses ou sur des dalles rocheuses lisses récemment recouvertes par les chutes de la semaine. Elles seront de taille petite à moyenne.
Observables : fissures, reptations récentes

Déclenchements provoqués :
- Au-dessus de 2400m, dans les versants nord-ouest, nord et nord-est, des structures de plaques peuvent encore subsister dans la neige récente. Bien qu'en cours de stabilisation, elles peuvent éventuellement être déclenchables au passage d'un pratiquant. Elles peuvent occasionner des avalanches moyennes, voire grandes dans les zones de forte accumulation.
Observables : Avalanches récentes, aspect ventée de la surface et accumulations locales, fissures éventuelles devant les skis.

- Ailleurs, un pratiquant peut provoquer un départ ponctuel en surface dans la neige humide en coupant une pente raide déjà bien humidifiée.

Autre : Corniches volumineuses proches des crêtes.

Qualité de la neige

Enneigement :
L'enneigement est excellent pour la saison, un des meilleurs des 30 dernières années. Des cumuls conséquents voire remarquables en altitude côtoient des crêtes et sommets exposés au vent d'ouest à nord-ouest souvent assez dégarnis. Même si la neige est visible dès 1300 m dans certains secteurs ombragés et en fond de vallée, il est envisageable de chausser les skis plutôt à partir de 1400/1600 m sur une couche de neige qui devient rapidement plus épaisse.

Qualité de la neige :
Au petit matin, on attend un regel efficace avec de la neige dure et portante au-dessus de 2200/2400m. Plus bas, le regel devrait être peu efficace et probablement même inexistant sous 1800m. On pourra encore trouver de la neige légère et poudreuse dans de rares combes d'altitude abritées du vent en secteurs nord-ouest à nord-est. Là où le vent a soufflé, la neige est plus dure et tassée.
En journée, l'humidification continue à progresser en altitude en nord pratiquement jusqu'en haut des massifs. On trouvera une couche profonde de neige humide et gorgée d'eau au soleil dans les versants Est à Ouest en passant par le Sud, au fil de l'ensoleillement, ainsi que dans les versants nord en dessous de 2200m environ.

Aperçu météo pour le lundi 06 avril

	nuit	matin	après-midi	soir
Grand beau; vent faible				
Pluie-Neige				
Iso 0 °C	3 300 m	3 300 m	3 400 m	3 500 m
Vent 2000 m	10 km/h	5 km/h	10 km/h	10 km/h
Vent 3000 m	15 km/h	10 km/h	15 km/h	15 km/h

Pour consulter la vigilance en cours, veuillez vous rendre sur le site https://vigilance.meteofrance.fr/fr

Météo-France - 73 avenue de Paris, 94165 Saint-Mandé cedex - Contact : contact@meteo.fr

Rédigé par Météo-France avec la contribution des observateurs du réseau nivo-météorologiques. Partenariat : ANMSM (Maires de Stations de Montagne), DSF (Domaines Skiables de France), ADSP (Directeurs de Pistes et de la Sécurité des Stations de Sports d'Hiver) et autres acteurs de la montagne.

Bulletin neige & avalanches par téléphone au
0 892 68 10 20 Service 0,35 € / min + prix appel

Bulletin d'estimation du risque d'avalanche

(valable en dehors des pistes balisées et ouvertes)

MASSIF : Couserans

Rédigé le dimanche 5 avril 2026 à 16h

Épaisseur de neige hors-piste

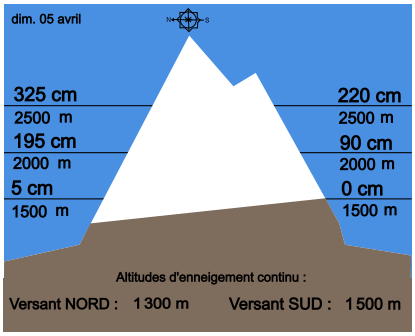

Précipitations à 1800 m

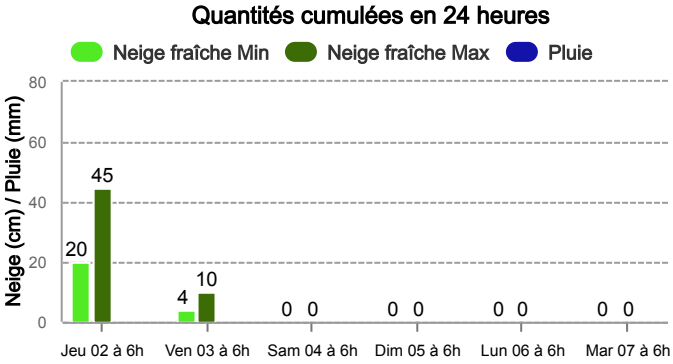

Tendance du mardi 07 avril

Indice de risque limité

Peu d'évolution. Conditions de neige de printemps sous un généreux soleil d'avril.

Pour consulter la vigilance en cours, veuillez vous rendre sur le site https://vigilance.meteofrance.fr/fr

Météo-France - 73 avenue de Paris, 94165 Saint-Mandé cedex - Contact : contact@meteo.fr

Rédigé par Météo-France avec la contribution des observateurs du réseau nivo-météorologiques. Partenariat : ANMSM (Maires de Stations de Montagne), DSF (Domaines Skiables de France), ADSP (Directeurs de Pistes et de la Sécurité des Stations de Sports d'Hiver) et autres acteurs de la montagne.

Bulletin neige & avalanches par téléphone au

0 892 68 10 20 Service 0,35 € / min + prix appel

Bulletin d'estimation du risque d'avalanche

(valable en dehors des pistes balisées et ouvertes)

MASSIF : Couserans

Rédigé le dimanche 5 avril 2026 à 16h

Conditions nivo-météo des 7 derniers jours

	lun. 30/03				mar. 31/03				mer. 01/04				jeu. 02/04				ven. 03/04				sam. 04/04				dim. 05/04			
	03h	09h	15h	21h	03h	09h	15h	21h	03h	09h	15h	21h	03h	09h	15h	21h	03h	09h	15h	21h	03h	09h	15h	21h	03h	09h	15h	21h
Météo																												
Vent (km/h)	65	55	60	70	60	60	70	75	75	75	80	85	80	70	70	70	60	50	45	40	40	35	25	20	15	10	15	15
à 3000m																												
Vent (km/h)	35	25	40	45	45	35	40	45	45	45	55	65	55	45	50	50	35	20	20	20	20	15	15	15	10	5	10	10
à 2000m																												

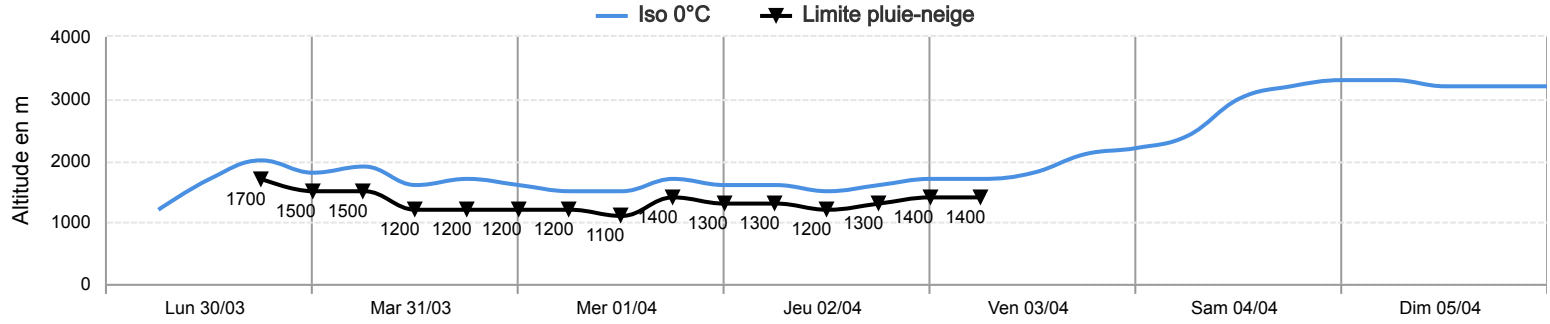

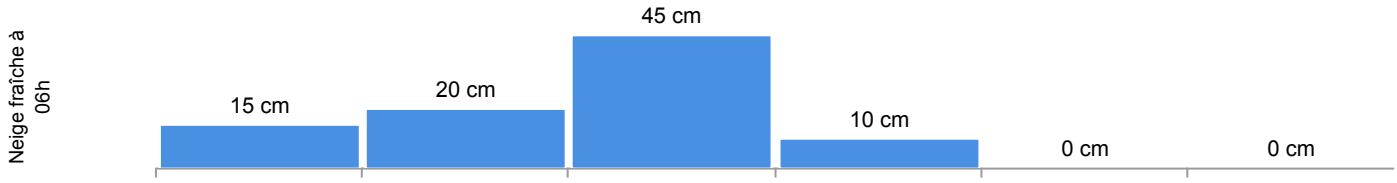

Risque d'avalanche	lun. 30/03	mar. 31/03	mer. 01/04	jeu. 02/04	ven. 03/04	sam. 04/04	dim. 05/04
	3	3	4	4	4	3	2

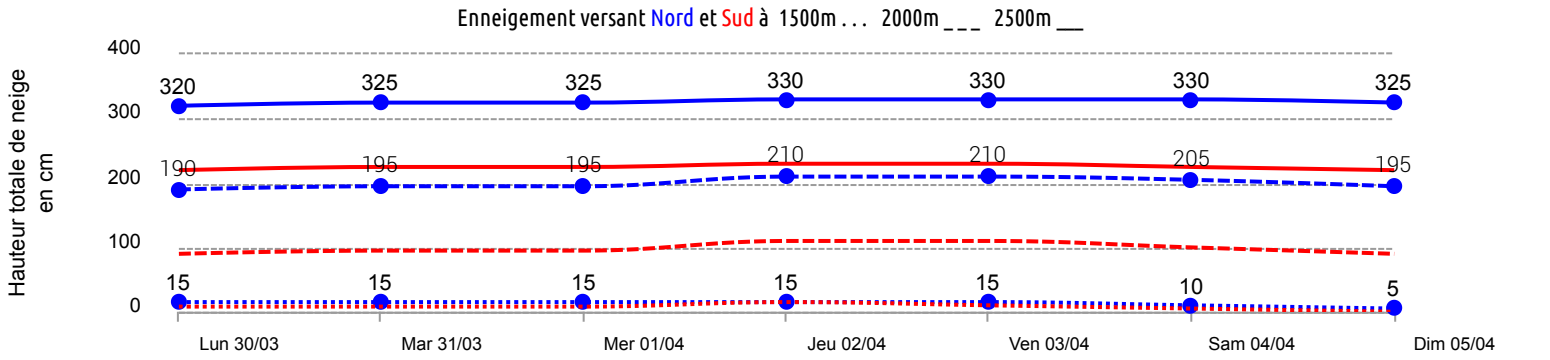

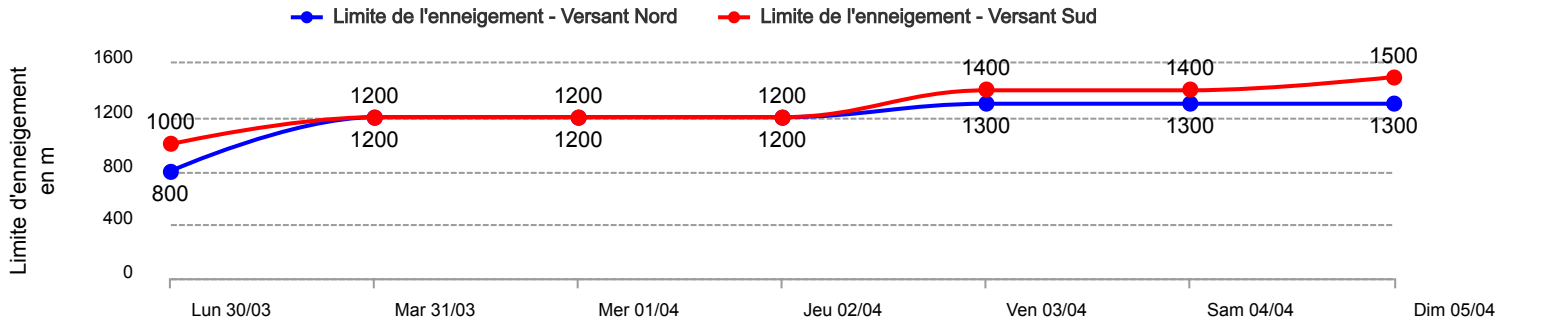

Pour consulter la vigilance en cours, veuillez vous rendre sur le site https://vigilance.meteofrance.fr/fr

Météo-France - 73 avenue de Paris, 94165 Saint-Mandé cedex - Contact : contact@meteo.fr

Bulletin neige & avalanches par téléphone au

0 892 68 10 20 Service 0,35 € / min + prix appel

Rédigé par Météo-France avec la contribution des observateurs du réseau nivo-météorologiques. Partenariat : ANMSM (Maires de Stations de Montagne), DSF (Domaines Skiables de France), ADSP (Directeurs de Pistes et de la Sécurité des Stations de Sports d'Hiver) et autres acteurs de la montagne.