Bulletin d'estimation du risque d'avalanche
(valable en dehors des pistes balisées et ouvertes)

MASSIF : Haut-Var Haut-Verdon

Rédigé le dimanche 5 avril 2026 à 16h

Estimation des risques pour le : LUNDI 06 AVRIL

QUELQUES DÉPARTS SUPERFICIELS EN NEIGE HUMIDE

2

1 → 2

N O E S

Indice de risque faible évoluant en limité.

Départs spontanés : quelques départs superficiels au soleil.

Déclenchements provoqués : départs sous les skis en neige humide, notamment en altitude.

Indices de risque : 5 très fort - 4 fort - 3 marqué - 2 limité - 1 faible -- En noir : les pentes les plus dangereuses

Stabilité du manteau neigeux

Situation avalancheuse typique : neige humide

Départs spontanés : peu probables au levé du jour, puis quelques petits départs superficiels de neige humide reprennent rapidement avec le retour du soleil. Avalanches de petite taille (taille 1), rarement moyenne (taille 2).

Déclenchements provoqués :
- un skieur évoluant tardivement dans une pente humidifiée peut provoquer un petit départ ponctuel de neige humide, voir un départ linéaire par déstabilisation d'une ancienne plaque à vent humidifiée proche des crêtes ou dans certains versants ombragés. Avalanches généralement de petite taille (taille 1), rarement moyenne (taille 2) en cas de départ linéaire.

Qualité de la neige

Enneigement plutôt excédentaire pour un début avril.
Hauteurs de neige observées : vers 2000 m, 167 cm dans le vallon de Valdemars, 101 cm à la Sanguinière dans le Haut Var.

Enneigement skiable : vers 1500/1600 m en terrain favorable en ubacs, 1800/1900 m en adrets peu pentus.

État de la neige en surface : manteau neigeux printanier avec un regel superficiel le matin, s'humidifiant rapidement en journée. On trouve localement un peu de neige plus froide et meuble en ubacs bien abrités du vent au-dessus de 2400/2600 m. Neige fortement travaillée par le vent en altitude.

Aperçu météo pour le lundi 06 avril

nuit	matin	après-midi	soir

Temps sec ensoleillé, malgré des passages de nuages élevés parfois épais en début de journée et quelques cumuls l'après-midi.

Pluie-Neige				
Iso 0 °C	3 300 m	3 200 m	3 200 m	3 300 m
Vent 2000 m	↘ 15 km/h	↘ 15 km/h	↘ 20 km/h	↓ 10 km/h
Vent 3000 m	↘ 30 km/h	↘ 25 km/h	↘ 20 km/h	↘ 20 km/h

Épaisseur de neige hors-piste

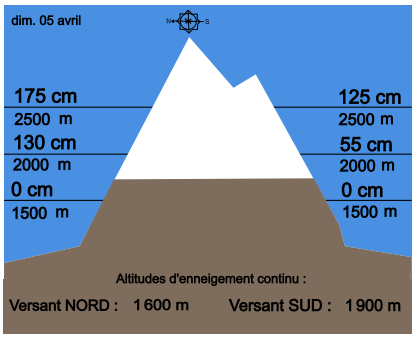

Précipitations à 1800 m

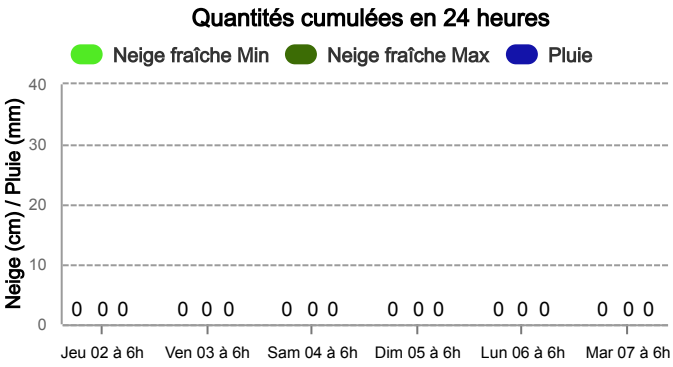

Tendance du mardi 07 avril

2

Indice de risque limité

Maintien d'un risque limité. L'humidification du manteau neigeux se poursuit lentement.

Pour consulter la vigilance en cours, veuillez vous rendre sur le site https://vigilance.meteofrance.fr/fr

Météo-France - 73 avenue de Paris, 94165 Saint-Mandé cedex - Contact : contact@meteo.fr

Rédigé par Météo-France avec la contribution des observateurs du réseau nivo-météorologiques. Partenariat : ANMSM (Maires de Stations de Montagne), DSF (Domaines Skiables de France), ADSP (Directeurs de Pistes et de la Sécurité des Stations de Sports d'Hiver) et autres acteurs de la montagne.

Bulletin neige & avalanches par téléphone au 0 892 68 10 20 Service 0,35 € / min + prix appel

RÉPUBLIQUE FRANÇAISE
Liberté Égalité Fraternité

METEO FRANCE
À VOS CÔTÉS, DANS UN CLIMAT QUI CHANGE

Bulletin d'estimation du risque d'avalanche

(valable en dehors des pistes balisées et ouvertes)

MASSIF : Haut-Var Haut-Verdon

Rédigé le dimanche 5 avril 2026 à 16h

Conditions nivo-météo des 7 derniers jours

	lun. 30/03				mar. 31/03				mer. 01/04				jeu. 02/04				ven. 03/04				sam. 04/04				dim. 05/04			
	03h	09h	15h	21h	03h	09h	15h	21h	03h	09h	15h	21h	03h	09h	15h	21h	03h	09h	15h	21h	03h	09h	15h	21h	03h	09h	15h	21h
Météo																												
Vent (km/h)	30	55	75	120	80	40	40	75	80	60	50	45	50	25	25	20	15	25	25	25	15	10	15	10	10	15	25	30
à 3000m	↓	↓	↓	↓	↓	↙	↙	↙	↙	↙	↙	↙	↙	↙	↙	↓	↓	↙	↓	↙	↙	↙	→	↓	↓	→	→	↘
Vent (km/h)	15	20	20	80	45	30	35	65	70	45	40	35	35	20	20	20	15	15	15	10	10	5	15	5	5	10	15	15
à 2000m	↙	↘	↘	↓	↓	↓	↓	↙	↓	↓	↙	↓	↙	↓	↓	↓	↓	↙	↙	↙	↙	↖	↑	↙	→	→	→	↘

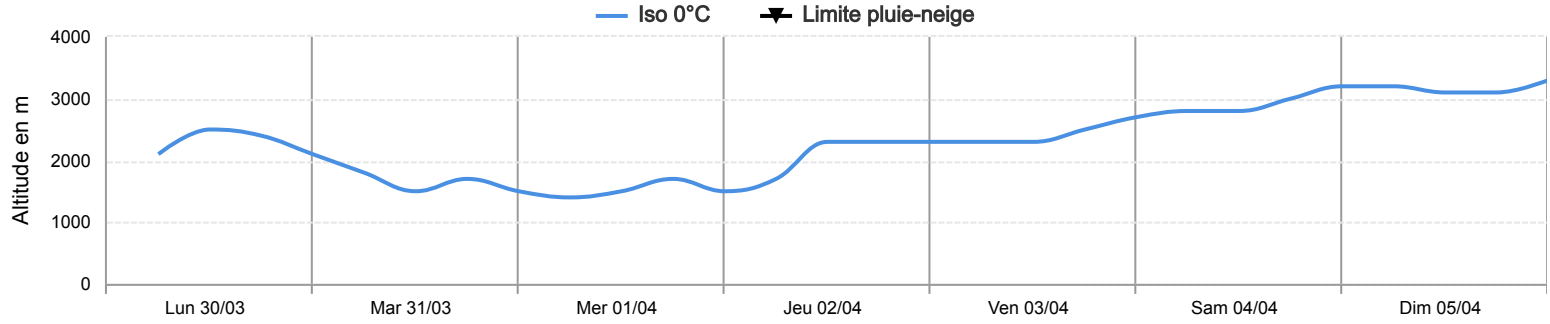

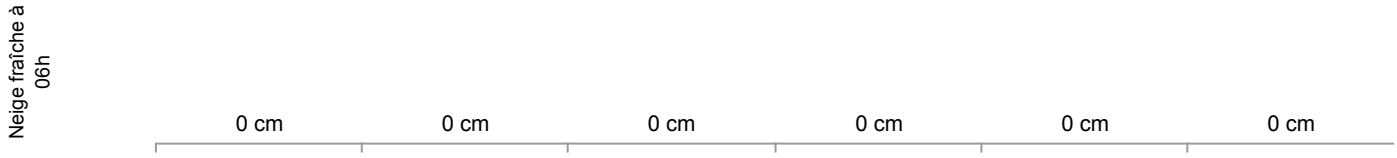

Risque d'avalanche	lun. 30/03	mar. 31/03	mer. 01/04	jeu. 02/04	ven. 03/04	sam. 04/04	dim. 05/04
	2	2	2	1	1	2	2

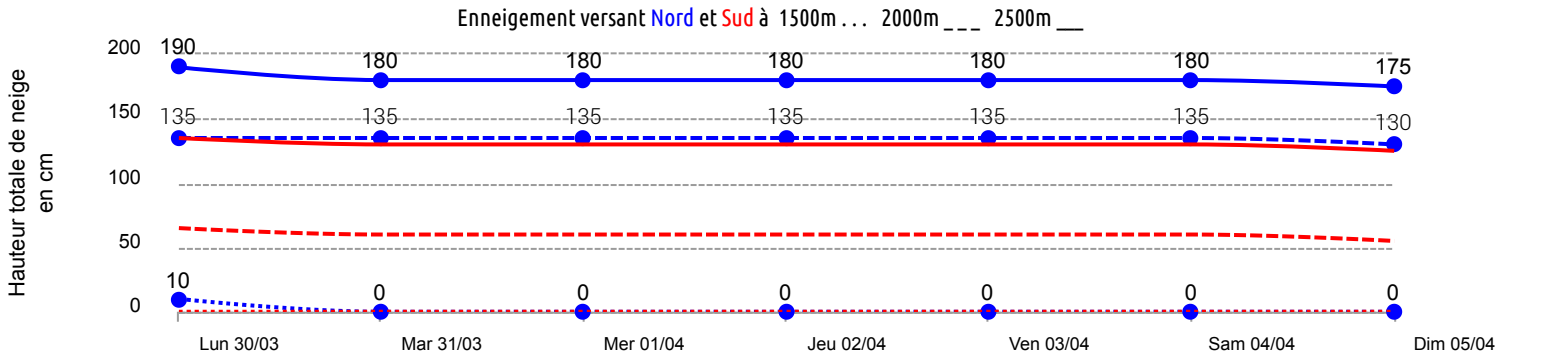

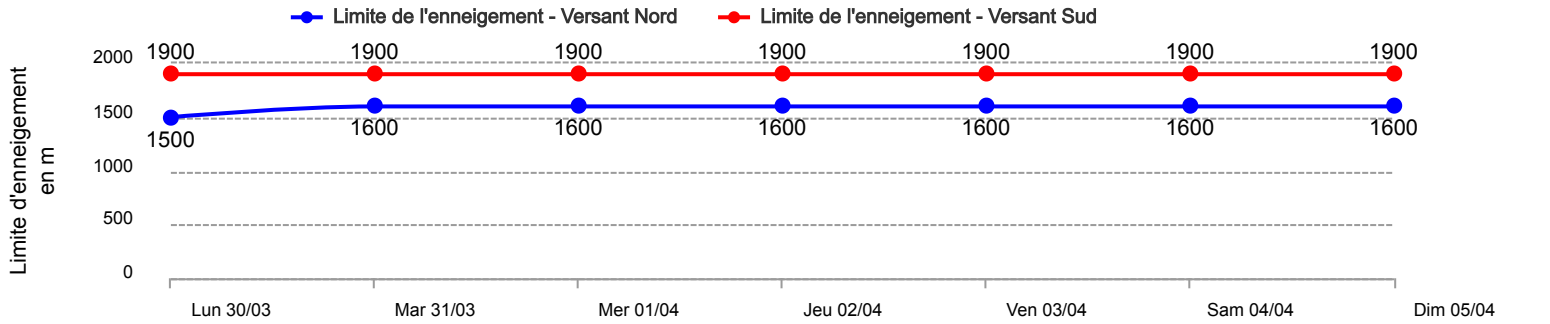

Pour consulter la vigilance en cours, veuillez vous rendre sur le site https://vigilance.meteofrance.fr/fr

Météo-France - 73 avenue de Paris, 94165 Saint-Mandé cedex - Contact : contact@meteo.fr

Rédigé par Météo-France avec la contribution des observateurs du réseau nivo-météorologiques. Partenariat : ANMSM (Maires de Stations de Montagne), DSF (Domaines Skiables de France), ADSP (Directeurs de Pistes et de la Sécurité des Stations de Sports d'Hiver) et autres acteurs de la montagne.

Bulletin neige & avalanches par téléphone au

0 892 68 10 20 Service 0,35 € / min + prix appel