Bulletin d'estimation du risque d'avalanche
(valable en dehors des pistes balisées et ouvertes)

MASSIF : Queyras

Rédigé le dimanche 5 avril 2026 à 16h

Estimation des risques pour le : LUNDI 06 AVRIL

AVALANCHES DE NEIGE HUMIDE AU SOLEIL, PONCTUELLEMENT GRANDES - RARES PLAQUES EN NEIGE FROIDE EN UBACS D'ALTITUDE

2

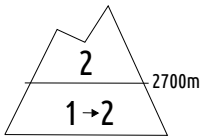

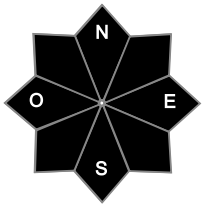

Au-dessus de 2700m indice de risque limité, plus bas indice faible évoluant en limité.

Départs spontanés : en neige humide au fil de l'ensoleillement - départs ponctuels, plus rarement linéaires.

Déclenchements provoqués : rares plaques en altitude ou neige humide sous les skis.

Indices de risque : 5 très fort - 4 fort - 3 marqué - 2 limité - 1 faible -- En noir : les pentes les plus dangereuses

Stabilité du manteau neigeux

Situation avalancheuse typique : neige humide — neige ventée

Départs spontanés : activité en neige humide en hausse au fil de la journée en suivant la course du soleil, en particulier dans les pentes raides près des rochers. Départs ponctuels en poire, mais parfois linéaires, engendrant fréquemment des avalanches petites à moyennes (taille 1 à 2). Ponctuellement, un départ linéaire de grande taille est possible (taille 3), notamment dans les orientations est et ouest, où l'humidification pourrait atteindre pour la première fois les couches fragiles enfouies à la base du manteau neigeux.

Déclenchements provoqués : * de rares plaques résiduelles persistent en altitude, dans les accumulations de neige transportée par les derniers épisodes de vent fort. À noter que leur déclenchement peut être facilité par l'humidification des couches superficielles en cours de journée (structure de plaque en neige froide enfouie sous la neige humide de surface). Avalanches petites à moyennes (taille 1 à 2).
* Un skieur évoluant tardivement dans une pente raide ayant trop chauffé peut provoquer un départ de neige humide sous ses skis.

Qualité de la neige

L'enneigement est proche des normales ou légèrement déficitaire pour un début avril. Hauteurs de neige observées : 149 cm en versant nord du col Izoard à 2300 m, 142 cm au-dessus de St Véran à 2700 m, 90 cm à la Nivôse du Col Agnel à 2630 m

Limite d'enneigement skiable : au plus bas à 1500/1600 m en ubacs bien protégés ou sur pistes forestières, plutôt 2000/2200 m en adrets.

État de la neige de surface : excepté dans les ubacs de haute altitude (> 2500/2700 m), neige en cycle printanier partout ailleurs : petite croûte plus ou moins portante en début de journée, puis rapide humidification au soleil. Dans les ubacs raides de haute altitude, neige encore froide, durcie ou travaillée par le vent dans les secteurs exposés, mais encore assez légère dans les combes ou pentes abritées. Sur les crêtes, d'épaisses corniches côtoient des zones pelées par le vent.

Aperçu météo pour le lundi 06 avril

Le voile nuageux d'altitude s'évacue en cours de matinée et laisse place à une journée bien ensoleillée et particulièrement douce. 12/15 °C vers 2000 m l'après-midi.

Pluie-Neige	nuit	matin	après-midi	soir
Iso 0 °C	3 100 m	3 100 m	3 100 m	3 200 m
Vent 2000 m	10 km/h	10 km/h	20 km/h	5 km/h
Vent 3000 m	30 km/h	20 km/h	20 km/h	20 km/h

Épaisseur de neige hors-piste

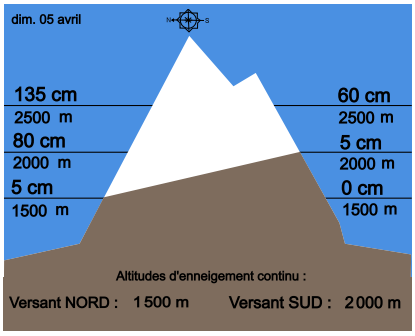

Précipitations à 1800 m

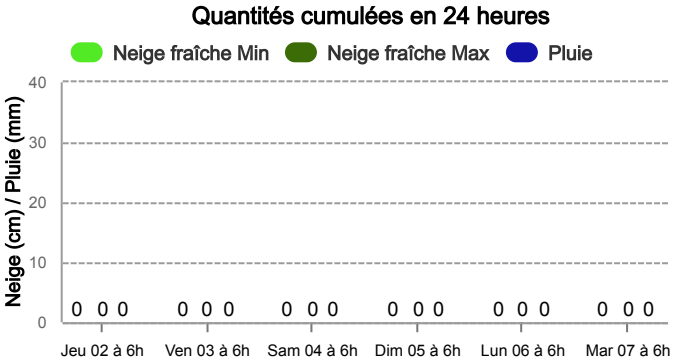

Tendance du mardi 07 avril

2 **Indice de risque limité**

L'activité avalancheuse en neige humide reprend à nouveau en cours de journée, provoquant ponctuellement des avalanches de grande taille, parfois sous forme de départs linéaires.
Le danger gagne des altitudes de plus en plus élevées.

Pour consulter la vigilance en cours, veuillez vous rendre sur le site https://vigilance.meteofrance.fr/fr

Météo-France - 73 avenue de Paris, 94165 Saint-Mandé cedex - Contact : contact@meteo.fr

Rédigé par Météo-France avec la contribution des observateurs du réseau nivo-météorologiques. Partenariat : ANMSM (Maires de Stations de Montagne), DSF (Domaines Skiables de France), ADSP (Directeurs de Pistes et de la Sécurité des Stations de Sports d'Hiver) et autres acteurs de la montagne.

Bulletin neige & avalanches par téléphone au 0 892 68 10 20 Service 0,35 € / min + prix appel

RÉPUBLIQUE FRANÇAISE
Liberté Égalité Fraternité

METEO FRANCE
À VOS CÔTÉS, DANS UN CLIMAT QUI CHANGE

Bulletin d'estimation du risque d'avalanche
(valable en dehors des pistes balisées et ouvertes)

MASSIF : Queyras

Rédigé le dimanche 5 avril 2026 à 16h

Conditions nivo-météo des 7 derniers jours

	lun. 30/03				mar. 31/03				mer. 01/04				jeu. 02/04				ven. 03/04				sam. 04/04				dim. 05/04			
	03h	09h	15h	21h	03h	09h	15h	21h	03h	09h	15h	21h	03h	09h	15h	21h	03h	09h	15h	21h	03h	09h	15h	21h	03h	09h	15h	21h
Météo																												
Vent (km/h)	30	50	80	90	80	70	60	40	40	40	50	50	35	15	15	15	15	20	20	10	15	10	15	10	15	20	30	30
à 3000m																												
Vent (km/h)	15	40	70	80	70	50	35	30	30	30	40	40	20	15	25	15	10	15	20	10	10	10	15	5	5	10	25	10
à 2000m																												

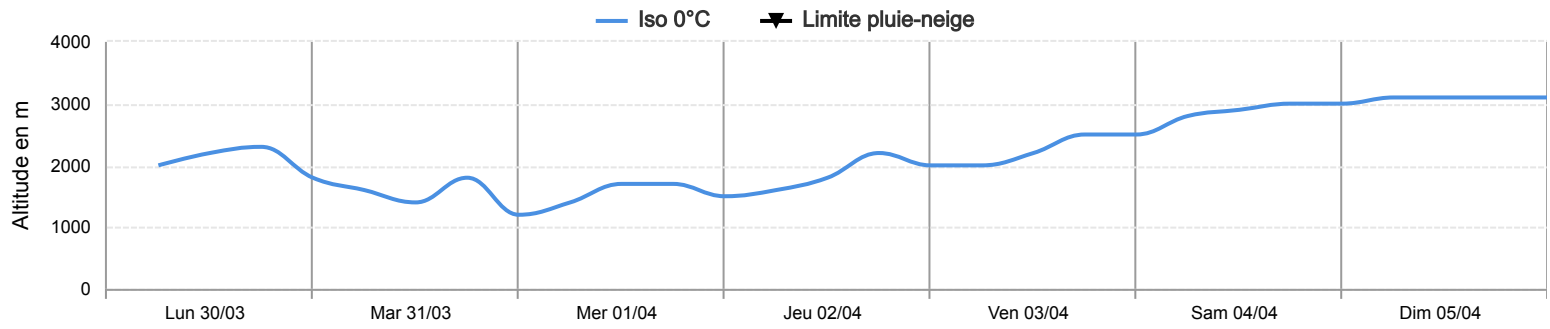

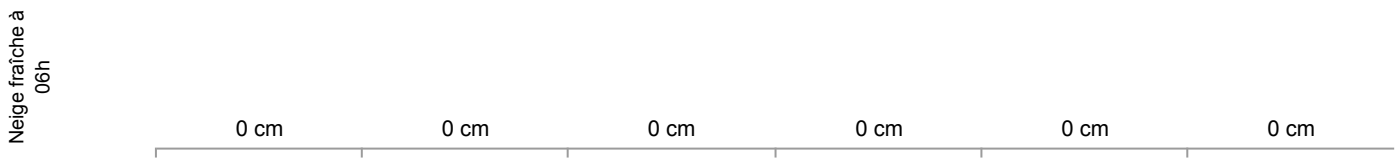

Risque d'avalanche	lun. 30/03	mar. 31/03	mer. 01/04	jeu. 02/04	ven. 03/04	sam. 04/04	dim. 05/04
	2	2	2	2	2	2	2

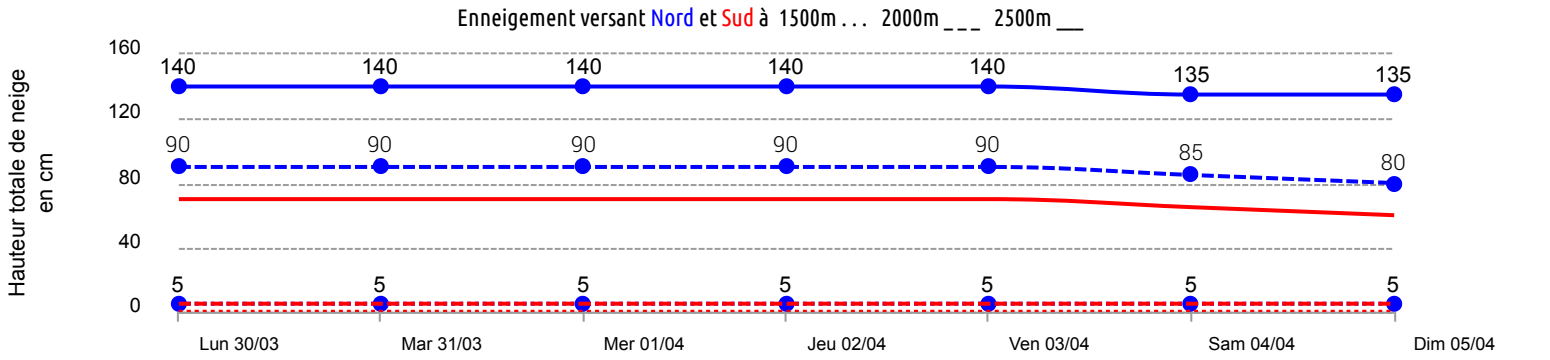

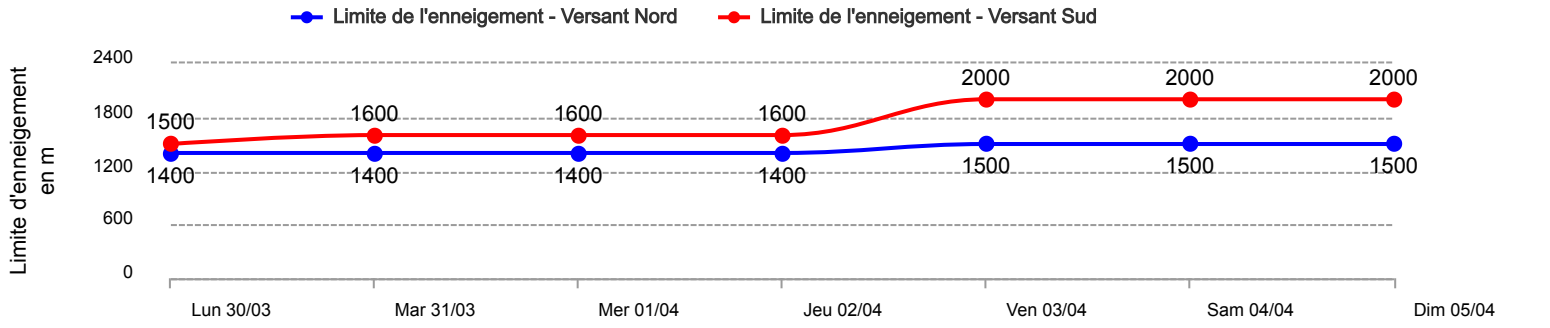

Pour consulter la vigilance en cours, veuillez vous rendre sur le site https://vigilance.meteofrance.fr/fr

Météo-France - 73 avenue de Paris, 94165 Saint-Mandé cedex - Contact : contact@meteo.fr

Rédigé par Météo-France avec la contribution des observateurs du réseau nivo-météorologiques. Partenariat : ANMSM (Maires de Stations de Montagne), DSF (Domaines Skiables de France), ADSP (Directeurs de Pistes et de la Sécurité des Stations de Sports d'Hiver) et autres acteurs de la montagne.

Bulletin neige & avalanches par téléphone au

0 892 68 10 20 Service 0,35 € / min + prix appel