Bulletin d'estimation du risque d'avalanche

(valable en dehors des pistes balisées et ouvertes)

MASSIF : Renoso Incudine

Rédigé le dimanche 5 avril 2026 à 16h

Estimation des risques pour le : LUNDI 06 AVRIL

DÉPARTS EN NEIGE HUMIDE EN JOURNÉE

1

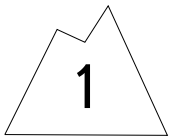

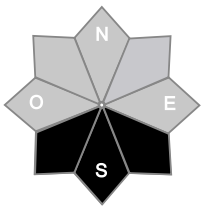

Indice de risque faible.

Départs spontanés : Coulées de neige humide dans les pentes raides durant les heures les plus chaudes de la journée

Déclenchements provoqués : Très rares plaques à vent pouvant persister en altitude, difficiles à solliciter

Indices de risque : 5 très fort - 4 fort - 3 marqué - 2 limité - 1 faible -- En noir : les pentes les plus dangereuses

Stabilité du manteau neigeux

Situation avalancheuse typique : pas de situation prédominante

Départs spontanés : Avec la hausse des températures et le généreux ensoleillement, des départs en neige humide sont attendus durant la journée, surtout en versants raides bien ensoleillés, au fil de la course du soleil. En haute altitude, une avalanche de taille moyenne n'est pas exclue.
Déclenchements provoqués : Aux heures les plus chaudes de la journée, un skieur coupant une pente raide peut déclencher une coulée de neige humide. De fines plaques à vent peuvent aussi persister en versants ombragés en haute altitude, mais elles deviennent difficiles à solliciter.
Autres : Présence de corniches, susceptibles de rompre à cause des conditions printanières. Persistance de surfaces dures et glacées, pouvant être recouvertes de quelques centimètres de neige récente humide.

Qualité de la neige

Qualification de l'enneigement : L'enneigement est excellent pour la saison au-dessus de 1600 m et même excédentaire. À Ghisoni Capanelle, on estime encore 2m50 à localement plus de 3m00 dans les combes abritées.
Limite d'enneigement skiable : 1500 à 1600 m.
État de la neige : Évolution progressive vers une neige de printemps en toutes orientations. En Nord en haute altitude, il reste quelques surfaces de neige sèche, souvent dure, dans les rares pentes raides qui restent ombragées. Ailleurs, l'humidification gagne en profondeur tandis que le regel nocturne est moins efficace. Toutefois, les surfaces dures peuvent être fréquentes le matin en altitude. Dans les orientations Sud, le manteau neigeux est généralement humidifié sur toute son épaisseur, au moins jusqu'à 2200 m. En moyenne montagne, la croûte de regel est quasiment inexistante le matin, alors que la neige devient molle voire pourrie l'après-midi.

Aperçu météo pour le lundi 06 avril

nuit	matin	après-midi	soir

Beau temps, printanier. Isotherme zéro degré au-dessus de 3000m, températures élevées.

Pluie-Neige				
Iso 0 °C	3 100 m	3 100 m	3 200 m	3 300 m
Vent 1500 m	→ 20 km/h	→ 20 km/h	→ 20 km/h	→ 25 km/h
Vent 2000 m	→ 20 km/h	→ 20 km/h	→ 20 km/h	→ 25 km/h

Épaisseur de neige hors-piste

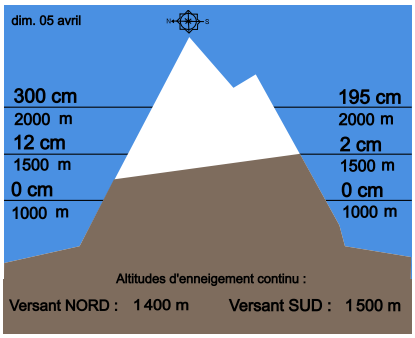

Précipitations à 1800 m

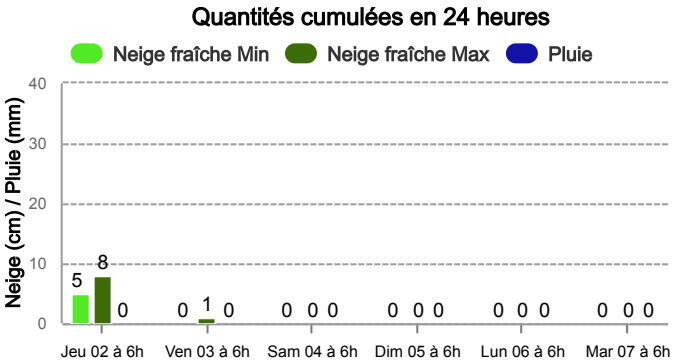

Tendance du mardi 07 avril

1

Indice de risque faible

Durant la journée, coulées de neige humide ou départs sous les skis dans les pentes raides. Maintien d'un risque faible.

Pour consulter la vigilance en cours, veuillez vous rendre sur le site https://vigilance.meteofrance.fr/fr

Météo-France - 73 avenue de Paris, 94165 Saint-Mandé cedex - Contact : contact@meteo.fr

Rédigé par Météo-France avec la contribution des observateurs du réseau nivo-météorologiques. Partenariat : ANMSM (Maires de Stations de Montagne), DSF (Domaines Skiables de France), ADSP (Directeurs de Pistes et de la Sécurité des Stations de Sports d'Hiver) et autres acteurs de la montagne.

Bulletin neige & avalanches par téléphone au

0 892 68 10 20 Service 0,35 € / min + prix appel

Bulletin d'estimation du risque d'avalanche

(valable en dehors des pistes balisées et ouvertes)

MASSIF : Renoso Incudine

Rédigé le dimanche 5 avril 2026 à 16h

Conditions nivo-météo des 7 derniers jours

	lun. 30/03				mar. 31/03				mer. 01/04				jeu. 02/04				ven. 03/04				sam. 04/04				dim. 05/04			
	03h	09h	15h	21h	03h	09h	15h	21h	03h	09h	15h	21h	03h	09h	15h	21h	03h	09h	15h	21h	03h	09h	15h	21h	03h	09h	15h	21h
Météo																												
Vent (km/h)	30	15	30	40	45	70	60	90	110	95	60	70	90	55	60	60	60	50	40	25	30	40	25	20	20	15	10	10
à 2000m																												
Vent (km/h)	35	15	40	35	15	75	40	60	70	75	25	50	60	45	40	40	40	30	30	20	15	25	20	15	15	10	10	10
à 1500m																												

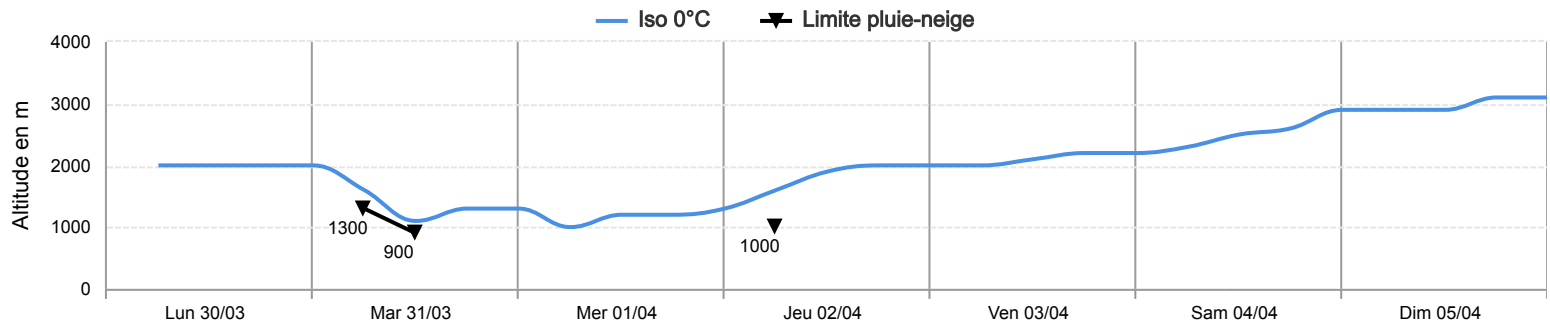

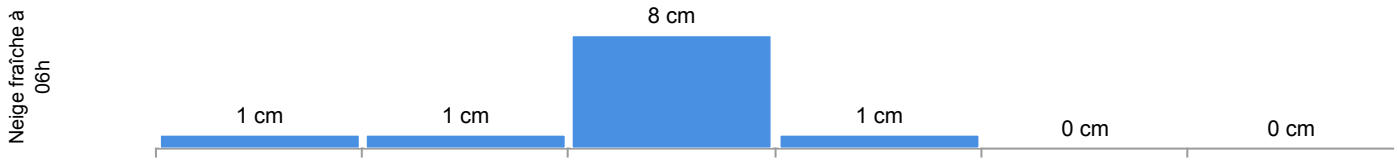

Risque d'avalanche	lun. 30/03	mar. 31/03	mer. 01/04	jeu. 02/04	ven. 03/04	sam. 04/04	dim. 05/04
	2	2	2	2	1	1	1

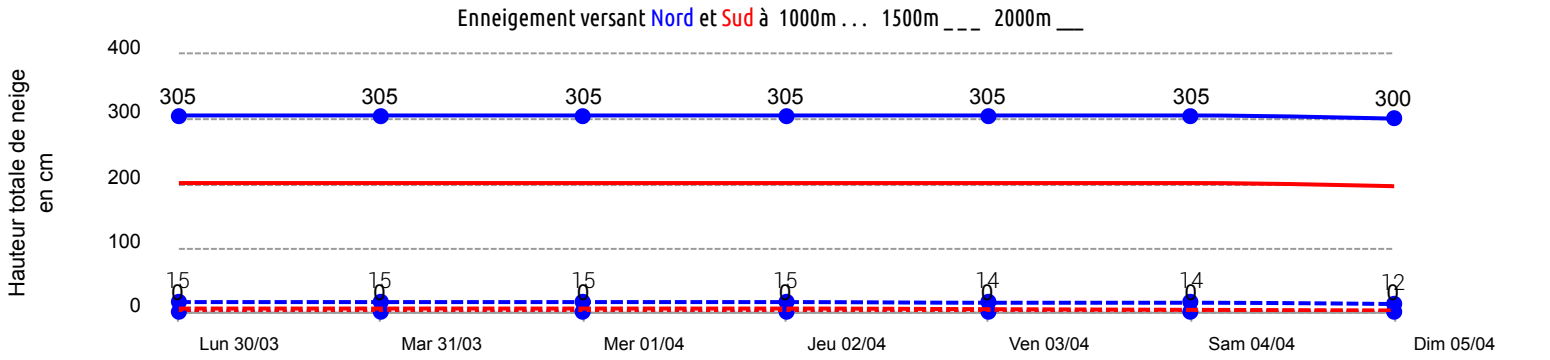

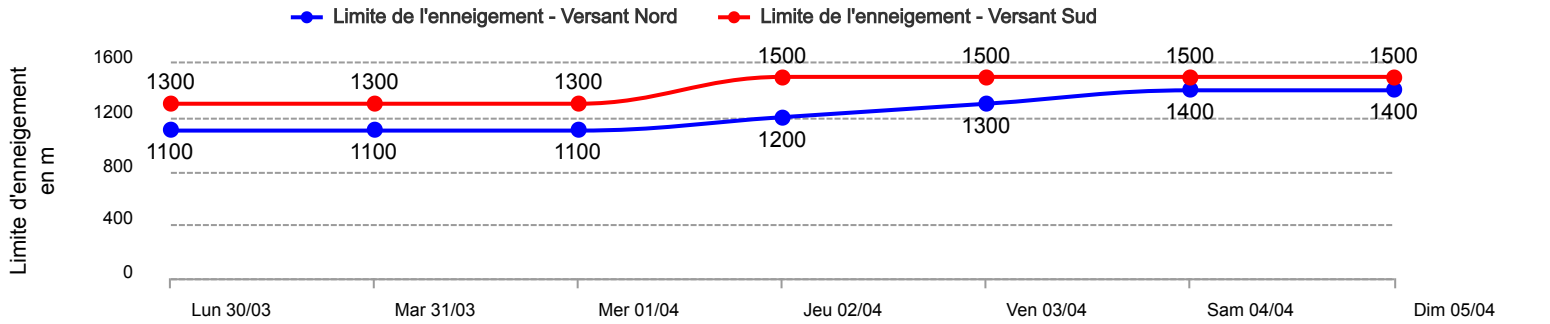

Pour consulter la vigilance en cours, veuillez vous rendre sur le site https://vigilance.meteofrance.fr/fr

Météo-France - 73 avenue de Paris, 94165 Saint-Mandé cedex - Contact : contact@meteo.fr

Rédigé par Météo-France avec la contribution des observateurs du réseau nivo-météorologiques. Partenariat : ANMSM (Maires de Stations de Montagne), DSF (Domaines Skiables de France), ADSP (Directeurs de Pistes et de la Sécurité des Stations de Sports d'Hiver) et autres acteurs de la montagne.

Bulletin neige & avalanches par téléphone au

0 892 68 10 20 Service 0,35 € / min + prix appel