GOBIERNO DE ESPAÑA
VICEPRESIDENCIA TERCERA DEL GOBIERNO
MINISTERIO PARA LA TRANSICIÓN ECOLÓGICA Y EL RETO DEMOGRÁFICO

Boletín de información nivológica y de peligro de aludes

Pirineo Catalán

aemet Agencia Estatal de Meteorología

lunes, 6 de abril de 2026

Pronóstico hasta las 24 horas del martes, día 7 de abril

(Válido fuera de pistas de esquí balizadas y abiertas)

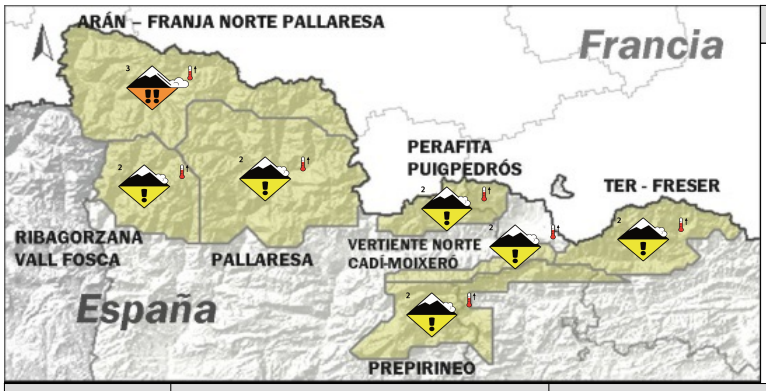

Problemas de aludes

Nieve húmeda

Placas de viento

Macizo	Peligro	Problemas de aludes, cota, orientación, tamaño	Innivación observada (m)
Arán - Franja norte Pallaresa	3 / 3 / 2 / 2400 Notable	Nieve húmeda: 2 Placas de viento: 2 / 2400	2026-04-06 N / S Cota más baja caras N
Ribagorzana - Vall Fosca	2 / 2 Limitado	Nieve húmeda: 2 Placas de viento: 2 / 2400	2026-04-06 N / S Cota más baja caras N
Pallaresa	2 / 2 Limitado	Nieve húmeda: 2 Placas de viento: 2 / 2400	2026-04-06 N / S Cota más baja caras N

AEMET. Se autoriza la reproducción de su contenido citando la fuente.

Boletín de información nivológica y de peligro de aludes

Pirineo Catalán

Perafita - Puigpedrós	2 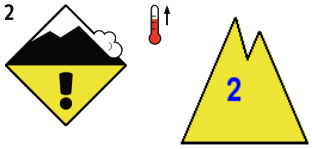 **Limitado**	**Nieve húmeda** 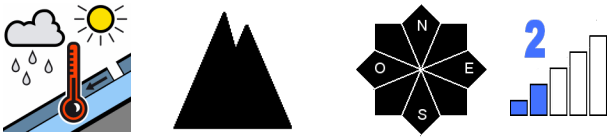 **Placas de viento** 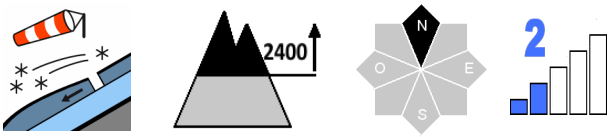	2026-04-06 Cota más baja caras N	
Ter - Freser	2 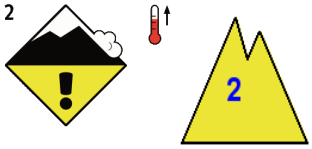 **Limitado**	**Nieve húmeda** **Placas de viento** 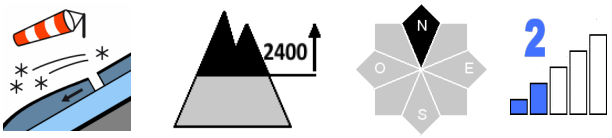	2026-04-06 Cota más baja caras N	
Vertiente norte Cadí - Moixeró	2 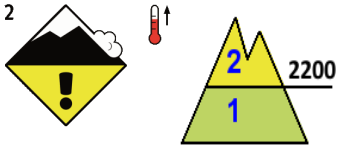 **Limitado**	**Nieve húmeda**  **Placas de viento** 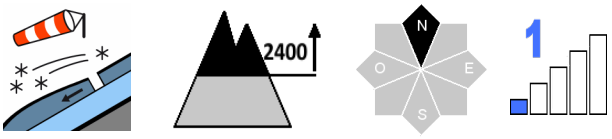	2026-04-06 Cota más baja caras N	
Prepirineo	2 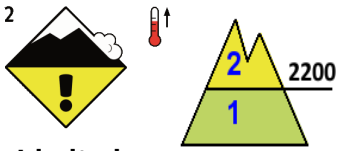 **Limitado**	**Nieve húmeda** 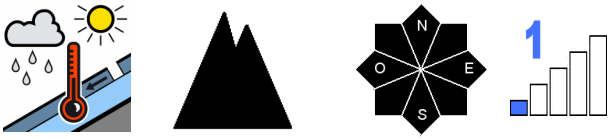	2026-04-06 Cota más baja caras N	

Estado del manto y observaciones recientes

El ambiente cálido y la abundante insolación están propiciando la humidificación y compactación del manto, con pérdidas medias de unos 5-10 cm cada día, así como la progresiva estabilización de las placas de viento. Procesos que van a seguir produciéndose durante las próximas jornadas.

Como consecuencia, la cubierta nivosa ha ido retrocediendo a altitudes más elevadas, siendo continua a partir de unos 1700 metros en umbrías y 1900 metros en solanas, algo más abajo en el Arán y la Franja Norte Pallaresa. Con todo, los espesores se sitúan muy por encima de lo habitual para estas fechas, rondando los 120-220 cm a unos 2200-2400 metros en el Arán y alcanzando los 70-170 cm en el resto, valores que se pueden superar en ventisqueros y otras zonas propensas a la acumulación.

AEMET. Se autoriza la reproducción de su contenido citando la fuente.

En general, el manto está húmedo y presenta perfil primaveral, sobre todo en las solanas, aunque en cotas altas la humidificación afecta principalmente a los estratos más superficiales. Las placas de viento formadas recientemente han tendido a estabilizarse, pero todavía pueden quedar activas en las altas umbrías, donde también persisten algunas capas débiles a distintas profundidades que podrían mostrar cierta reactividad.

Evolución del manto y peligro de aludes para el martes, día 7

Problema de nieve húmeda y deslizamientos basales. Problema de placas de viento en umbrías de cotas altas.

Mañana, martes, el rehielo será poco efectivo, aunque aún podrían formarse algunas costras que sustenten el manto a primeras horas. No obstante, la nieve se encontrará mayoritariamente blanda, por lo que serán frecuentes los aludes de nieve húmeda, más probables en solanas y a partir del mediodía, incluso se podrán producir deslizamientos basales en terrenos herbosos o de roca lisa. Por lo general, serán pequeños (riesgo de caída) o medianos (capaz de enterrar a una persona), sin descartar que alguno pudiera alcanzar un tamaño algo mayor.

Las placas de viento ubicadas en umbrías de cotas altas todavía podrán mantenerse frágiles y ceder ante una sobrecarga generalmente fuerte, solo en algún caso podrían fracturar al paso de un esquiador. Los aludes así provocados serán de tamaño mediano, o raramente grande (capaz de enterrar un vehículo) en las zonas de mayor acumulación o si se ve afectada alguna capa débil persistente situada a cierta profundidad.

Predicción meteorológica para el martes, día 7

Poco nuboso o despejado, con algún intervalo de nubes altas. Temperaturas sin cambios, o mínimas en ligero ascenso. Algunas heladas débiles en las cumbres de mayor altitud. Viento flojo o moderado de componente sur.

Datos en la atmósfera libre:

Altitud de la isoterma de 0 ºC: 3400 m
Altitud de la isoterma de -10 ºC: 4800 m

Viento a 1500 m: S 15 km/h
Viento a 3000 m: S 20 km/h

Evolución para el miércoles día 8

Se mantendrán los problemas de nieve húmeda y deslizamientos basales. Las placas de viento seguirán estabilizándose.

Escala europea de peligro de aludes

Débil | Limitado | Notable | Fuerte | Muy Fuerte

Problemas de aludes

Nieve reciente | Placas de viento | Capas débiles persistentes | Nieve húmeda | Deslizamientos basales | Sin problema evidente

AEMET. Se autoriza la reproducción de su contenido citando la fuente.

Nota1: Se recuerda que, siempre que haya nieve, la ausencia total de peligro no existe. Hay que tener presente que en circunstancias desfavorables, con aludes de tamaño 1 (alud pequeño o colada) y tamaño 2 (alud mediano), se pueden sufrir severos daños personales.

Nota2: Los BPA se elaboran en base a información meteorológica así como al estado del manto nivoso a través de sondeos puntuales. Se advierte a los usuarios de la variabilidad de esta información al extrapolarla a zonas extensas de montaña. Por ello, AEMET no se hace responsable de su uso para la toma de decisiones que conciernen a la seguridad personal, ni de los riesgos físicos o materiales de ellas derivadas.

AEMET. Se autoriza la reproducción de su contenido citando la fuente.