GOBIERNO DE ESPAÑA
VICEPRESIDENCIA TERCERA DEL GOBIERNO
MINISTERIO PARA LA TRANSICIÓN ECOLÓGICA Y EL RETO DEMOGRÁFICO

Boletín de información nivológica y de peligro de aludes

Pirineo Navarro y Aragonés

aemet Agencia Estatal de Meteorología

lunes, 6 de abril de 2026

Pronóstico hasta las 24 horas del martes, día 7 de abril

(Válido fuera de pistas de esquí balizadas y abiertas)

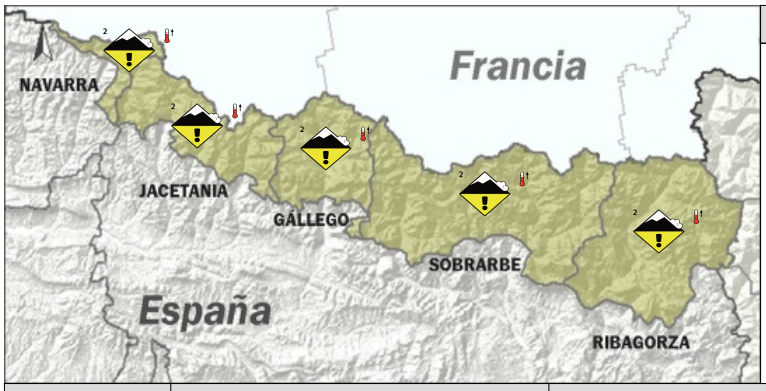

Problemas de aludes

Nieve húmeda

Placas de viento

Macizo	Peligro	Problemas de aludes, cota, orientación, tamaño	Innivación observada (m)
Navarra	2 — 2 — Limitado	Nieve húmeda: N, O, E, S — 2 Placas de viento: 2300 — N, O, E, S — 2	2026-04-06 N / S Cota más baja caras N
Jacetania	2 — 2 — Limitado	Nieve húmeda: N, O, E, S — 2 Placas de viento: 2400 — N, O, E, S — 2	2026-04-06 N / S Cota más baja caras N
Gállego	2 — 2 — Limitado	Nieve húmeda: N, O, E, S — 2 Placas de viento: 2400 — N, O, E, S — 2	2026-04-06 N / S Cota más baja caras N

AEMET. Se autoriza la reproducción de su contenido citando la fuente.

Boletín de información nivológica y de peligro de aludes

Pirineo Navarro y Aragonés

Sobrarbe	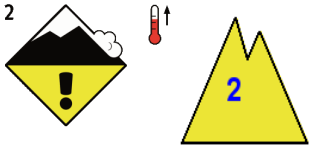 **Limitado**	**Nieve húmeda** 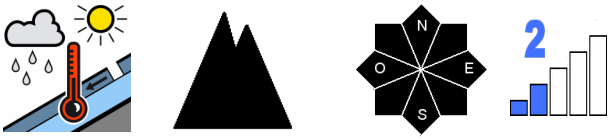 **Placas de viento** 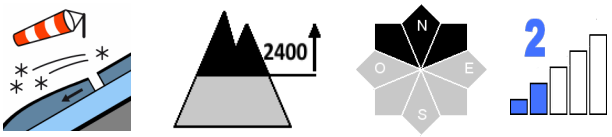	2026-04-06 Cota más baja caras N
Ribagorza	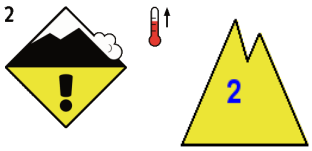 **Limitado**	**Nieve húmeda** **Placas de viento** 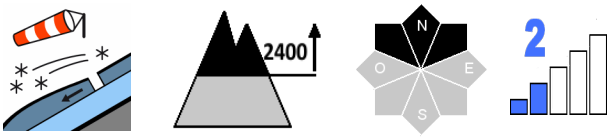	2026-04-06 Cota más baja caras N

Estado del manto y observaciones recientes

El ambiente cálido y la abundante insolación están propiciando la humidificación y compactación del manto, con pérdidas medias de unos 5-10 cm cada día, así como la progresiva estabilización de las placas de viento. Procesos que van a seguir produciéndose durante las próximas jornadas.

Como consecuencia, la cubierta nivosa ha ido retrocediendo a altitudes más elevadas, siendo continua a partir de unos 1700-1900 metros, con clara disimetría entre solanas y umbrías, si bien en cotas inferiores aún se puede encontrar nieve en algunas áreas dispersas. Con todo, los espesores se sitúan por encima de lo que sería habitual para estas fechas, rondando los 75-150 cm a 2000-2200 metros, valores que se pueden superar en ventisqueros y otras zonas propensas a la acumulación.

En general, el manto está húmedo y presenta perfil primaveral, sobre todo en las solanas, aunque en cotas altas la humidificación afecta principalmente a los estratos más superficiales. Las placas de viento formadas recientemente han tendido a estabilizarse, pero todavía pueden quedar activas en las altas umbrías, donde también persisten algunas capas débiles a distintas profundidades que podrían mostrar cierta reactividad.

Evolución del manto y peligro de aludes para el martes, día 7

Problema de nieve húmeda y deslizamientos basales. Problema de placas de viento en umbrías de cotas altas.

Mañana, martes, el rehielo será poco efectivo, aunque aún podrían formarse algunas costras que sustenten el manto a primeras horas. No obstante, la nieve se encontrará mayoritariamente blanda, por lo que serán frecuentes los aludes de nieve húmeda, más probables en solanas y a partir del mediodía, incluso se podrán producir deslizamientos

AEMET. Se autoriza la reproducción de su contenido citando la fuente.

basales en terrenos herbosos o de roca lisa. Por lo general, serán pequeños (riesgo de caída) o medianos (capaz de enterrar a una persona), sin descartar que alguno pudiera alcanzar un tamaño algo mayor.

El flujo del sur podría formar algunas placas de viento en vertientes norte, sobre todo en el macizo navarro, que se sumarían a las que todavía se mantienen frágiles en umbrías de cotas altas. Generalmente estas estructuras podrán ceder ante una sobrecarga fuerte, solo en algún caso podrían fracturar al paso de un solo esquiador, provocando aludes de tamaño mediano, o raramente grande (capaz de enterrar un vehículo) en las zonas de mayor acumulación o si se ve afectada alguna capa débil persistente situada a cierta profundidad.

Predicción meteorológica para el martes, día 7

Poco nuboso o despejado con nubes altas, y algún intervalo de nubes medias. Temperaturas sin cambios, o mínimas en ligero ascenso. Algunas heladas débiles en las cumbres de mayor altitud. Viento moderado de componente sur, con intervalos fuertes a primeras y últimas horas en el sector navarro.

Datos en la atmósfera libre:

Altitud de la isoterma de 0 ºC: 3400 m
Altitud de la isoterma de -10 ºC: 4700 m

Viento a 1500 m: S 40 km/h (Navarra) - SE 20 km/h (Aragón)
Viento a 3000 m: S 30 km/h

Evolución para el miércoles día 8

Se mantendrán los problemas de nieve húmeda y deslizamientos basales. Las placas de viento seguirán estabilizándose.

(Información elaborada a partir de los datos recibidos de los refugios de Linza, Lizara, Panticosa, Bachimaña, Góriz, Pineta, Estós y Angel Orús, de la estación de esquí de Astún y de Ordesa Pradera)

Escala europea de peligro de aludes

Débil | Limitado | Notable | Fuerte | Muy Fuerte

Problemas de aludes

Nieve reciente | Placas de viento | Capas débiles persistentes | Nieve húmeda | Deslizamientos basales | Sin problema evidente

Nota1: Se recuerda que, siempre que haya nieve, la ausencia total de peligro no existe. Hay que tener presente que en circunstancias desfavorables, con aludes de tamaño 1 (alud pequeño o colada) y tamaño 2 (alud mediano), se pueden sufrir severos daños personales.

Nota2: Los BPA se elaboran en base a información meteorológica así como al estado del manto nivoso a través de sondeos puntuales. Se advierte a los usuarios de la variabilidad de esta información al extrapolarla a zonas extensas de montaña. Por ello, AEMET no se hace responsable de su uso para la toma de decisiones que conciernen a la seguridad personal, ni de los riesgos físicos o materiales de ellas derivadas.

AEMET. Se autoriza la reproducción de su contenido citando la fuente.